壁に貼ったとき　上の段：1・3・5、下の段：2・4（1の下に2、3の下に4）

目の高さ1.5 m

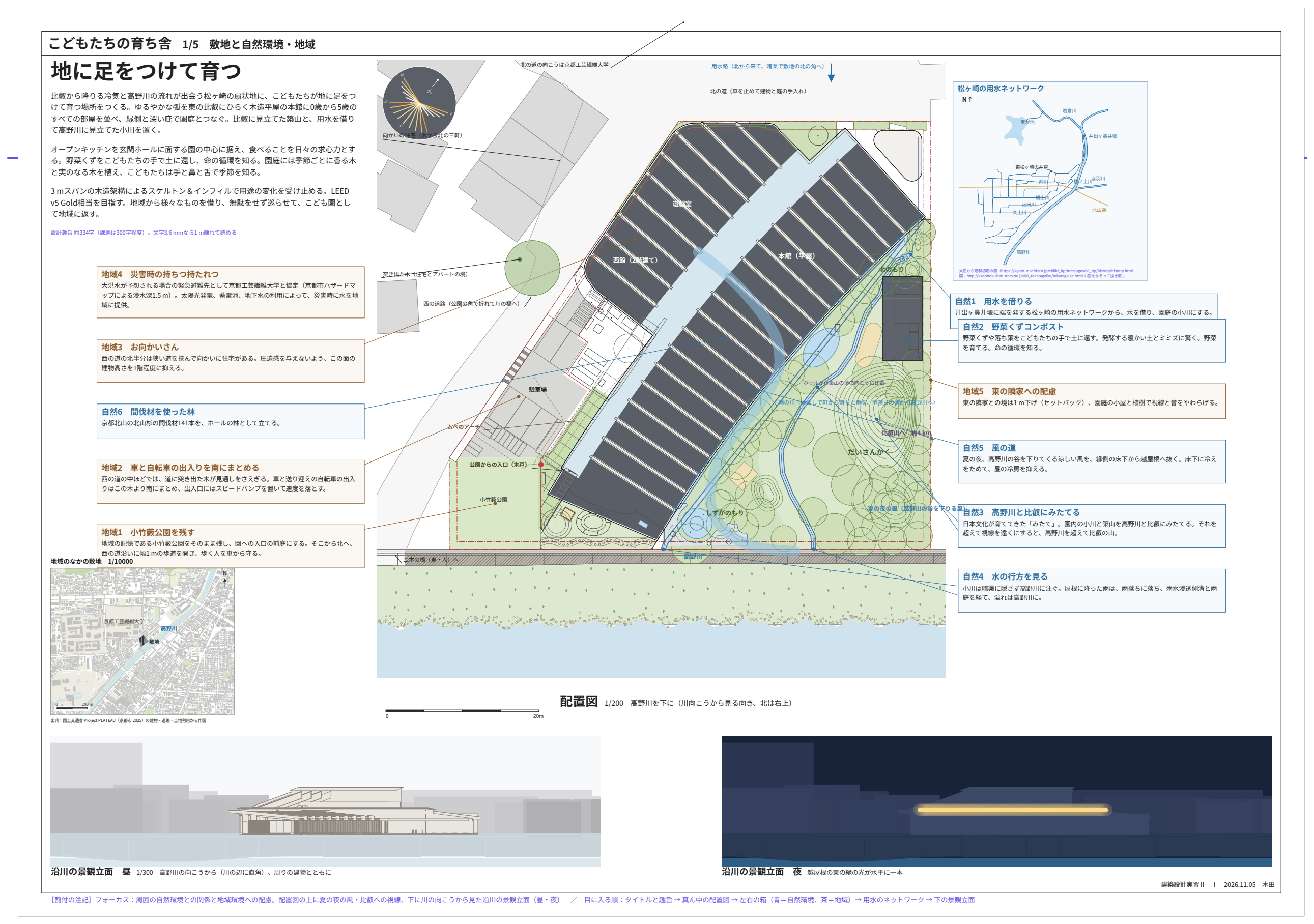

こどもたちの育ち舎 1/5　敷地と自然環境・地域

地に足をつけて育つ

比叡から降りる冷気と高野川の流れが出会う松ヶ崎の扇状地に、こどもたちが地に足をつけて育つ場所をつくる。ゆるやかな弧を東の比叡にひらく木造平屋の本館に0歳から5歳のすべての部屋を並べ、縁側と深い庇で園庭とつなぐ。比叡に見立てた築山と、用水を借りて高野川に見立てた小川を置く。

オープンキッチンを玄関ホールに面する園の中心に据え、食べることを日々の求心力とする。野菜くずをこどもたちの手で土に還し、命の循環を知る。園庭には季節ごとに香る木と実のなる木を植え、こどもたちは手と鼻と舌で季節を知る。

3 mスパンの木造架構によるスケルトン＆インフィルで用途の変化を受け止める。LEED v5 Gold相当を目指す。地域から様々なものを借り、無駄をせず巡らせて、こども園として地域に返す。

地域4　災害時の持ちつ持たれつ
大洪水が予想される場合の緊急避難先として京都工芸繊維大学と協定（京都市ハザードマップによる浸水深1.5 m）。太陽光発電、蓄電池、地下水の利用によって、災害時に水を地域に提供。

地域3　お向かいさん
西の道の北半分は狭い道を挟んで向かいに住宅がある。圧迫感を与えないよう、この面の建物高さを1階程度に抑える。

自然6　間伐材を使った林
京都北山の北山杉の間伐材141本を、ホールの林として立てる。

地域2　車と自転車の出入りを南にまとめる
西の道の中ほどでは、道に突き出た木が見通しをさえぎる。車と送り迎えの自転車の出入りはこの木より南にまとめ、出入口にはスピードバンプを置いて速度を落とす。

地域1　小竹藪公園を残す
地域の記憶である小竹藪公園をそのまま残し、園への入口の前庭にする。そこから北へ、西の道沿いに幅1 mの歩道を開き、歩く人を車から守る。

自然1　用水を借りる
井出ヶ鼻井堰に端を発する松ヶ崎の用水ネットワークから、水を借り、園庭の小川にする。

自然2　野菜くずコンポスト
野菜くずや落ち葉をこどもたちの手で土に還す。発酵する暖かい土とミミズに驚く。野菜を育てる。命の循環を知る。

地域5　東の隣家への配慮
東の隣家との境は1 m下げ（セットバック）、園庭の小屋と植樹で視線と音をやわらげる。

自然5　風の道
夏の夜、高野川の谷を下りてくる涼しい風を、縁側の床下から越屋根へ抜く。床下に冷えをためて、昼の冷房を抑える。

自然3　高野川と比叡にみたてる
日本文化が育ててきた「みたて」。園内の小川と築山を高野川と比叡にみたてる。それを超えて視線を遠くにすると、高野川を超えて比叡の山。

自然4　水の行方を見る
小川は暗渠に隠さず高野川に注ぐ。屋根に降った雨は、雨落ちに落ち、雨水浸透側溝と雨庭を経て、溢れは高野川に。

松ヶ崎の用水ネットワーク

地域のなかの敷地　1/10000

配置図　1/200　高野川を下に（川向こうから見る向き、北は右上）

沿川の景観立面　昼　1/300　高野川の向こうから（川の辺に直角）、周りの建物とともに

沿川の景観立面　夜　越屋根の東の縁の光が水平に一本

建築設計実習 II－I　2026.11.05　木田

［割付の注記］フォーカス：周囲の自然環境との関係と地域環境への配慮。配置図の上に夏の夜の風・比叡への視線。下に川の向こうから見た沿川の景観立面（昼・夜）　／　目に入る順：タイトルと趣旨 → 真ん中の配置図 → 左右の箱（青＝自然環境、茶＝地域）→ 用水のネットワーク → 下の景観立面

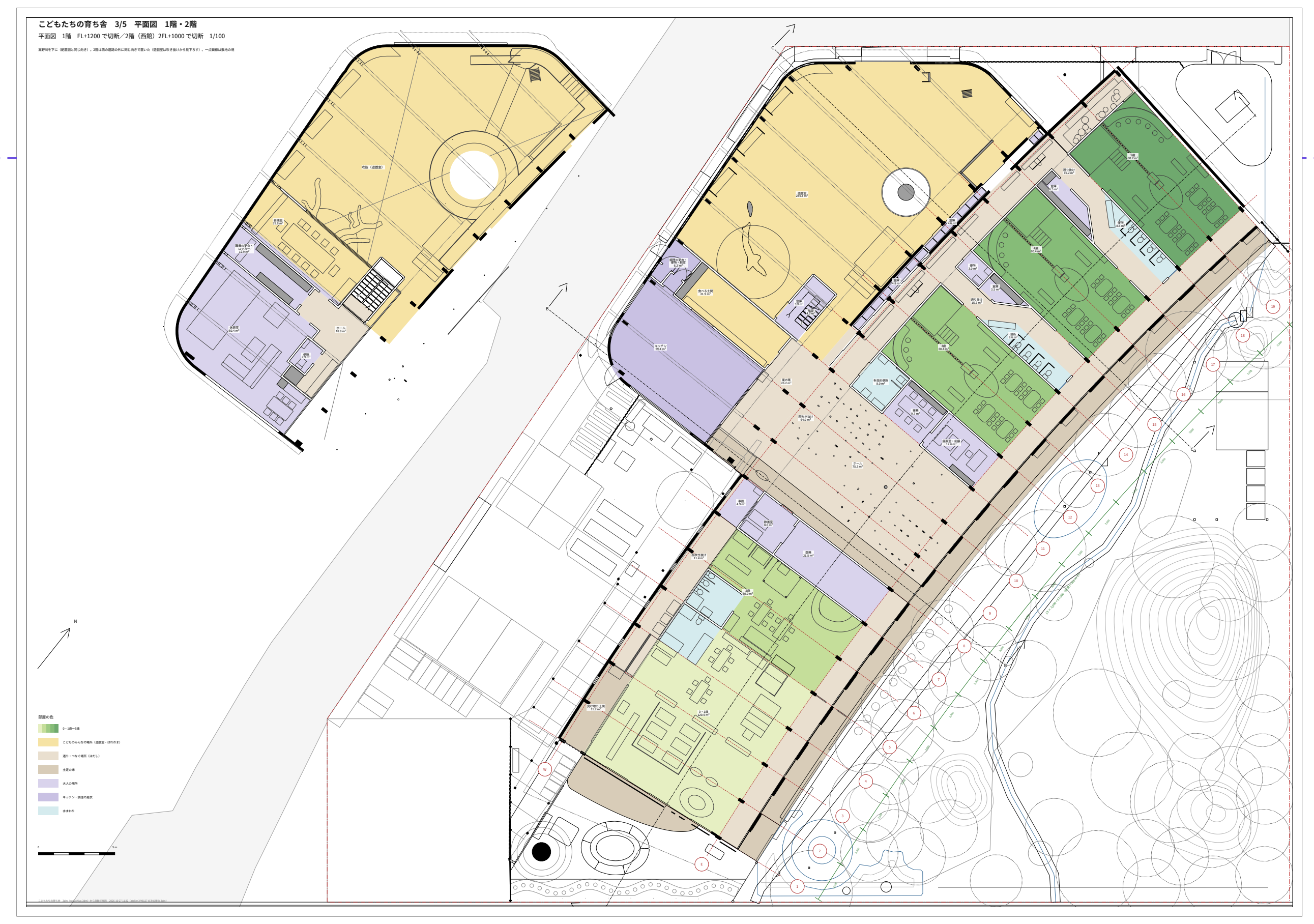

こどもたちの育ち舎 3/5　平面図　1階・2階

平面図　1階　FL+1200 で切断／2階（西館）2FL+1000 で切断　1/100

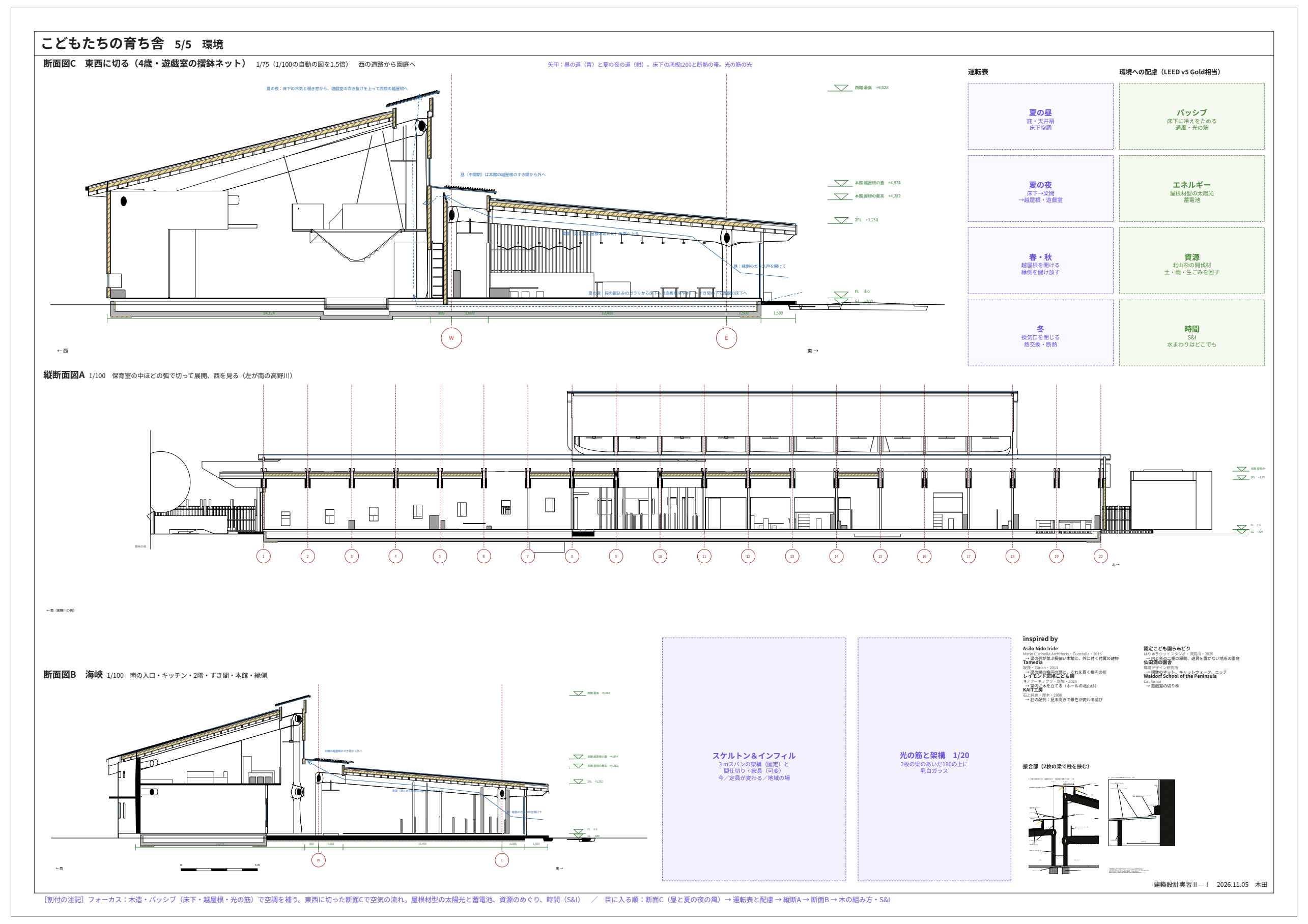

こどもたちの育ち舎 5/5　環境

断面図C　東西に切る（4歳・遊戯室の擂鉢ネット）　1/75（1/100の自動の図を1.5倍）　西の道路から園庭へ

運転表

夏の昼 庇・天井扇 床下空調	パッシブ 床下に冷えをためる 通風・光の筋
夏の夜 床下→梁間 →越屋根・遊戯室	エネルギー 屋根材型の太陽光 蓄電池
春・秋 越屋根を開ける 縁側を開け放す	資源 北山杉の間伐材 土・雨・生ごみを回す
冬 換気口を閉じる 熱交換・断熱	時間 S&I 水まわりはどこでも

環境への配慮（LEED v5 Gold相当）

縦断面図A　1/100　保育室の中ほどの弧で切って展開、西を見る（左が南の高野川）

断面図B　海峡　1/100　南の入口・キッチン・2階・すき間・本館・縁側

スケルトン＆インフィル
3 mスパンの架構（固定）と
間仕切り・家具（可変）
今／定員が変わる／地域の場

光の筋と架構　1/20
2枚の梁のあいだ180の上に
乳白ガラス

inspired by

接合部（2枚の梁で柱を挟む）

建築設計実習 II－I　2026.11.05　木田



こどもたちの育ち舎 2/5　景観

園庭の側の立面図　1/100　円弧の中心の方向から弧の真ん中に正対

伸びやかな梁と縁側（梁の端・庇が3 mごとに並ぶ）。屋根は屋根材型の太陽光

道路の側の立面図　1/100　西の道路から

西館の西端は1階の高さ（向かいの住宅）。西館の立ち上がりが北で主張する

模型写真　鳥瞰
配置図と同じ向き（高野川を手前）
川側が低く北へ高くなる流れが見える角度で

景観の約束
第一種低層住居専用地域。西館の棟は約8.5 m（GLから）。

高野川特別修景地域（右岸）：河岸の樹木と清流が一体の水と緑の空間。川に面する側に植栽帯（園庭の林と生垣）。川に面する側に勾配のある下屋（南の深い軒）。深い軒と縁側、杉の大和張りの板壁（無塗装、銀鼠に枯れる）。ゆるい勾配の屋根——これをいまの和風の外観とする。

遠景デザイン保全区域（高野川・修学院離宮・船岡山公園からの眺め）：外壁と屋根に禁止色を使わず、山並みと調和する色（黒い金属の屋根、木の色のまま）。

小竹藪公園と既存の木を残す。

素材と色
- 木の柱・梁（木の色のまま）
- 杉の大和張りの外壁（銀鼠に枯れる）
- 屋根：黒い金属（屋根材型の太陽光）
- 越屋根のガラスの蓋・縁側の白
- 生垣と園庭の緑

建築設計実習 II－I　2026.11.05　木田

［割付の注記］フォーカス：建物に正対する二つの立面（園庭の側・道路の側）で、伸びやかな梁と縁側、西館の立ち上がり。沿川の景観立面（昼・夜）は1枚目の下　／　目に入る順：園庭の側・道路の側の立面図 → 鳥瞰 → 景観の約束 → 素材と色

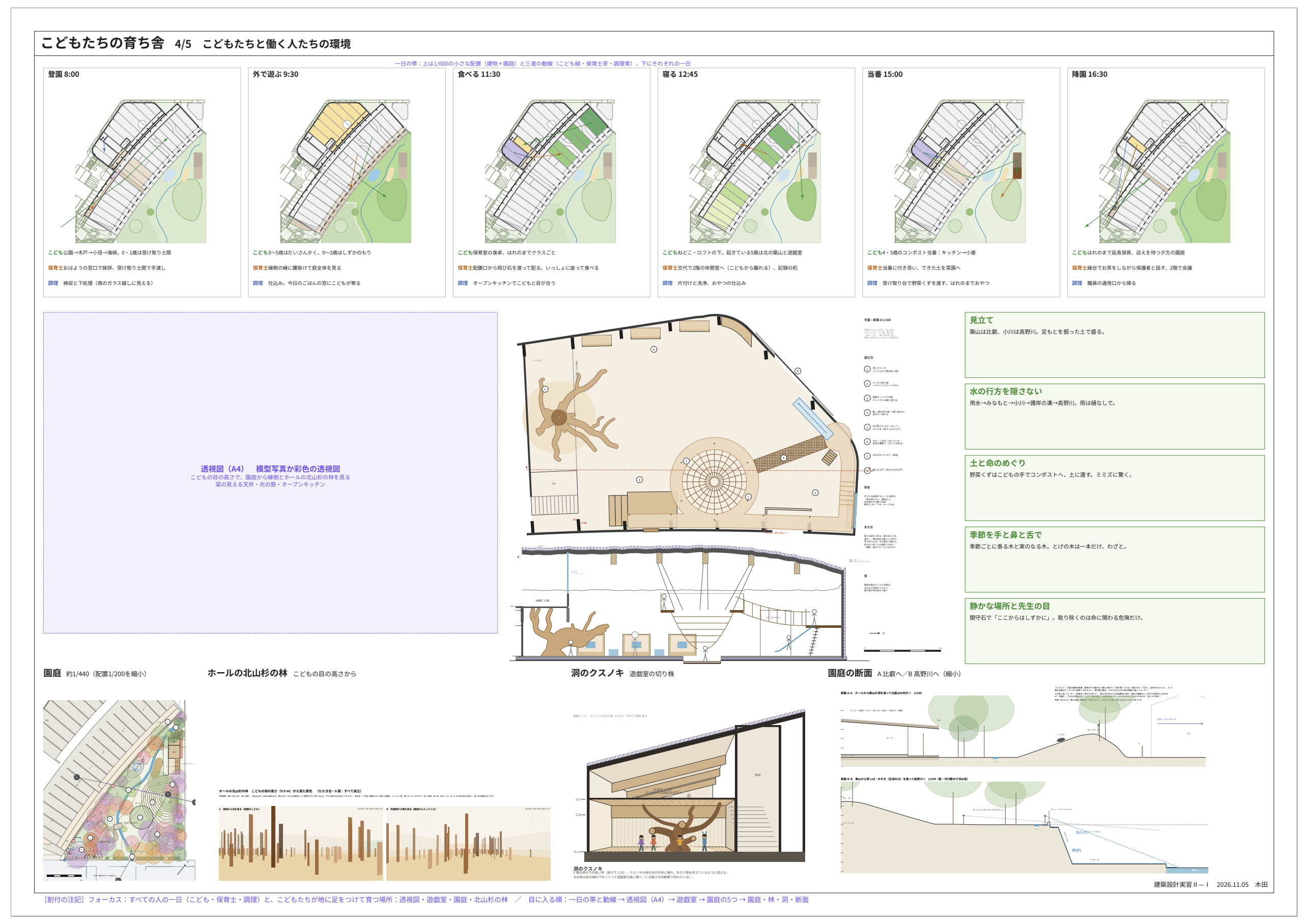

こどもたちの育ち舎 4/5　こどもたちと働く人たちの環境

登園 8:00　外で遊ぶ 9:30　食べる 11:30　寝る 12:45　当番 15:00　降園 16:30

透視図（A4）　模型写真か彩色の透視図

見立て
築山は比叡、小川は高野川。足もとを掘った土で盛る。

水の行方を隠さない
雨水→みなもと→小川→護岸の溝→高野川。雨は樋なしで。

土と命のめぐり
野菜くずはこどもの手でコンポストへ。土に還す。ミミズに驚く。

季節を手と鼻と舌で
季節ごとに香る木と実のなる木。とげの木は一本だけ、わざと。

静かな場所と先生の目
関守石で「ここからはしずかに」。取り除くのは命に関わる危険だけ。

園庭　約1/440（配置1/200を縮小）

ホールの北山杉の林　こどもの目の高さから

洞のクスノキ　遊戯室の切り株

園庭の断面　A 比叡へ／B 高野川へ（縮小）

建築設計実習 II－I　2026.11.05　木田

［割付の注記］フォーカス：すべての人の一日（こども・保育士・調理）と、こどもたちが地に足をつけて育つ場所：透視図・遊戯室・園庭・北山杉の林　／　目に入る順：一日の帯と動線 → 透視図（A4）→ 遊戯室 → 園庭の5つ → 園庭・林・洞・断面

1 敷地と自然環境・地域 → 下に 2 景観（立面図）。

1の配置図の右に 3 平面図、その下に 4 こどもたちと働く人たちの環境（一日の帯は平面図の真下）。

3の右に 5 環境（断面図）。

2・3・5枚目の平面・立面・断面は3dmから自動の図を実寸で貼る。

床