壁に貼ったとき　3列：1 ｜ 2・3 ｜ 4・5（1は二段の真ん中）

目の高さ1.5 m

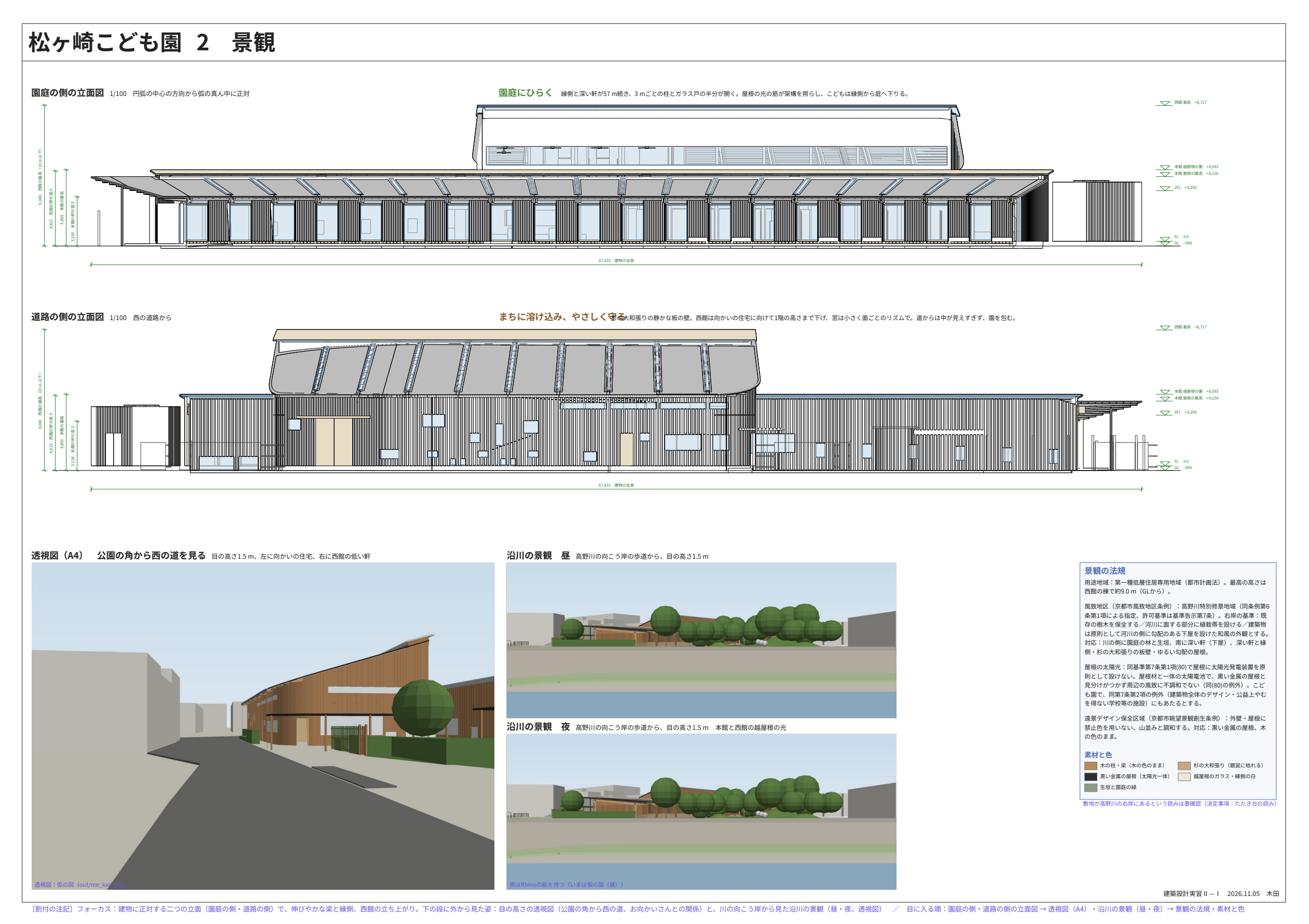

松ヶ崎こども園 2　景観

園庭の側の立面図　1/100　円弧の中心の方向から弧の真ん中に正対

園庭にひらく

道路の側の立面図　1/100　西の道路から

まちに溶け込み、やさしく守る

透視図（A4）　公園の角から西の道を見る　目の高さ1.5 m、左に向かいの住宅、右に西館の低い軒

沿川の景観　昼　高野川の向こう岸の歩道から、目の高さ1.5 m

沿川の景観　夜　高野川の向こう岸の歩道から、目の高さ1.5 m　本館と西館の越屋根の光

景観の法規

素材と色

建築設計実習 II－I　2026.11.05　木田

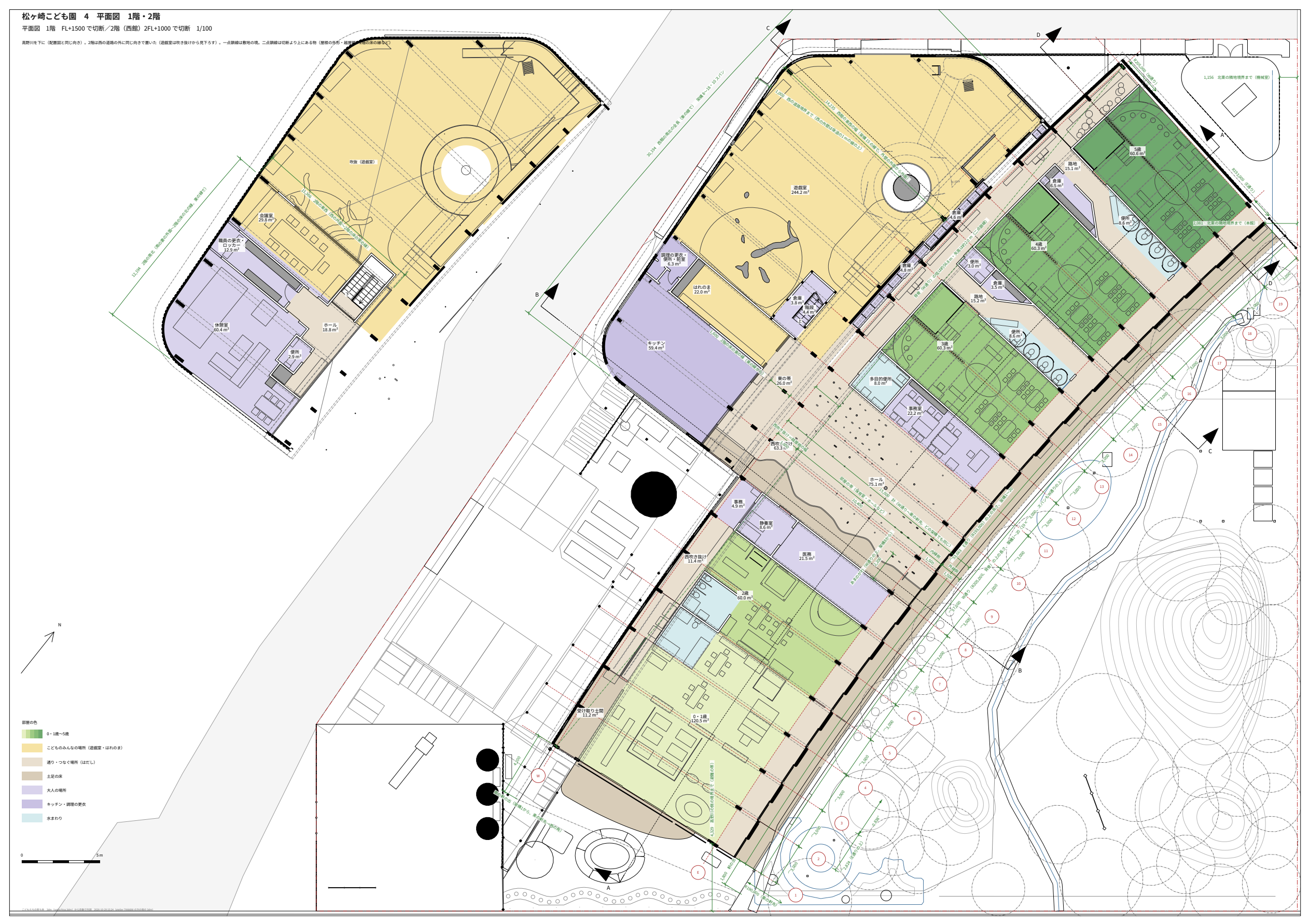

松ヶ崎こども園 4　平面図　1階・2階

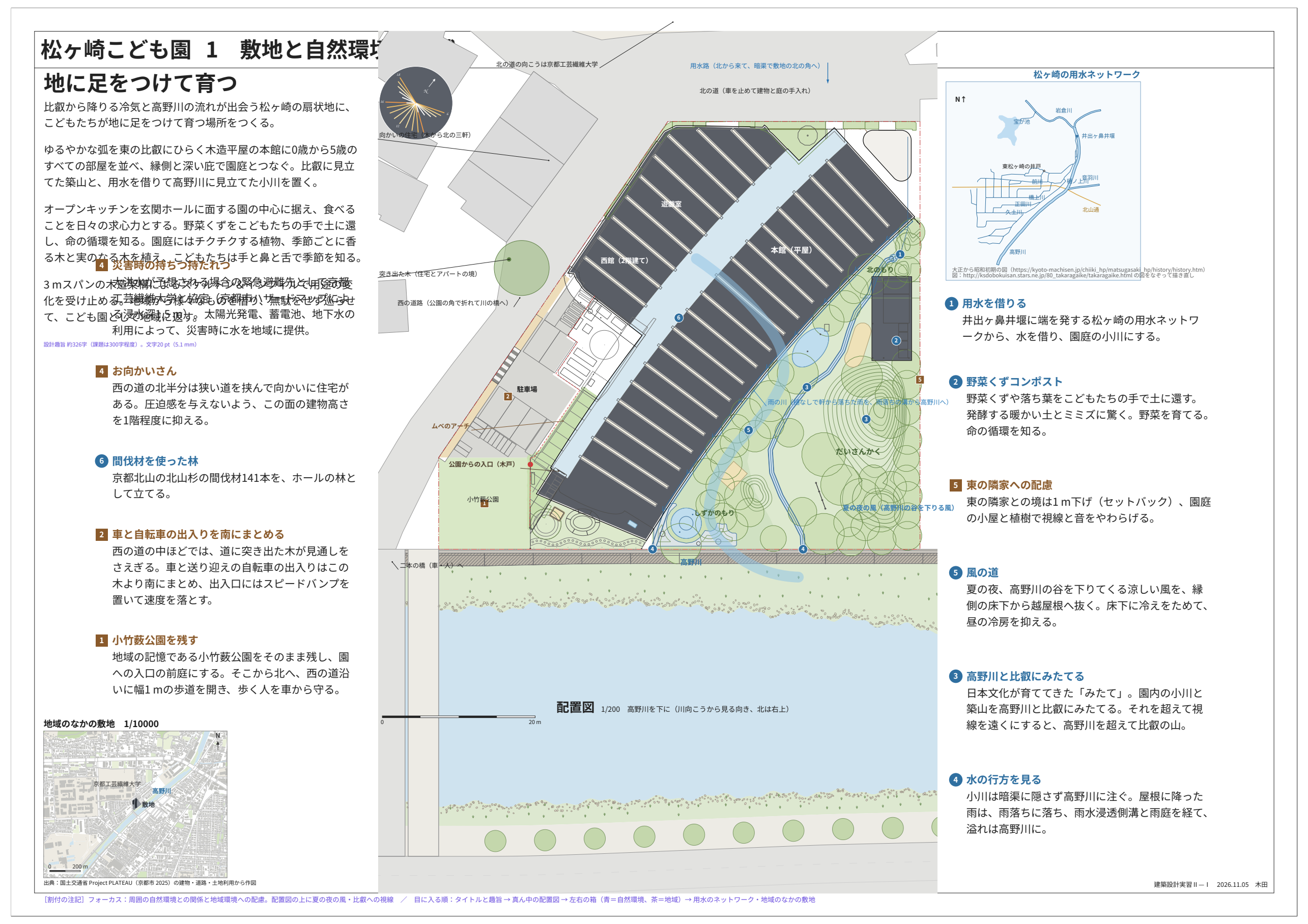

松ヶ崎こども園 1　敷地と自然環境

地に足をつけて育つ

比叡から降りる冷気と高野川の流れが出会う松ヶ崎の扇状地に、こどもたちが地に足をつけて育つ場所をつくる。

ゆるやかな弧を東の比叡にひらく木造平屋の本館に0歳から5歳のすべての部屋を並べ、縁側と深い庇で園庭とつなぐ。比叡に見立てた築山と、用水を借りて高野川に見立てた小川を置く。

オープンキッチンを玄関ホールに面する園の中心に据え、食べることを日々の求心力とする。野菜くずをこどもたちの手で土に還し、命の循環を知る。園庭にはチクチクする植物、季節ごとに香る木と実のなる木を植え、こどもたちは手と鼻と舌で季節を知る。

4 お向かいさん
西の道の北半分は狭い道を挟んで向かいに住宅がある。圧迫感を与えないよう、この面の建物高さを1階程度に抑える。

6 間伐材を使った林
京都北山の北山杉の間伐材141本を、ホールの林として立てる。

2 車と自転車の出入りを南にまとめる
西の道の中ほどでは、道に突き出た木が見通しをさえぎる。車と送り迎えの自転車の出入りはこの木より南にまとめ、出入口にはスピードバンプを置いて速度を落とす。

1 小竹薮公園を残す
地域の記憶である小竹薮公園をそのまま残し、園への入口の前庭にする。そこから北へ、西の道沿いに幅1 mの歩道を開き、歩く人を車から守る。

地域のなかの敷地　1/10000

出典：国土交通省 Project PLATEAU（京都市 2025）の建物・道路・土地利用から作図

配置図　1/200　高野川を下に（川向こうから見る向き、北は右上）

松ヶ崎の用水ネットワーク

1 用水を借りる
井出ヶ鼻井堰に端を発する松ヶ崎の用水ネットワークから、水を借り、園庭の小川にする。

2 野菜くずコンポスト
野菜くずや落ち葉をこどもたちの手で土に還す。発酵する暖かい土とミミズに驚く。野菜を育てる。命の循環を知る。

5 東の隣家への配慮
東の隣家との境は1 m下げ（セットバック）、園庭の小屋と植樹で視線と音をやわらげる。

5 風の道
夏の夜、高野川の谷を下りてくる涼しい風を、縁側の床下から越屋根へ抜く。床下に冷えをためて、昼の冷房を抑える。

3 高野川と比叡にみたてる
日本文化が育ててきた「みたて」。園内の小川と築山を高野川と比叡にみたてる。それを超えて視線を遠くにすると、高野川を超えて比叡の山。

4 水の行方を見る
小川は暗渠に隠さず高野川に注ぐ。屋根に降った雨は、雨落ちに落ち、雨水浸透側溝と雨庭を経て、溢れは高野川に。

建築設計実習 II－I　2026.11.05　木田

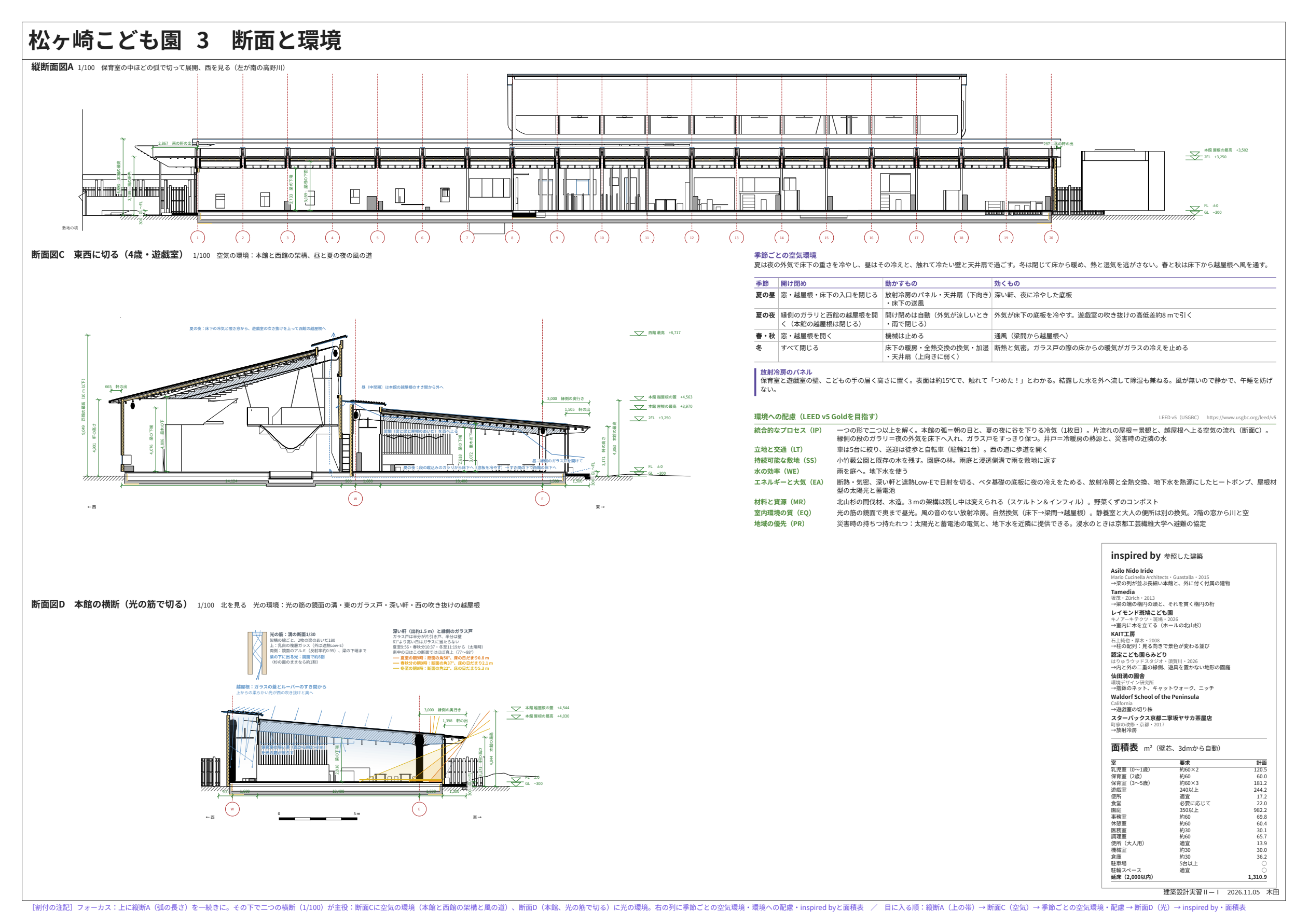

松ヶ崎こども園 3　断面と環境

縦断面図A　1/100

断面図C　東西に切る（4歳・遊戯室）　1/100

断面図D　本館の横断（光の筋で切る）　1/100

季節ごとの空気環境

環境への配慮（LEED v5 Goldを目指す）

inspired by

面積表

建築設計実習 II－I　2026.11.05　木田

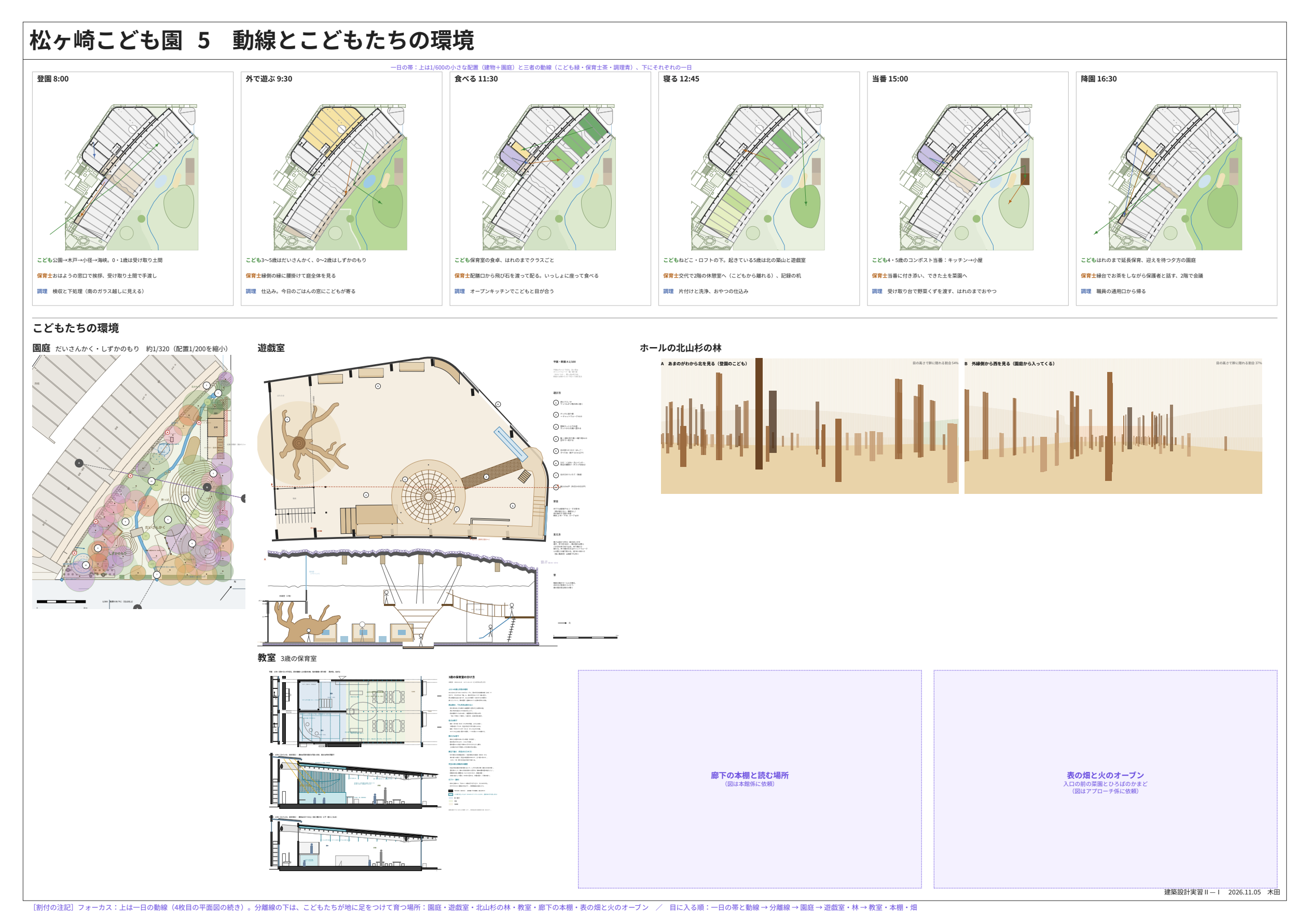

松ヶ崎こども園 5　動線とこどもたちの環境

登園 8:00

外で遊ぶ 9:30

食べる 11:30

寝る 12:45

当番 15:00

降園 16:30

こどもたちの環境

園庭

遊戯室

ホールの北山杉の林

教室　3歳の保育室

廊下の本棚と読む場所

表の畑と火のオーブン

建築設計実習 II－I　2026.11.05　木田

1　敷地と自然環境・地域（二段の真ん中）。

その右に2　景観（立面図1/100、下の段に沿川の景観立面）、その下に3　断面と環境（断面図1/100）。

その右に4　平面図、その下に5　動線とこどもたちの環境（一日の帯は平面図の続き）。

外から中へ：敷地→外から見た姿と切った姿→中の平面と暮らし。

2・3・4枚目の立面・断面・平面は3dmから自動の図を実寸で貼る。

床