壁に貼ったとき　3列：1 ｜ 2・3 ｜ 4・5（1は二段の真ん中）

目の高さ1.5 m

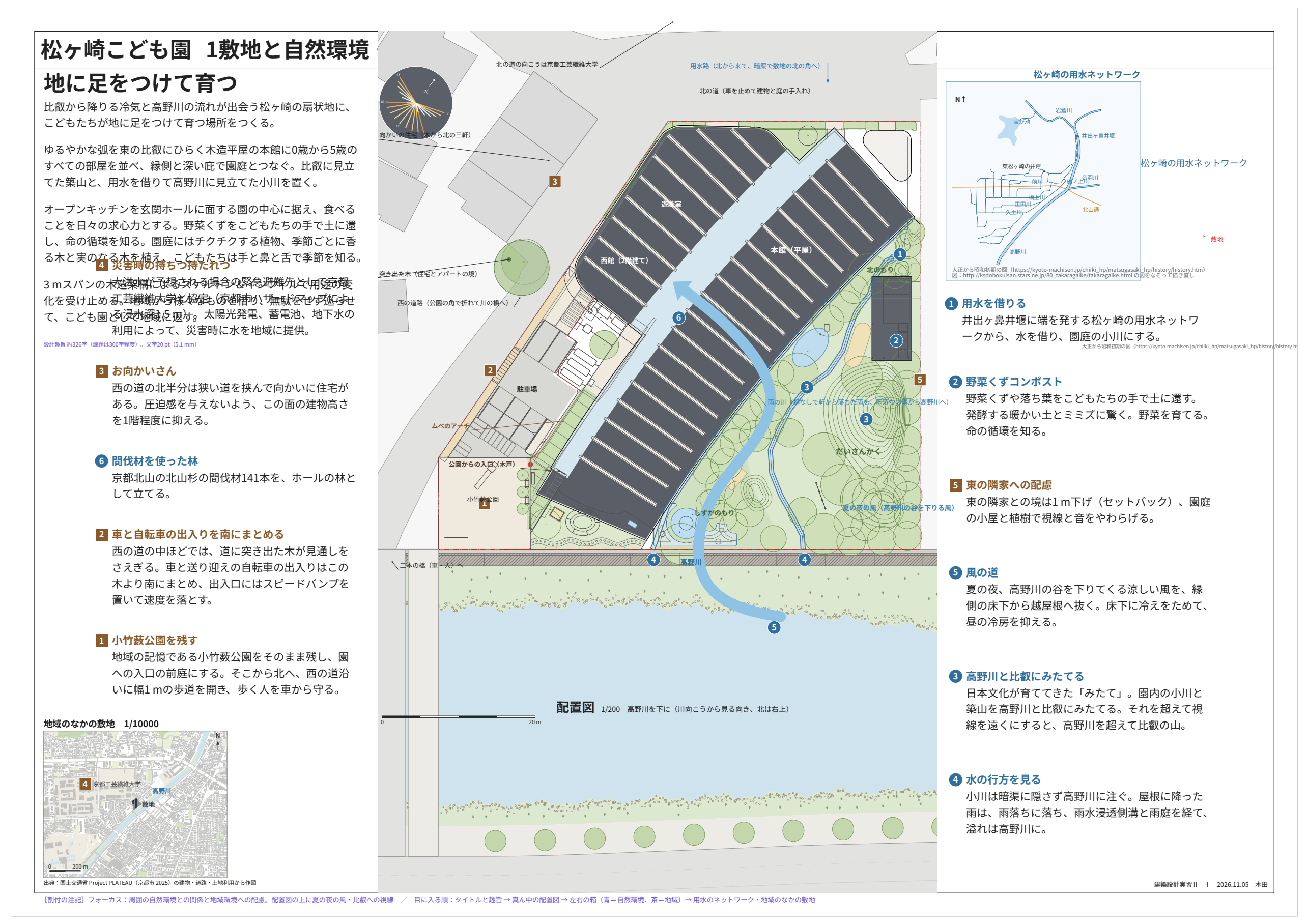

松ヶ崎こども園 1敷地と自然環境

地に足をつけて育つ

比叡から降りる冷気と高野川の流れが出会う松ヶ崎の扇状地に、こどもたちが地に足をつけて育つ場所をつくる。

ゆるやかな弧を東の比叡にひらく木造平屋の本館に0歳から5歳のすべての部屋を並べ、縁側と深い庇で園庭とつなぐ。比叡に見立てた築山と、用水を借りて高野川に見立てた小川を置く。

オープンキッチンを玄関ホールに面する園の中心に据え、食べることを日々の求心力とする。野菜くずをこどもたちの手で土に還し、命の循環を知る。園庭にはチクチクする植物、季節ごとに香る木と実のなる木を植え、こどもたちは手と鼻と舌で季節を知る。

3 mスパンの木造 [illegible]

4 災害時の持ち持たれつ
[illegible] 太陽光発電、蓄電池、地下水の利用によって、災害時に水を地域に提供。

3 お向かいさん
西の道の北半分は狭い道を挟んで向かいに住宅がある。圧迫感を与えないよう、この面の建物高さを1階程度に抑える。

6 間伐材を使った林
京都北山の北山杉の間伐材141本を、ホールの林として立てる。

2 車と自転車の出入りを南にまとめる
西の道の中ほどでは、道に突き出た木が見通しをさえぎる。車と送り迎えの自転車の出入りはこの木より南にまとめ、出入口にはスピードバンプを置いて速度を落とす。

1 小竹薮公園を残す
地域の記憶である小竹薮公園をそのまま残し、園への入口の前庭にする。そこから北へ、西の道沿いに幅1 mの歩道を開き、歩く人を車から守る。

地域のなかの敷地　1/10000

出典：国土交通省 Project PLATEAU（京都市 2025）の建物・道路・土地利用から作図

配置図　1/200　高野川を下に（川向こうから見る向き、北は右上）

松ヶ崎の用水ネットワーク

1 用水を借りる
井出ヶ鼻井堰に端を発する松ヶ崎の用水ネットワークから、水を借り、園庭の小川にする。

2 野菜くずコンポスト
野菜くずや落ち葉をこどもたちの手で土に還す。発酵する暖かい土とミミズに驚く。野菜を育てる。命の循環を知る。

5 東の隣家への配慮
東の隣家との境は1 m下げ（セットバック）、園庭の小屋と植樹で視線と音をやわらげる。

5 風の道
夏の夜、高野川の谷を下りてくる涼しい風を、縁側の床下から越屋根へ抜く。床下に冷えをためて、昼の冷房を抑える。

3 高野川と比叡にみたてる
日本文化が育ててきた「みたて」。園内の小川と築山を高野川と比叡にみたてる。それを超えて視線を遠くにすると、高野川を超えて比叡の山。

4 水の行方を見る
小川は暗渠に隠さず高野川に注ぐ。屋根に降った雨は、雨落ちに落ち、雨水浸透側溝と雨庭を経て、溢れは高野川に。

建築設計実習Ⅱ－Ⅰ　2026.11.05　木田

［割付の注記］フォーカス：周囲の自然環境との関係と地域環境への配慮。配置図の上に夏の夜の風・比叡への視線　／　目に入る順：タイトルと趣旨 → 真ん中の配置図 → 左右の箱（青＝自然環境、茶＝地域）→ 用水のネットワーク・地域のなかの敷地

1　敷地と自然環境・地域（二段の真ん中）。

その右に2　景観（立面図1/100、下の段に沿川の景観立面）、その下に3　断面と環境（断面図1/100）。

その右に4　平面図、その下に5　動線とこどもたちの環境（一日の帯は平面図の続き）。

外から中へ：敷地→外から見た姿と切った姿→中の平面と暮らし。

2・3・4枚目の立面・断面・平面は3dmから自動の図を実寸で貼る。



松ヶ崎こども園 2景観

園庭の側の立面図　1/100　円弧の中心の方向から弧の真ん中に正対

園庭にひらく　縁側と深い軒が57 m続き、3 mごとの柱とガラス戸の半分が開く。屋根の光の筋が架構を照らし、こどもは縁側から庭へ下りる。

道路の側の立面図　1/100　西の道路から

まちに溶け込み、やさしく守る　[illegible] 大和張りの静かな板の壁。西館は向かいの住宅に向けて1階の高さまで下げ、窓は小さく面ごとのリズムで。道からは中が見えすぎず、園を包む。

透視図（A4）　公園の角から西の道を見る　目の高さ1.5 m、左に向かいの住宅、右に西館の低い軒

沿川の景観　昼　高野川の向こう岸の歩道から、目の高さ1.5 m

沿川の景観　夜　高野川の向こう岸の歩道から、目の高さ1.5 m　本館と西館の越屋根の光

景観の法規

用途地域：第一種低層住居専用地域（都市計画法）。最高の高さは西館の棟で約9.0 m（GLから）。

風致地区（京都市風致地区条例）：高野川特別修景地域（同条例第6条第1項による指定、許可基準は基準告示第7条）。右岸の基準：既存の樹木を保全する／河川に面する部分に植栽帯を設ける／建築物は原則として河川の側に勾配のある下屋を設けた和風の外観とする。対応：川の側に園庭の林と生垣、南に深い軒（下屋）、深い軒と縁側・杉の大和張りの板壁・ゆるい勾配の屋根。

屋根の太陽光：同基準第7条第1項(80)で屋根に太陽光発電装置を原則として設けない。屋根材と一体の太陽電池で、黒い金属の屋根と見分けがつかず周辺の風致に不調和でない（同(80)の例外）。こども園で、同第7条第2項の例外（建築物全体のデザイン・公益上やむを得ない学校等の施設）にもあたるとする。

遠景デザイン保全区域（京都市眺望景観創生条例）：外壁・屋根に禁止色を用いない、山並みと調和する。対応：黒い金属の屋根、木の色のまま。

素材と色

- 木の柱・梁（木の色のまま）
- 杉の大和張り（銀鼠に枯れる）
- 黒い金属の屋根（太陽光一体）
- 越屋根のガラス・縁側の白
- 生垣と園庭の緑

敷地が高野川の右岸にあるという読みは要確認（決定事項：たたき台の読み）

建築設計実習Ⅱ－Ⅰ　2026.11.05　木田

［割付の注記］フォーカス：建物に正対する二つの立面（園庭の側・道路の側）で、伸びやかな梁と縁側、西館の立ち上がり。下の段に外から見た姿：目の高さの透視図（公園の角から西の道、お向かいさんとの関係）と、川の向こう岸から見た沿川の景観（昼・夜、透視図）　／　目に入る順：園庭の側・道路の側の立面図 → 透視図（A4）・沿川の景観（昼・夜）→ 景観の法規・素材と色

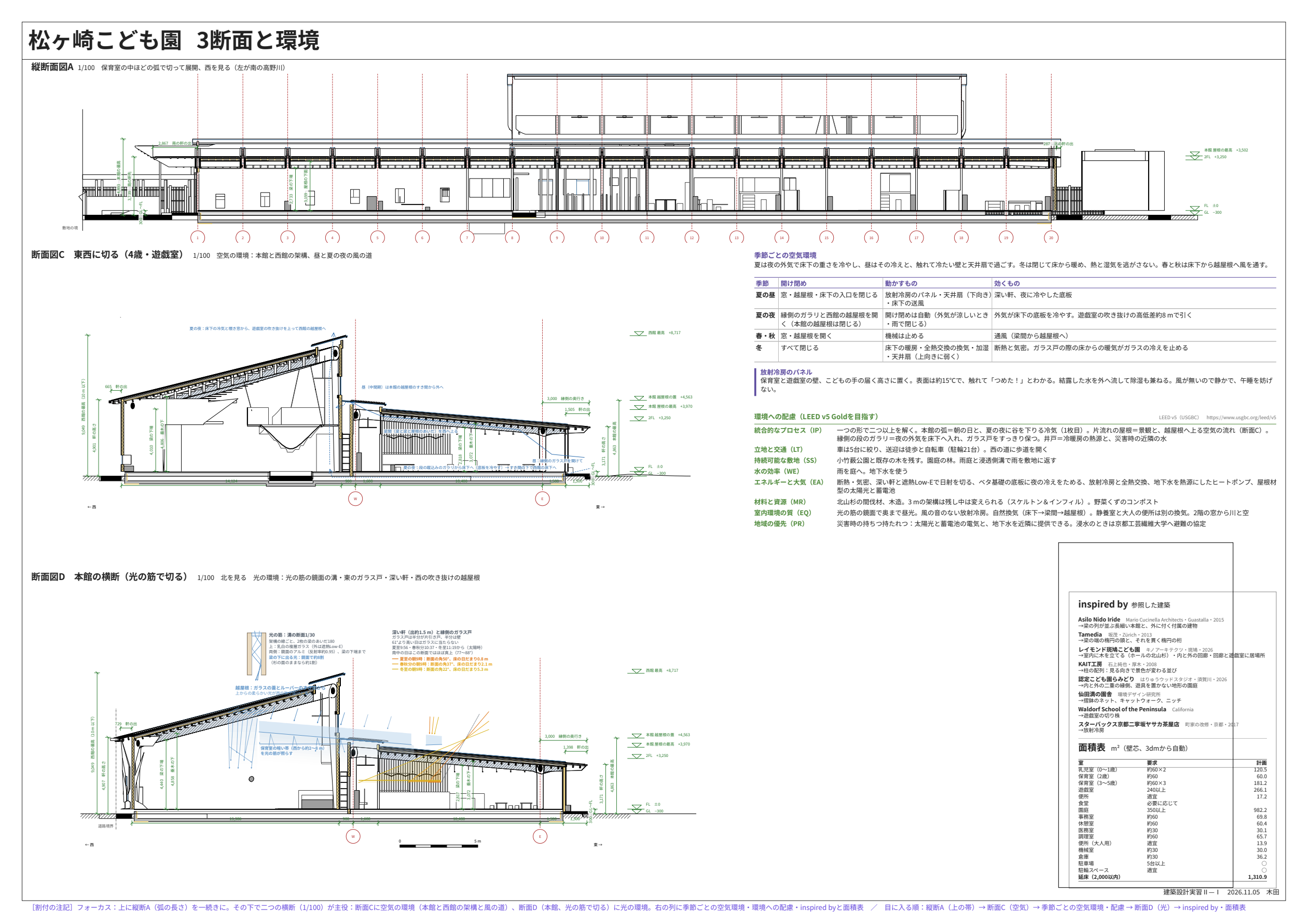

松ヶ崎こども園 3断面と環境

縦断面図A　1/100　保育室の中ほどの弧で切って展開、西を見る（左が南の高野川）

断面図C　東西に切る（4歳・遊戯室）　1/100　空気の環境：本館と西館の架構、昼と夜の風の道

断面図D　本館の横断（光の筋で切る）　1/100　北を見る　光の環境：光の筋の鏡面の溝・東のガラス戸・深い軒・西の吹き抜けの越屋根

季節ごとの空気環境
夏は夜の外気で床下の重さを冷やし、昼はその冷えと、触れて冷たい壁と天井扇で過ごす。冬は閉じて床から暖め、熱と湿気を逃がさない。春と秋は床下から越屋根へ風を通す。

季節	開け閉め	動かすもの	効くもの
夏の昼	窓・越屋根・床下の入口を閉じる	放射冷房のパネル・天井扇（下向き）・床下の送風	深い軒、夜に冷やした底板
夏の夜	縁側のガラリと西館の越屋根を開く（本館の越屋根は閉じる）	開け閉めは自動（外気が涼しいとき・雨で閉じる）	外気が床下の底板を冷やす。遊戯室の吹き抜けの高低差約8 mで引く
春・秋	窓・越屋根を開く	機械は止める	通風（梁間から越屋根へ）
冬	すべて閉じる	床下の暖房・全熱交換の換気・加湿・天井扇（上向きに弱く）	断熱と気密。ガラス戸の際の床からの暖気がガラスの冷えを止める

放射冷房のパネル
保育室と遊戯室の壁、こどもの手の届く高さに置く。表面は約15°Cで、触れて「つめた！」とわかる。結露した水を外へ流して除湿も兼ねる。風が無いので静かで、午睡を妨げない。

環境への配慮（LEED v5 Goldを目指す）　LEED v5（USGBC）　https://www.usgbc.org/leed/v5

統合的なプロセス（IP）	一つの形で二つ以上を解く。本館の弧＝朝の日と、夏の夜に谷を下りる冷気（1枚目）。片流れの屋根＝景観と、越屋根へ上る空気の流れ（断面C）。縁側の段のガラリ＝夜の外気を床下へ入れ、ガラス戸をすっきり保つ。井戸＝冷暖房の熱源と、災害時の近隣の水
立地と交通（LT）	車は5台に絞り、送迎は徒歩と自転車（駐輪21台）。西の道に歩道を開く
持続可能な敷地（SS）	小竹薮公園と既存の木を残す。園庭の林。雨庭と浸透側溝で雨を敷地に返す
水の効率（WE）	雨を庭へ。地下水を使う
エネルギーと大気（EA）	断熱・気密、深い軒と遮熱Low-Eで日射を切る、ベタ基礎の底板に夜の冷えをためる、放射冷房と全熱交換、地下水を熱源にしたヒートポンプ、屋根材型の太陽光と蓄電池
材料と資源（MR）	北山杉の間伐材、木造。3 mの架構は残し中は変えられる（スケルトン＆インフィル）。野菜くずのコンポスト
室内環境の質（EQ）	光の筋の鏡面で奥まで昼光。風の音のない放射冷房。自然換気（床下→梁間→越屋根）。静養室と大人の便所は別の換気。2階の窓から川と空
地域の優先（PR）	災害時の持ちつ持たれつ：太陽光と蓄電池の電気と、地下水を近隣に提供できる。浸水のときは京都工芸繊維大学へ避難の協定

inspired by　参照した建築

Asilo Nido Iride　Mario Cucinella Architects・Guastalla・2015
→梁の列が並ぶ長細い本館と、外に付く付属の建物

Tamedia　坂茂・Zürich・2013
→梁の端の楕円の頭と、それを貫く楕円の桁

レイモンド斑鳩こども園　キノアーキテクツ・斑鳩・2026
→室内に木を立てる（ホールの北山杉）・内と外の回廊・回廊と遊戯室に居場所

KAIT工房　石上純也・厚木・2008
→柱の配列：見る向きで景色が変わる並び

認定こども園らみどり　はりゅうウッドスタジオ・須賀川・2026
→内と外の二重の縁側、遊具を置かない地形の園庭

仙田満の園舎　環境デザイン研究所
→摺鉢のネット、キャットウォーク、ニッチ

Waldorf School of the Peninsula　California
→遊戯室の切り株

スターバックス京都二寧坂ヤサカ茶屋店　町家の改修・京都・2017
→放射冷房

面積表　m²（壁芯、3dmから自動）

室	要求	計画
乳児室（0〜1歳）	約60×2	120.5
保育室（2歳）	約60	60.0
保育室（3〜5歳）	約60×3	181.2
遊戯室	240以上	266.1
便所	適宜	17.2
食堂	必要に応じて	
園庭	350以上	982.2
事務室	約60	69.8
休憩室	約60	60.4
医務室	約30	30.1
調理室	約60	65.7
便所（大人用）	適宜	13.9
機械室	約30	30.0
倉庫	約30	36.2
駐車場	5台以上	○
駐輪スペース	適宜	○
延床（2,000以内）		**1,310.9**

建築設計実習Ⅱ－Ⅰ　2026.11.05　木田

［割付の注記］フォーカス：上に縦断A（弧の長さ）を一続きに。その下で二つの横断（1/100）が主役：断面Cに空気の環境（本館と西館の架構と風の道）、断面D（本館、光の筋で切る）に光の環境。右の列に季節ごとの空気環境・環境への配慮・inspired byと面積表　／　目に入る順：縦断A（上の帯）→ 断面C（空気）→ 季節ごとの空気環境・配慮 → 断面D（光）→ inspired by・面積表

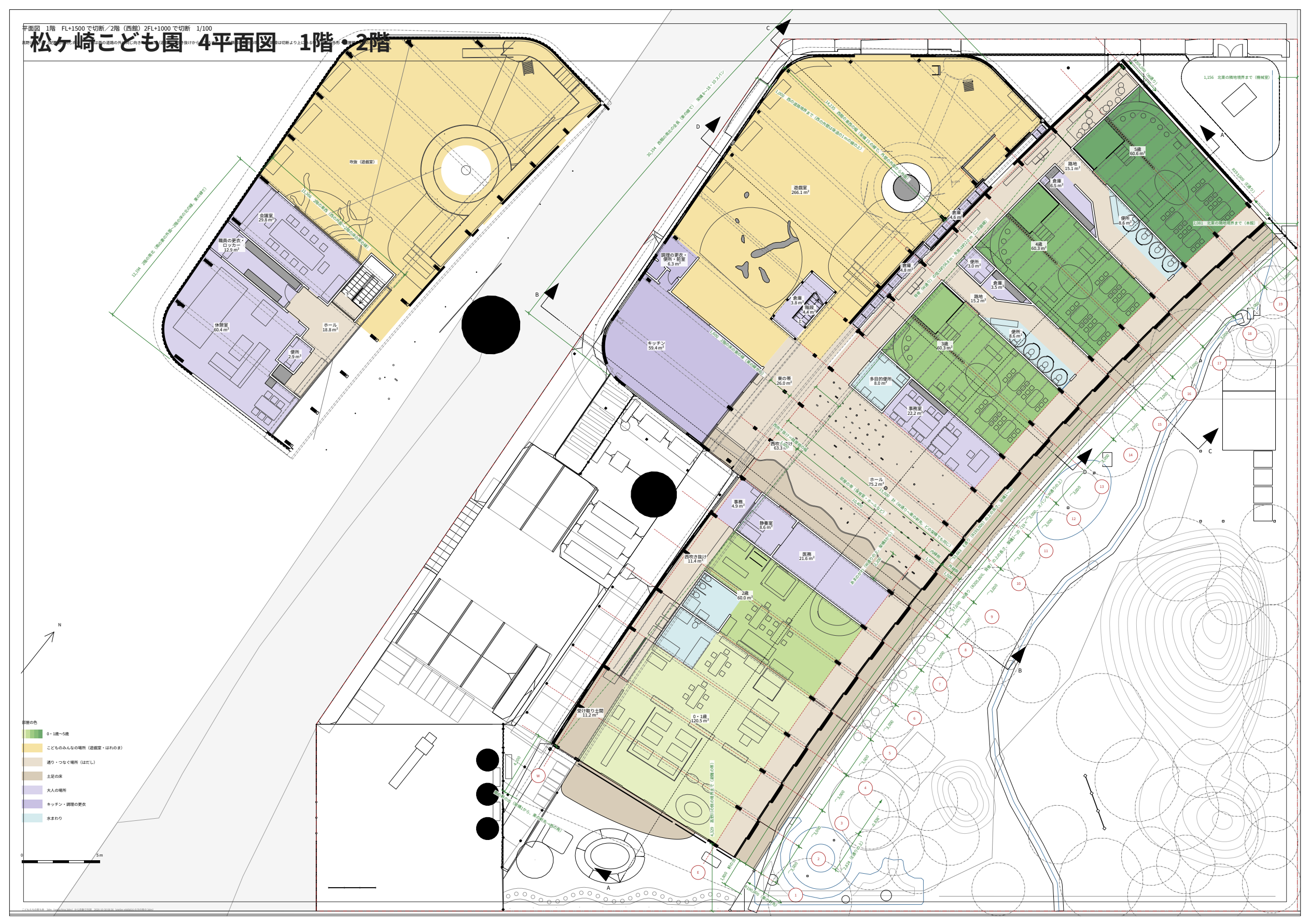

松ヶ崎こども園 4平面図　1階・2階

平面図　1階　FL+1500で切断／2階（西館）2FL+1000で切断　1/100

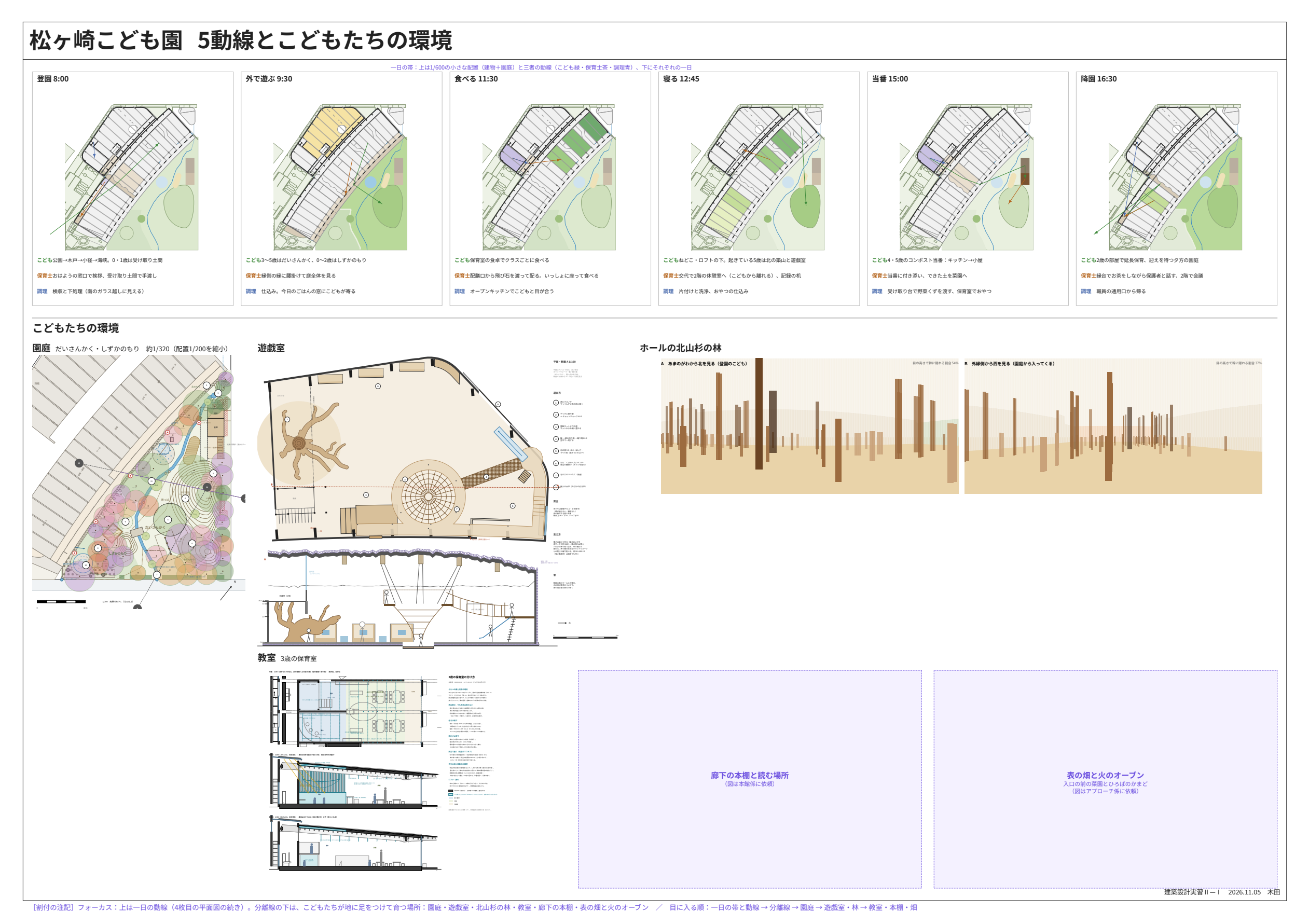

松ヶ崎こども園 5動線とこどもたちの環境

一日の帯：上は1/600の小さな配置（建物＋園庭）と三者の動線（こども緑・保育士茶・調理青）、下にそれぞれの一日

登園 8:00
こども　公園→木戸→小径→海峡。0・1歳は受け取り土間
保育士　おはようの窓口で挨拶、受け取り土間で手渡し
調理　検収と下処理（南のガラス越しに見える）

外で遊ぶ 9:30
こども　3〜5歳はだいさんかく、0〜2歳はしずかのもり
保育士　縁側の縁に腰掛けて庭全体を見る
調理　仕込み。今日のごはんの窓にこどもが寄る

食べる 11:30
こども　保育室の食卓でクラスごとに食べる
保育士　配膳口から飛び石を渡って配る。いっしょに座って食べる
調理　オープンキッチンでこどもと目が合う

寝る 12:45
こども　ねどこ・ロフトの下。起きている5歳は北の築山と遊戯室
保育士　交代で2階の休憩室へ（こどもから離れる）、記録の机
調理　片付けと洗浄、おやつの仕込み

当番 15:00
こども　4・5歳のコンポスト当番：キッチン→小屋
保育士　当番に付き添い、できた土を菜園へ
調理　受け取り台で野菜くずを渡す、保育室でおやつ

降園 16:30
こども　2歳の部屋で延長保育、迎えを待つ夕方の園庭
保育士　縁台でお茶をしながら保護者と話す、2階で会議
調理　職員の通用口から帰る

こどもたちの環境

園庭　だいさんかく・しずかのもり　約1/320（配置1/200を縮小）

遊戯室

ホールの北山杉の林

A　あまのがわから北を見る（登園のこども）

B　外縁側から西を見る（園庭から入ってくる）

教室　3歳の保育室

廊下の本棚と読む場所
（図は本館係に依頼）

表の畑と火のオーブン
入口の前の菜園とひろばのかまど
（図はアプローチ係に依頼）

建築設計実習Ⅱ－Ⅰ　2026.11.05　木田

［割付の注記］フォーカス：上は一日の動線（4枚目の平面図の続き）。分離線の下は、こどもたちが地に足をつけて育つ場所：園庭・遊戯室・北山杉の林・教室・廊下の本棚・表の畑と火のオーブン　／　目に入る順：一日の帯と動線 → 分離線 → 園庭 → 遊戯室・林 → 教室・本棚・畑

床