こどもたちの育ち舎　1/5　敷地と自然環境・地域

地に足をつけて育つ

比叡から降りる冷気と高野川の流れが出会う松ヶ崎の扇状地に、こどもたちが地に足をつけて育つ場所をつくる。ゆるやかな弧を東の比叡にひらく木造平屋の本館に0歳から5歳のすべての部屋を並べ、縁側と深い庇で園庭とつなぐ。比叡に見立てた築山と、用水を借りて高野川に見立てた小川を置く。

オープンキッチンを玄関ホールに面する園の中心に据え、食べることを日々の求心力とする。野菜くずをこどもたちの手で土に還し、命の循環を知る。園庭には季節ごとに香る木と実のなる木を植え、こどもたちは手と鼻と舌で季節を知る。

3 mスパンの木造架構によるスケルトン＆インフィルで用途の変化を受け止める。LEED v5 Gold相当を目指す。地域から様々なものを借り、無駄をせず巡らせて、こども園として地域に返す。

設計趣旨 約334字（課題は300字程度）。文字3.6 mmなら1 m離れて読める

地域4　災害時の持ちつ持たれつ

大洪水が予想される場合の緊急避難先として京都工芸繊維大学と協定（京都市ハザードマップによる浸水深1.5 m）。太陽光発電、蓄電池、地下水の利用によって、災害時に水を地域に提供。

地域3　お向かいさん

西の道の北半分は狭い道を挟んで向かいに住宅がある。圧迫感を与えないよう、この面の建物高さを1階程度に抑える。

自然6　間伐材を使った林

京都北山の北山杉の間伐材141本を、ホールの林として立てる。

地域2　車と自転車の出入りを南にまとめる

西の道の中ほどでは、道に突き出た木が見通しをさえぎる。車と送り迎えの自転車の出入りはこの木より南にまとめ、出入口にはスピードバンプを置いて速度を落とす。

地域1　小竹薮公園を残す

地域の記憶である小竹薮公園をそのまま残し、園への入口の前庭にする。そこから北へ、西の道沿いに幅1 mの歩道を開き、歩く人を車から守る。

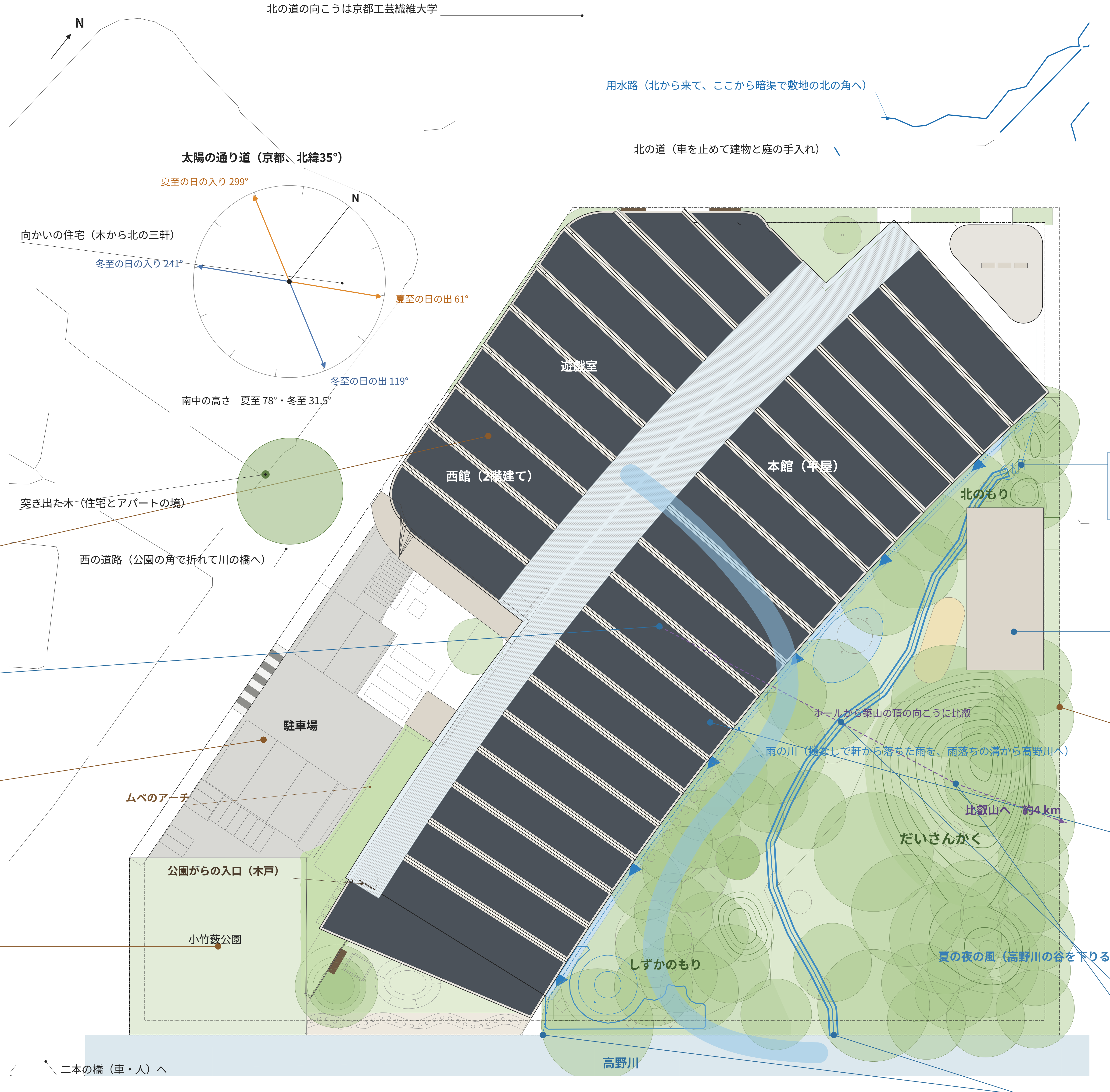
N
北の道の向こうは京都工芸繊維大学
用水路（北から来て、ここから暗渠で敷地の北の角へ）
北の道（車を止めて建物と庭の手入れ）
太陽の通り道（京都、北緯35°）
夏至の日の入り 299°
N
向かいの住宅（木から北の三軒）
冬至の日の入り 241°
夏至の日の出 61°
冬至の日の出 119°
南中の高さ　夏至 78°・冬至 31.5°
遊戯室
西館（2階建て）
本館（平屋）
北のもり
突き出た木（住宅とアパートの境）
西の道路（公園の角で折れて川の橋へ）
駐車場
ムベのアーチ
ホールから築山の頂の向こうに比叡
雨の川（樋なしで軒から落ちた雨を、雨落ちの溝から高野川へ）
比叡山へ　約4 km
だいさんかく
公園からの入口（木戸）
小竹薮公園
しずかのもり
夏の夜の風（高野川の谷を下りる風）
高野川
二本の橋（車・人）へ
0
20m

配置図　1/200　高野川を下に（川向こうから見る向き、北は右上）

自然1　用水を借りる

井出ヶ鼻井堰に端を発する松ヶ崎の用水ネットワークから、水を借り、園庭の小川にする。

自然2　野菜くずコンポスト

野菜くずや落ち葉をこどもたちの手で土に還す。発酵する暖かい土とミミズに驚く。野菜を育てる。命の循環を知る。

地域5　東の隣家への配慮

東の隣家との境は1 m下げ（セットバック）、園庭の小屋と植樹で視線と音をやわらげる。

自然5　風の道

夏の夜、高野川の谷を下りてくる涼しい風を、縁側の床下から越屋根へ抜く。床下に冷えをためて、昼の冷房を抑える。

自然3　高野川と比叡にみたてる

日本文化が育ててきた「みたて」。園内の小川と築山を高野川と比叡にみたてる。それを超えて視線を遠くにすると、高野川を超えて比叡の山。

自然4　水の行方を見る

小川は暗渠に隠さず高野川に注ぐ。屋根に降った雨は、雨落ちに落ち、雨水浸透側溝と雨庭を経て、溢れは高野川に。

松ヶ崎の用水ネットワーク

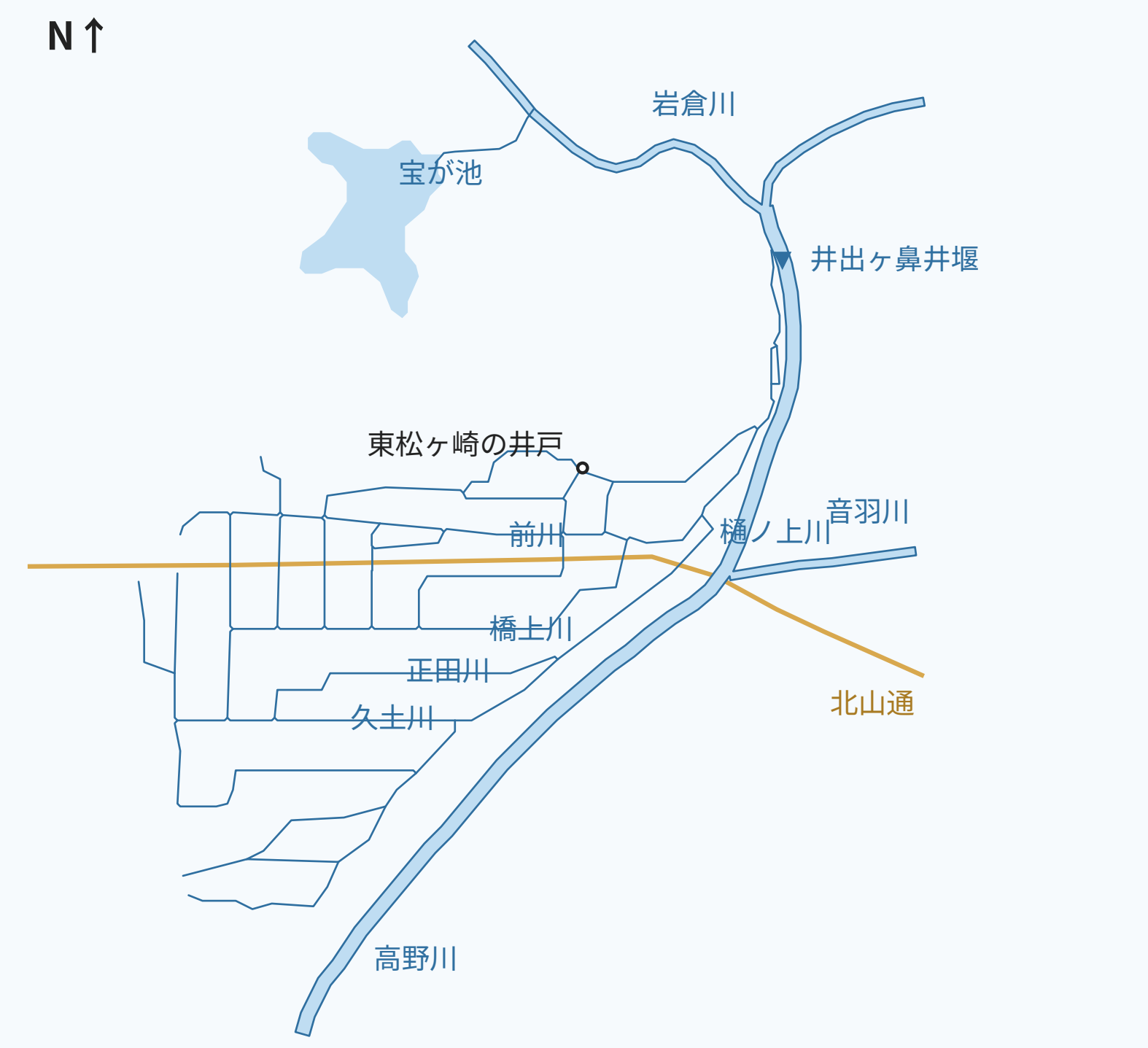
N↑
岩倉川
宝が池
井出ヶ鼻井堰
東松ヶ崎の井戸
前川
樋ノ上川
音羽川
橋上川
正田川
久土川
北山通
高野川

大正から昭和初期の図（https://kyoto-machisen.jp/chiiki_hp/matsugasaki_hp/history/history.htm）
図：http://ksdobokuisan.stars.ne.jp/80_takaragaike/takaragaike.html の図をなぞって描き直し

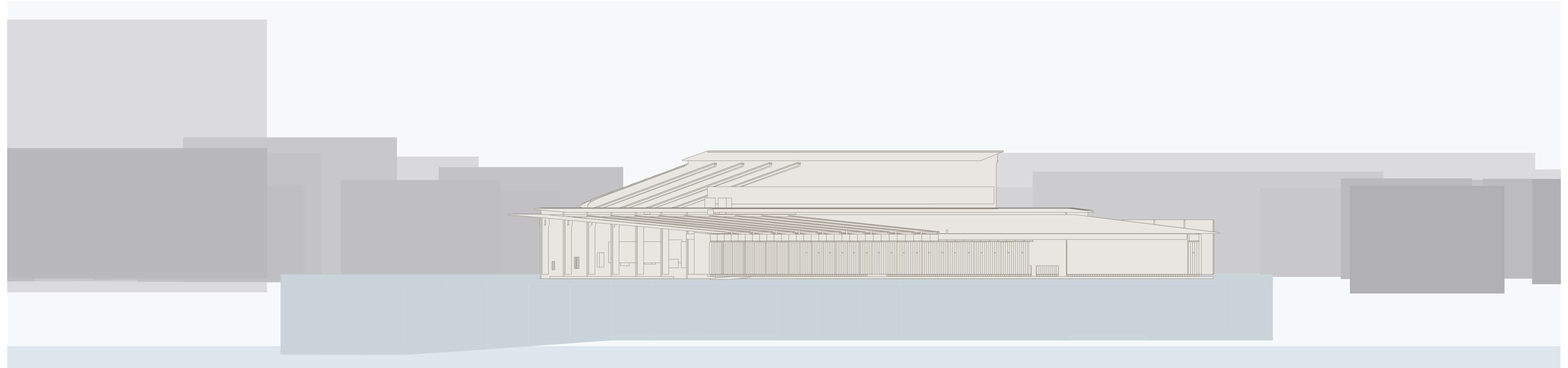

沿川の景観立面　昼　1/300　高野川の向こうから（川の辺に直角）、周りの建物とともに



沿川の景観立面　夜　越屋根の東の縁の光が水平に一本

［割付の注記］フォーカス：周囲の自然環境との関係と地域環境への配慮。配置図の上に夏の夜の風・比叡への視線・太陽の通り道、下に川の向こうから見た沿川の景観立面（昼・夜）　／　目に入る順：タイトルと趣旨 → 真ん中の配置図 → 左右の箱（青＝自然環境、茶＝地域）→ 用水のネットワーク → 下の景観立面

こどもたちの育ち舎　2/5　景観

園庭の側の立面図　1/100　円弧の中心の方向から弧の真ん中に正対

伸びやかな梁と縁側（梁の端・庇が3 mごとに並ぶ）。屋根は屋根材型の太陽光

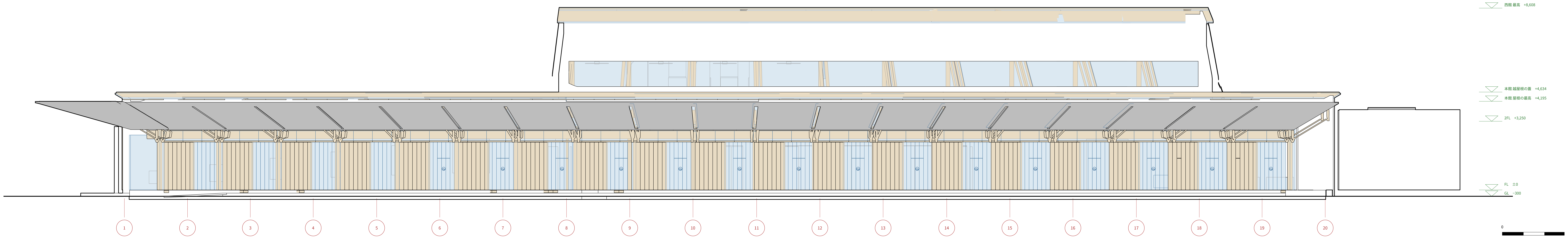
西館 最高　+8,608
本館 越屋根の蓋　+4,634
本館 屋根の最高　+4,195
2FL　+3,250
FL　±0
GL　−300
0
1
2
3
4
5
6
7
8
9
10
11
12
13
14
15
16
17
18
19
20

道路の側の立面図　1/100　西の道路から

西館の西端は1階の高さ（向かいの住宅）。西館の立ち上がりが北で主張する

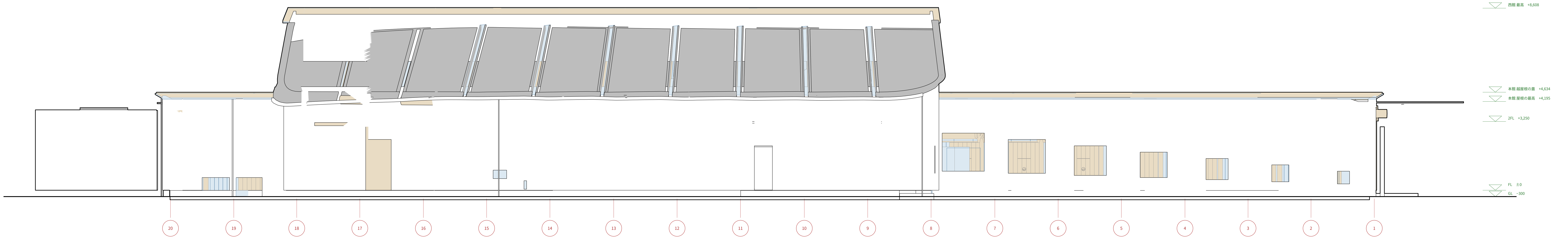
西館 最高　+8,608
本館 越屋根の蓋　+4,634
本館 屋根の最高　+4,195
2FL　+3,250
FL　±0
GL　−300
20
19
18
17
16
15
14
13
12
11
10
9
8
7
6
5
4
3
2
1

模型写真　鳥瞰

配置図と同じ向き（高野川を手前）
川側が低く北へ高くなる流れが見える角度で

景観の約束

第一種低層住居専用地域。西館の棟は約8.5 m（GLから）。

高野川特別修景地域（右岸）：河岸の樹木と清流が一体の水と緑の空間。川に面する側に植栽帯（園庭の林と生垣）、川に面する側に勾配のある下屋（南の深い軒）。深い軒と縁側、見せる北山杉の架構、スギ板、ゆるい勾配の屋根――これをいまの和風の外観とする。

遠景デザイン保全区域（高野川・修学院離宮・船岡山公園からの眺め）：外壁と屋根に禁止色を使わず、山並みと調和する色（黒い金属の屋根、木の色のまま）。

小竹薮公園と既存の木を残す。

素材と色

- ■ 北山杉の柱・梁（木の色のまま）
- ■ スギ板の外壁
- ■ 屋根：黒い金属（屋根材型の太陽光）
- ■ 越屋根のガラスの蓋・縁側の白
- ■ 生垣と園庭の緑

［割付の注記］フォーカス：建物に正対する二つの立面（園庭の側・道路の側）で、伸びやかな梁と縁側、西館の立ち上がり。沿川の景観立面（昼・夜）は1枚目の下　／　目に入る順：園庭の側・道路の側の立面図 → 鳥瞰・景観の約束・素材と色

こどもたちの育ち舎　3/5　平面図　1階・2階

平面図　1階　FL+1200 で切断／2階（西館）2FL+1200 で切断　1/100

高野川を下に（配置図と同じ向き）。2階は西の道路の外に同じ向きで置いた（遊戯室は吹き抜けから見下ろす）。一点鎖線は敷地の境

吹抜（遊戯室）
遊戯室
245.9 m²
会議室
29.8 m²
職員の更衣・ロッカー
12.9 m²
休憩室
60.4 m²
ホール
17.1 m²
便所
2.9 m²
下
吹抜
遊戯室
245.9 m²
調理の更衣・便所・前室
6.3 m²
食べる土間
22.0 m²
倉庫
2.9 m²
階段
3.4 m²
上
キッチン
59.4 m²
東の帯
24.3 m²
西吹き抜け
64.0 m²
ホール
75.3 m²
倉庫
4.6 m²
倉庫
6.9 m²
通り抜け
15.2 m²
倉庫
6.5 m²
5歳
60.7 m²
便所
8.6 m²
4歳
60.4 m²
便所
3.0 m²
倉庫
3.6 m²
通り抜け
15.2 m²
3歳
60.4 m²
便所
8.6 m²
多目的便所
8.0 m²
事務
9.7 m²
園長室・応接
12.6 m²
事務
4.9 m²
静養室
8.6 m²
医務
21.6 m²
西吹き抜け
11.4 m²
2歳
60.0 m²
受け取り土間
11.2 m²
0・1歳
120.5 m²
N
A
B
C
W
E
1
2
3
4
5
6
7
8
9
10
11
12
13
14
15
16
17
18
19
3,000
19 × 3,000 = 57,000（背骨 r=205 m で）
0
5 m

部屋の色

- 🟩 0・1歳〜5歳
- 🟨 こどものみんなの場所（遊戯室・はれのま）
- ▨ 通り・つなぐ場所（はだし）
- ▨ 土足の床
- ▨ 大人の場所
- ▨ キッチン・調理の更衣
- ▨ 水まわり

こどもたちの育ち舎　4/5　こどもたちと働く人たちの環境

一日の帯：上は1/600の小さな配置（建物＋園庭）と三者の動線（こども緑・保育士茶・調理青）、下にそれぞれの一日

登園 8:00

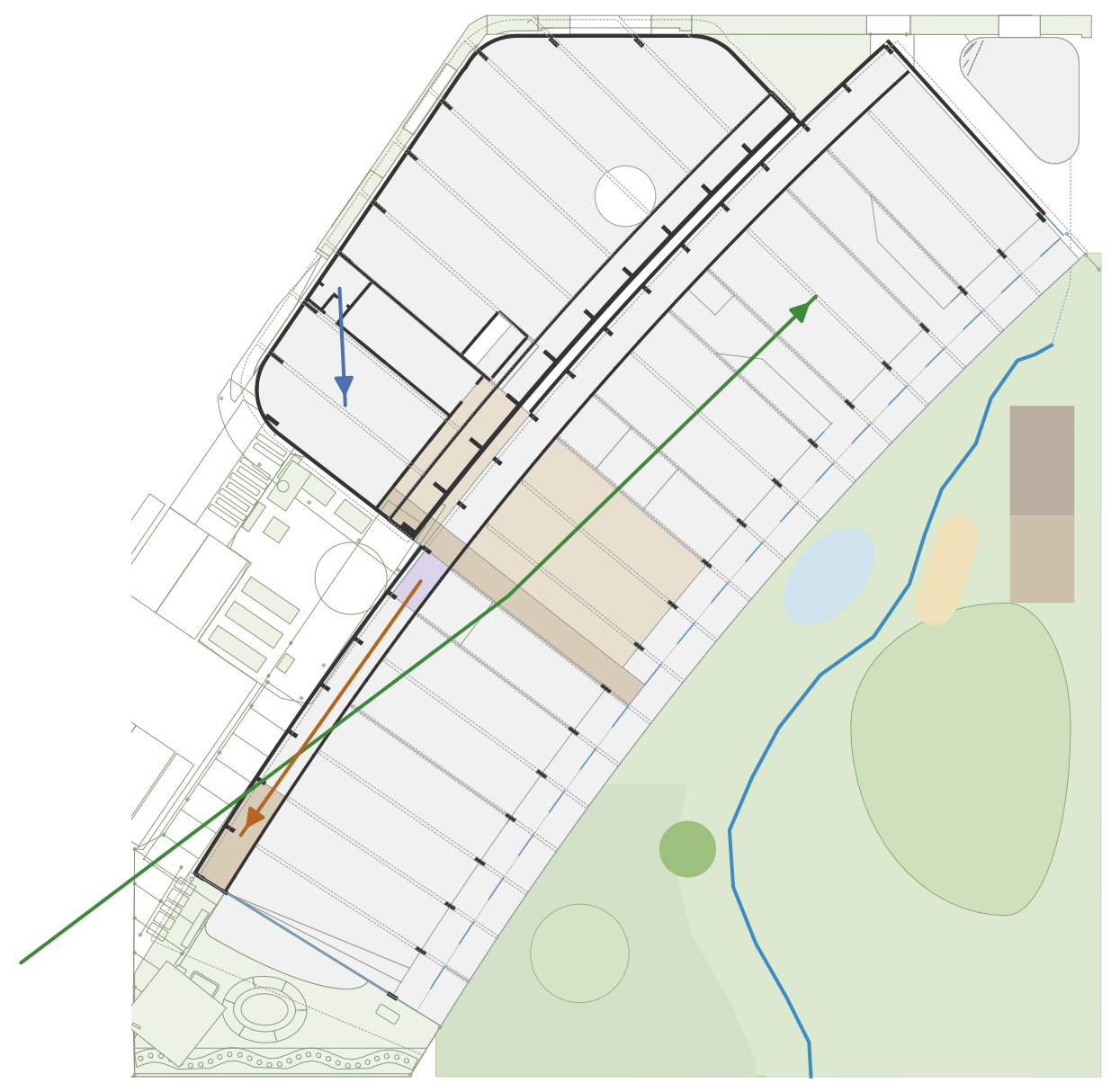

こども公園→木戸→小径→海峡。0・1歳は受け取り土間

保育士おはようの窓口で挨拶、受け取り土間で手渡し

調理　検収と下処理（南のガラス越しに見える）

外で遊ぶ 9:30

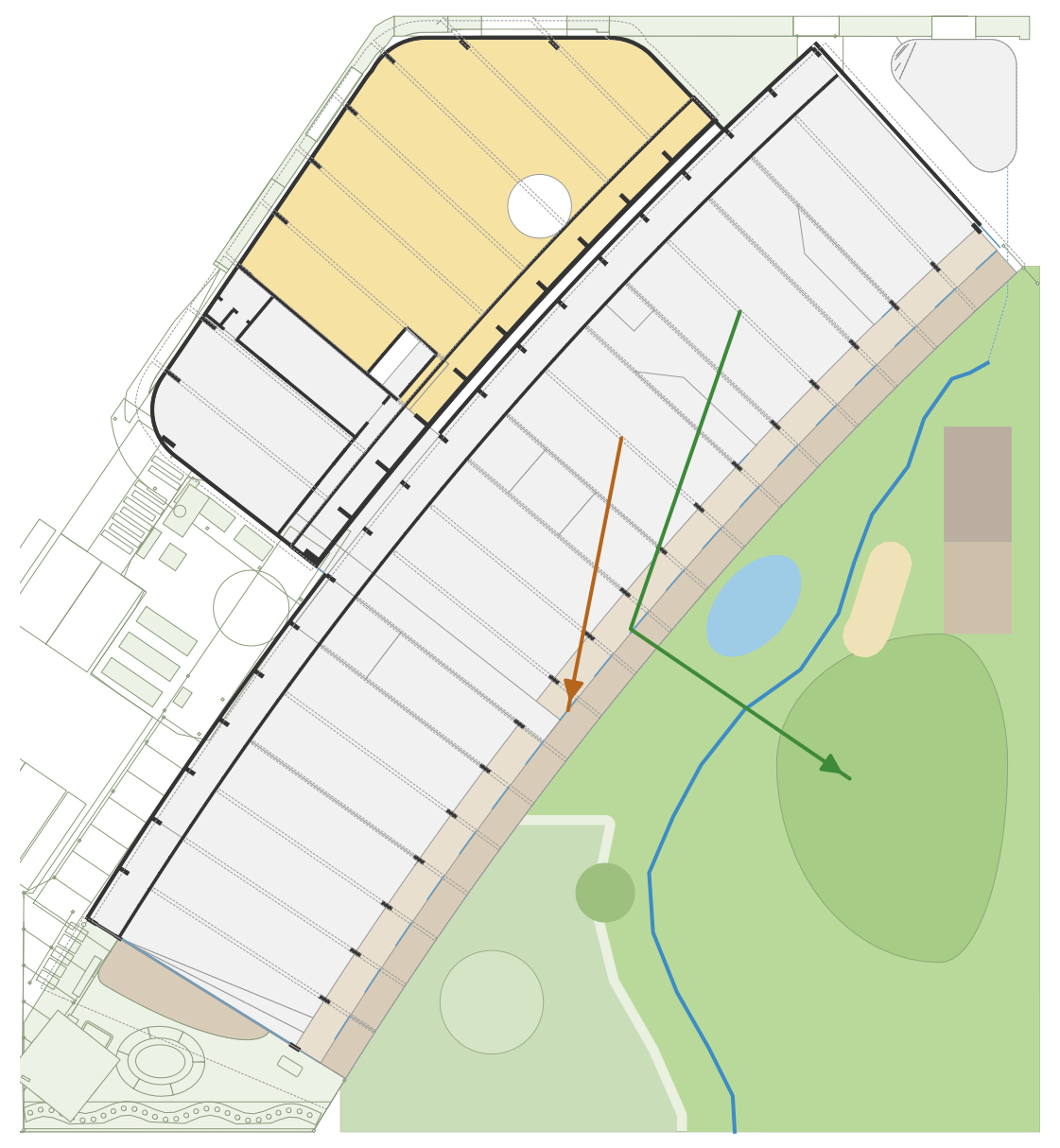

こども3〜5歳はだいさんかく、0〜2歳はしずかのもり

保育士縁側の縁に腰掛けて庭全体を見る

調理　仕込み。今日のごはんの窓にこどもが寄る

食べる 11:30

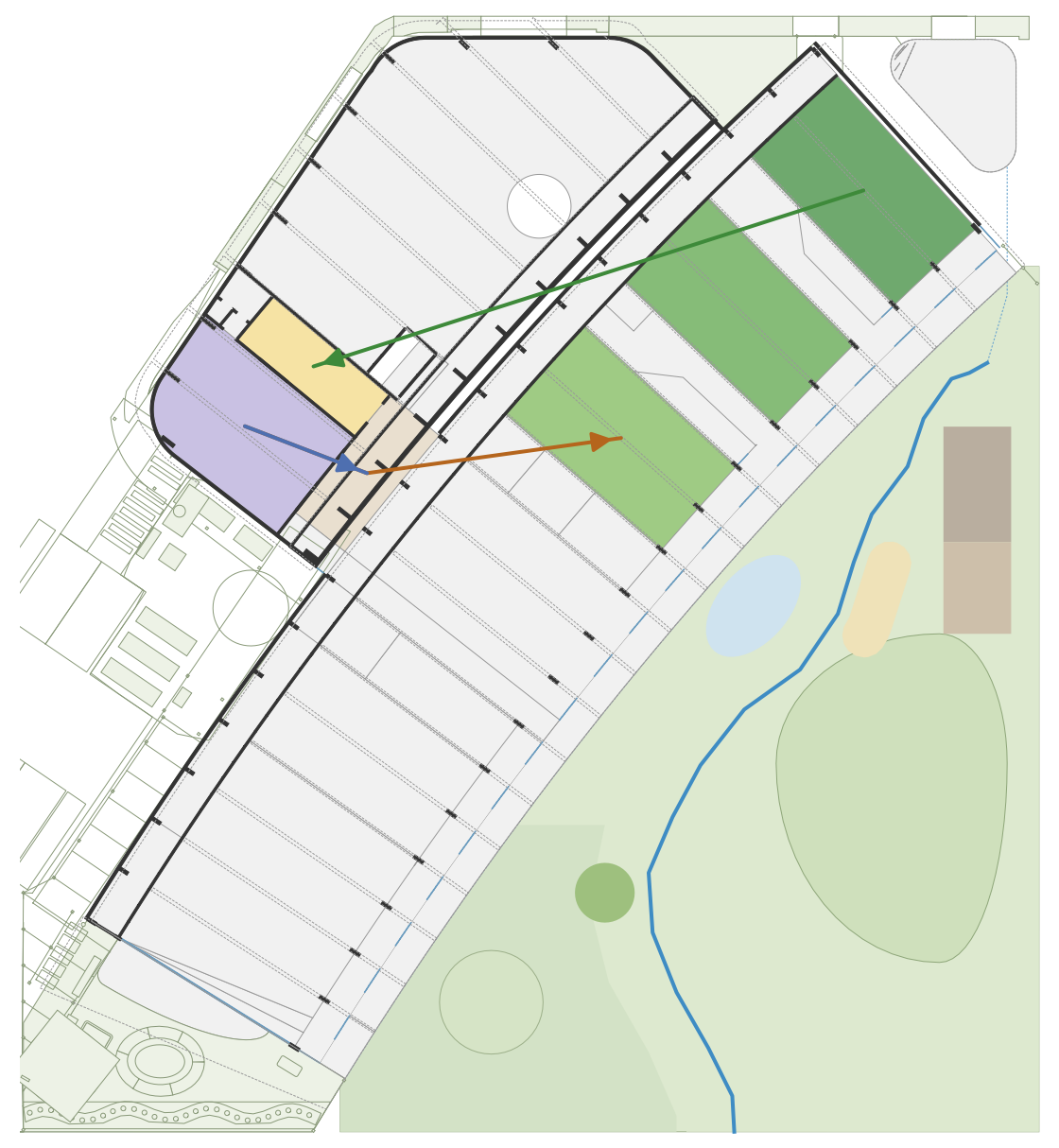

こども保育室の食卓、はれのまでクラスごと

保育士配膳口から飛び石を渡って配る。いっしょに座って食べる

調理　オープンキッチンでこどもと目が合う

寝る 12:45

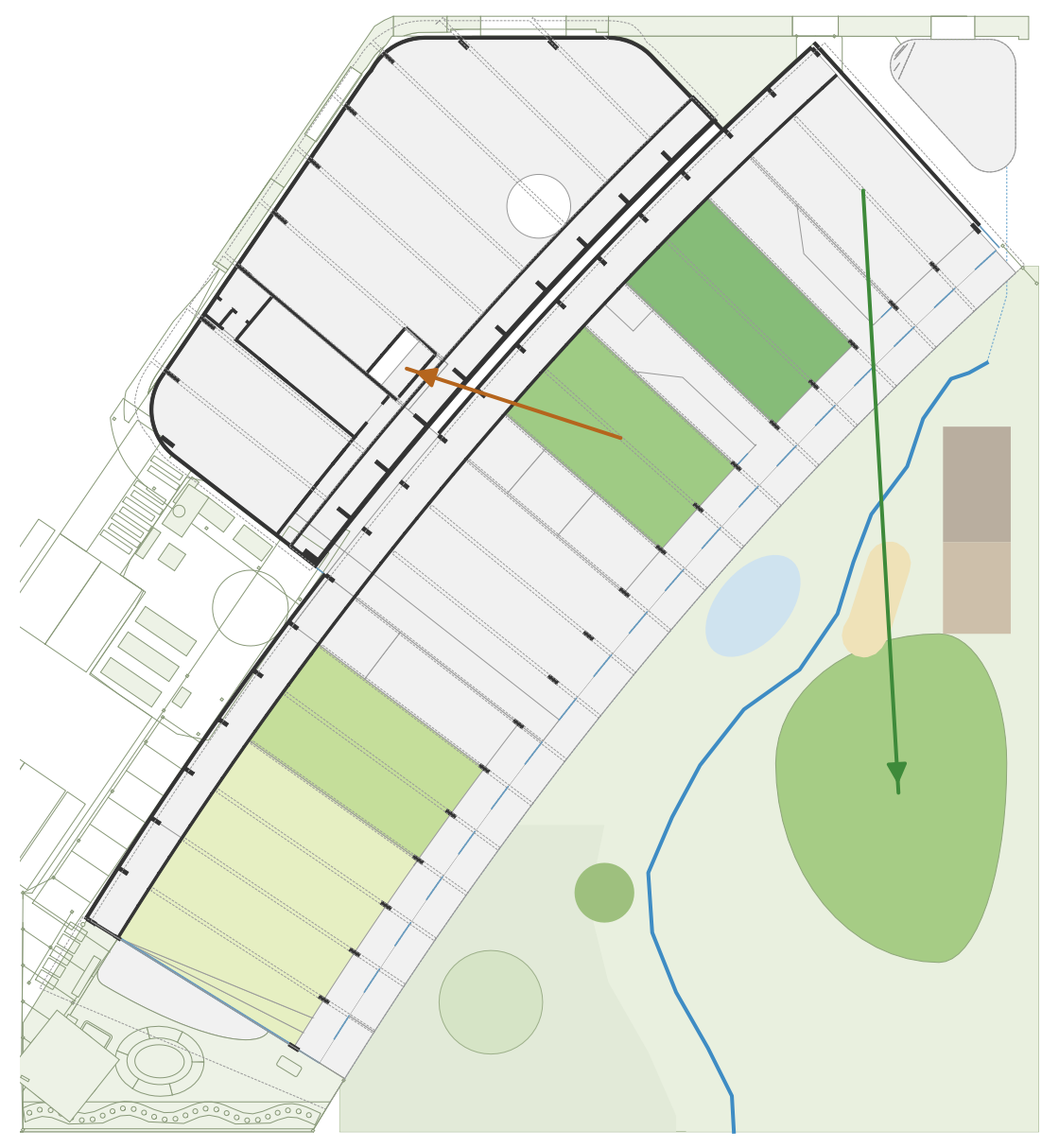

こどもねどこ・ロフトの下。起きている5歳は北の築山と遊戯室

保育士交代で2階の休憩室へ（こどもから離れる）、記録の机

調理　片付けと洗浄、おやつの仕込み

当番 15:00

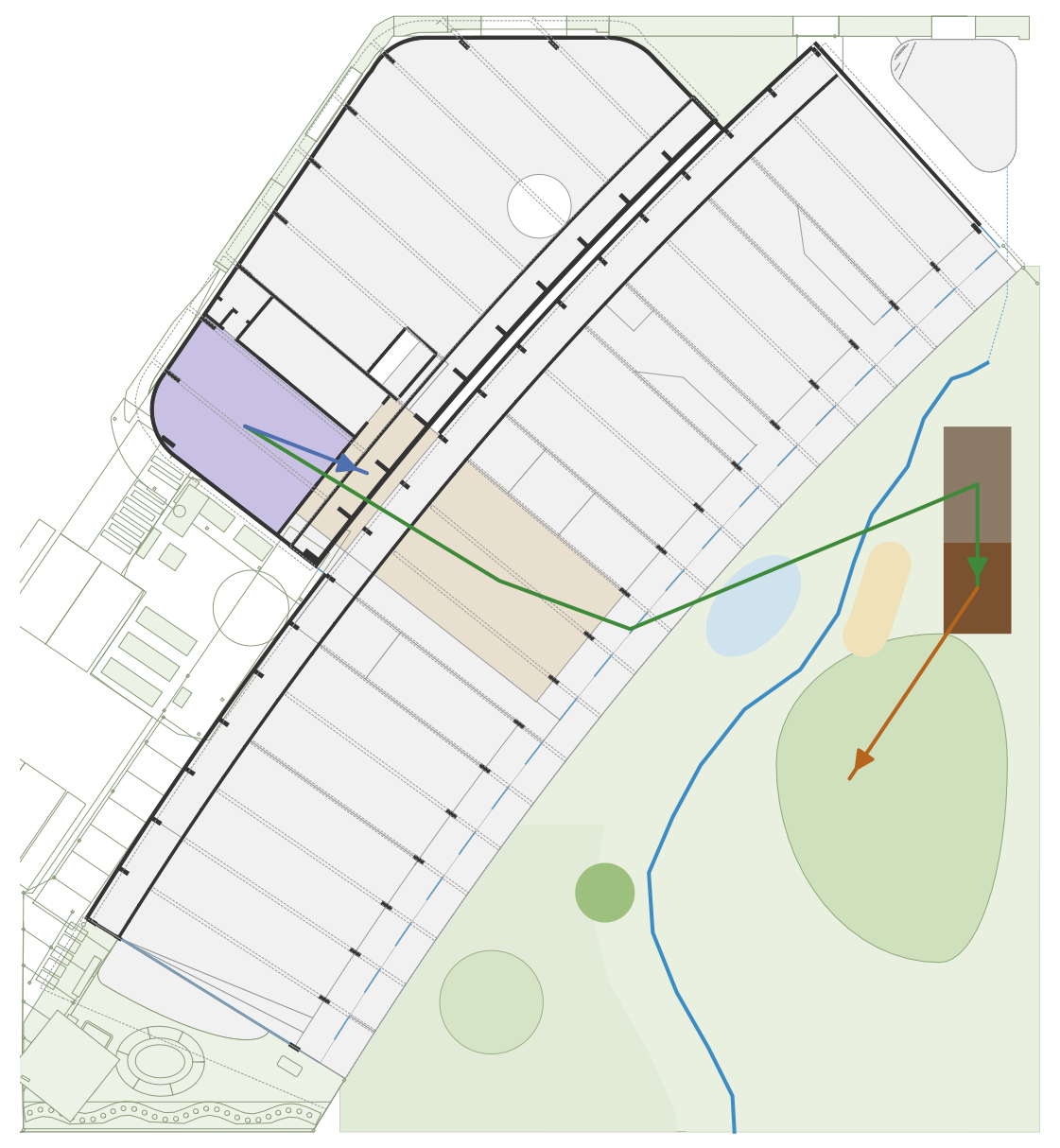

こども4・5歳のコンポスト当番：キッチン→小屋

保育士当番に付き添い、できた土を菜園へ

調理　受け取り台で野菜くずを渡す、はれのまでおやつ

降園 16:30

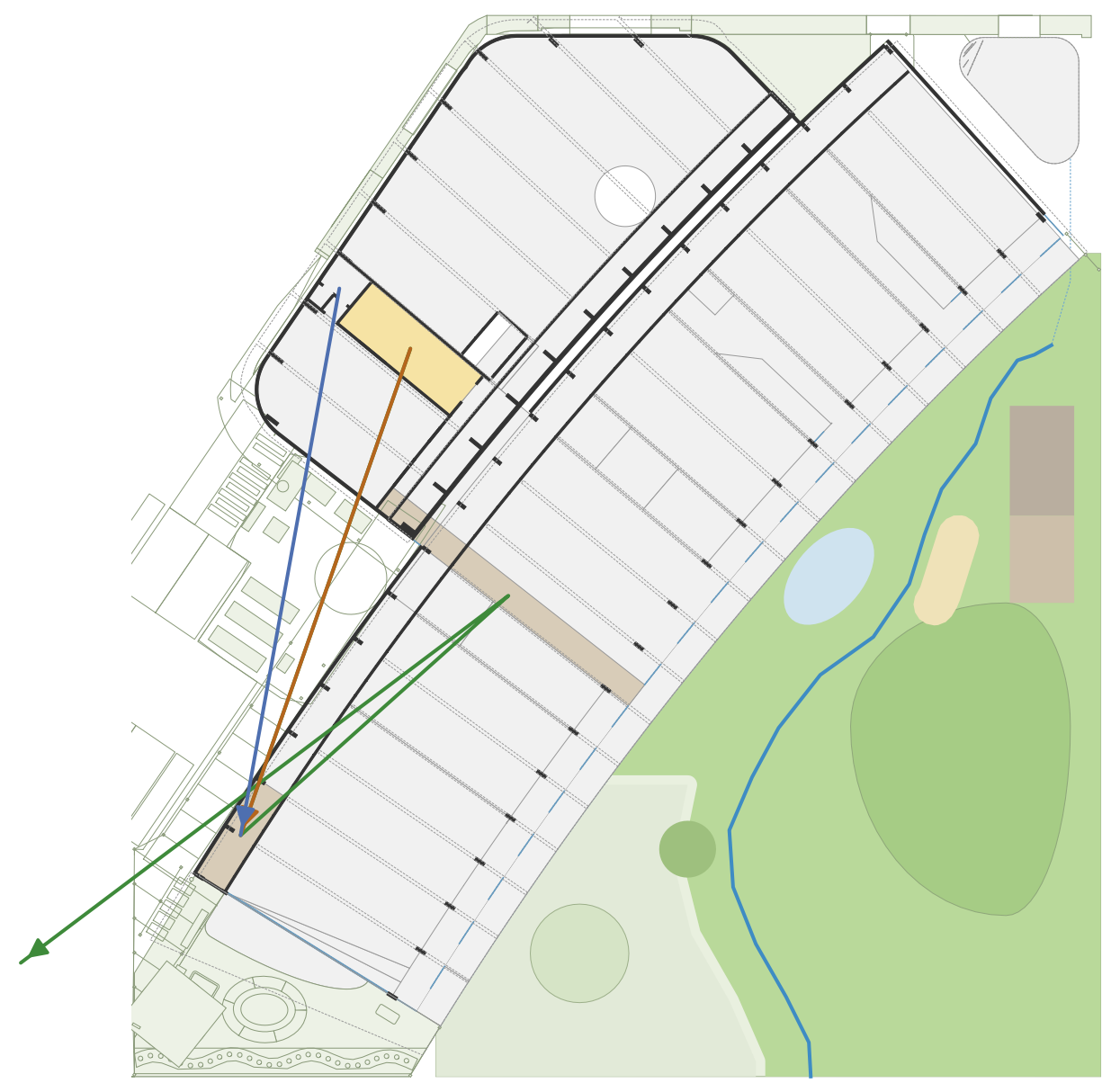

こどもはれのまで延長保育、迎えを待つ夕方の園庭

保育士縁台でお茶をしながら保護者と話す、2階で会議

調理　職員の通用口から帰る

透視図（A4）　模型写真か彩色の透視図

こどもの目の高さで、園庭から縁側とホールの北山杉の林を見る

梁の見える天井・光の筋・オープンキッチン

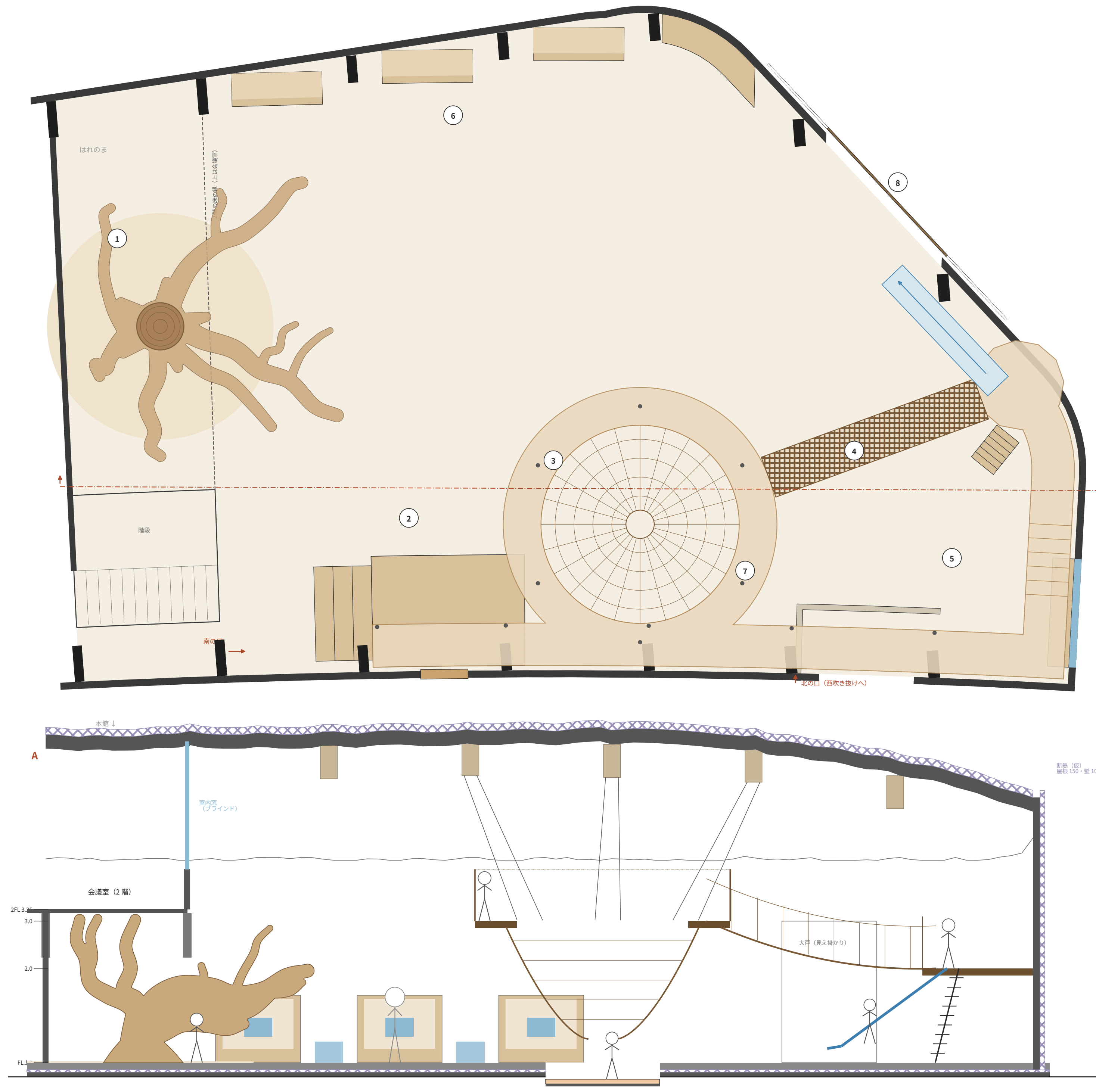

平面・断面 A 1/100

平面は FL+1.2 で切る。淡い茶は
キャットウォーク・輪・踊り場
（h3.0／2.0）、黒い点は吊り材。
断面 A は東から 4.3 で切って西を見る

遊び方

① 洞とクスノキ
てっぺんが 2 階の床に届く

② デッキと登り壁
→ キャットウォーク h3.0

③ 擂鉢ネットと穴の底
ネットからも輪へ登れる

④ 輪 → 網の吊り橋 → 踊り場 h2.0
空中で一周する

⑤ 北の段 3.0→2.0・はしご・
すべり台（落下 2.0 m 以下）

⑥ ひだ：くぼみ・丸いベンチ・
窓辺の腰掛け（モミジを見る）

⑦ 北の口のついたて（吸音）

⑧ 搬入の大戸（外付けの引き戸）

安全

手すりは縦格子 h1.1・すき間 90
（頭が通らない、横桟なし）
床の板のすき間 8 未満
網目 上 90・下 50、ロープ φ18

支え方

重さは梁から吊る（梁のあいだを
通す）。横の揺れは壁とハの字の
吊り材で止め、吊り橋だけ揺れる。
梁 90×700×2 は満員でも持つ
（略算：曲げ 8.0／11.0 N/mm²）

断熱（仮）
屋根 150・壁 100・床 50

音

階段の箱がホールとの衝立。
北の口に吸音のついたて、
東の覗き窓は夜だけ開く

見立て

築山は比叡、小川は高野川。足もとを掘った土で盛る。

水の行方を隠さない

用水→みなもと→小川→護岸の溝→高野川。雨は樋なしで。

土と命のめぐり

野菜くずはこどもの手でコンポストへ、土に還す。ミミズに驚く。

季節を手と鼻と舌で

季節ごとに香る木と実のなる木。とげの木は一本だけ、わざと。

静かな場所と先生の目

関守石で「ここからはしずかに」。取り除くのは命に関わる危険だけ。

園庭　約1/440（配置1/200を縮小）

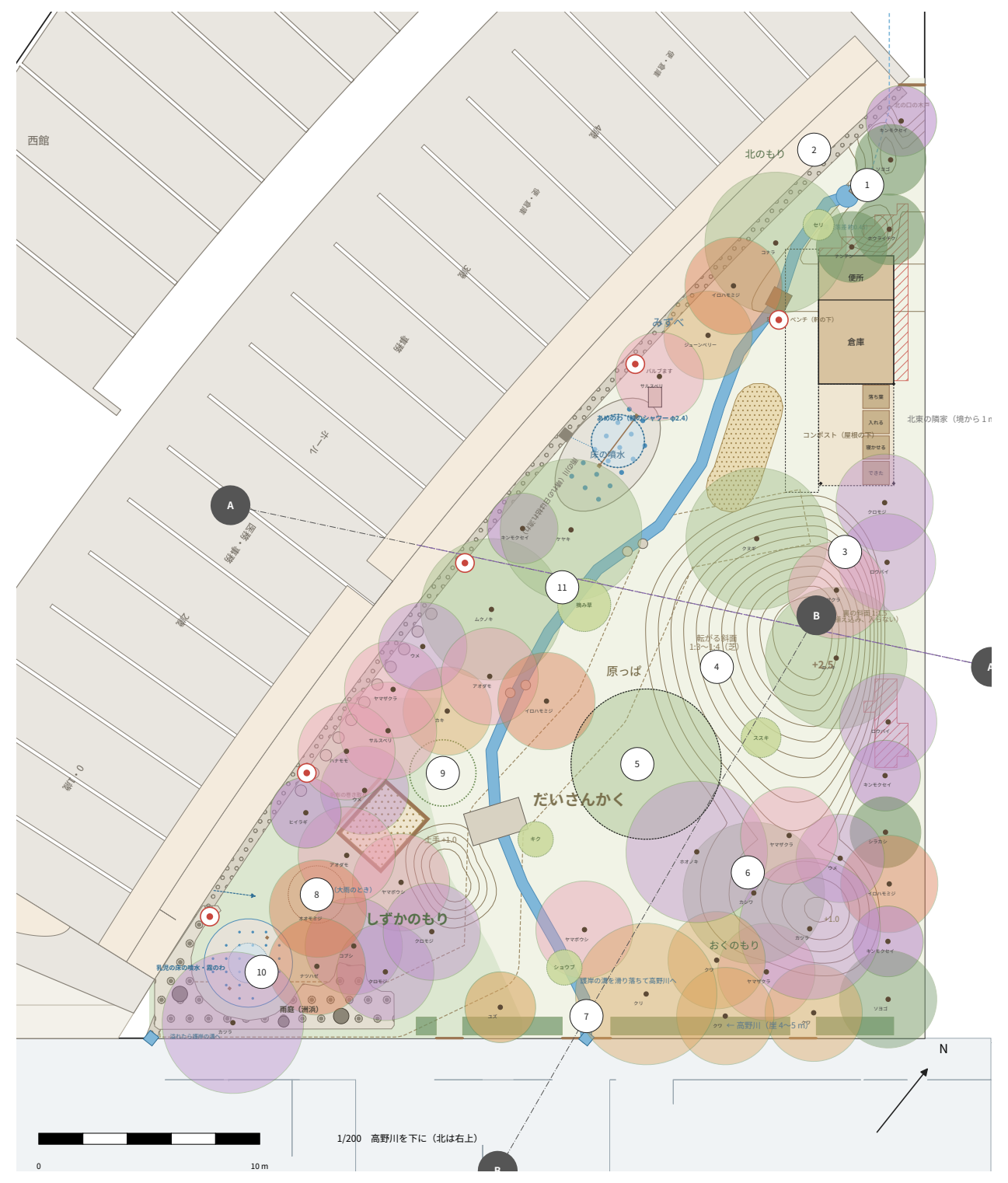

ホールの北山杉の林　こどもの目の高さから

ホールの北山杉の林　こどもの目の高さ（0.9 m）から見た景色　（たたき台・6 版：すべて自立）

円筒投影（横＝方位 110°、縦＝仰角）。幹は北山杉（φ50 は磨き丸太、群の φ70・100 は太鼓落とし＝両側を平らに挽いた丸太、平らな面を列の向きにそろえる）。奥の色：うす緑＝縁側のガラス越しの園庭、ベージュ＝壁、橙＝キッチンのガラス、灰＝海峡。低い木（0.85〜1.1）はこどもの目の高さを隠し、高い木は屋根の近くまで



A　海峡から北を見る（登園のこども）　目の高さで幹に隠れる割合 54%

B　外縁側から西を見る（園庭から入ってくる）　目の高さで幹に隠れる割合 37%

洞のクスノキ　遊戯室の切り株

断面パース　スパン 11 の北の端（u 32.9）で切って南を見る



洞のクスノキ

2 階の床の下の低い洞（梁の下 2.23）。クスノキの枝の先が天井に触れ、木が 2 階を支えているように見える。
北の枝は床の縁の下をくぐって遊戯室の高い側へ（この図では切断面で切れている）。

園庭の断面　A 比叡へ／B 高野川へ（縮小）

断面 A–A　ホールから築山の頂を通って比叡山の向きへ　1/100

コンポスト：小屋の倉庫の南東、屋根の下の壁のない間に木枠 4 つ（落ち葉・入れる・寝かせる・できた、全体 約 4.6×1.2）。4・5 歳の当番がキッチンから野菜くずをもらい、落ち葉と重ね、できた土を入口の前の菜園へ運ぶ（ユーザー）

土の使い道（ユーザー：無理なく使える分だけ）：表土 約 160 m³ は全部敷地に残す（築山の表面 0.2・木の下の林床 0.2 約 581 m²・菜園）。下の土は築山の芯・土手・林床の盛り・西館の床の下へ。外へ出すのは下の土 約 504 m³（近くの工事へ）

死角：約 33 m²。築山の裏（隣家側）の植え込みと、北のもりの奥。植え込みは入らない所にする

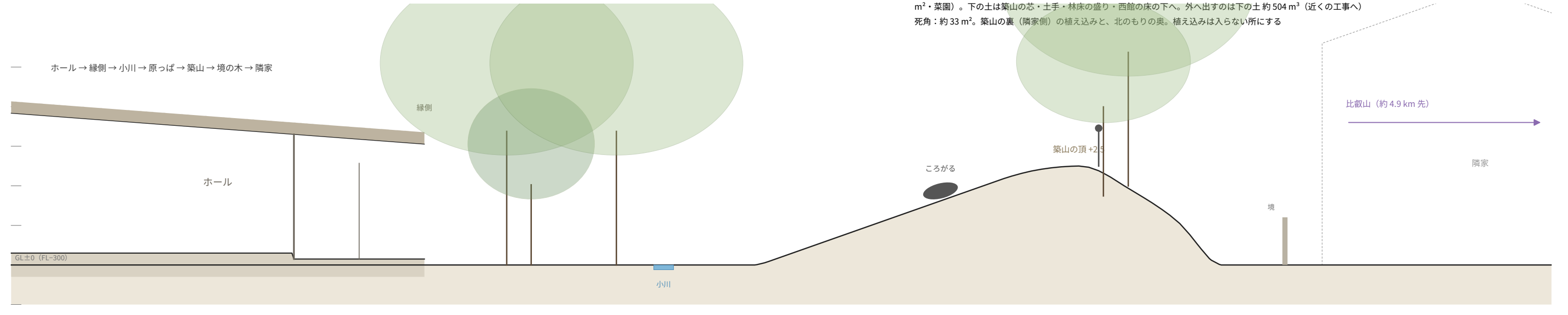

断面 B–B　築山から原っぱ・のぞき（生垣の口）を通って高野川へ　1/100（崖・河川敷の寸法は仮）

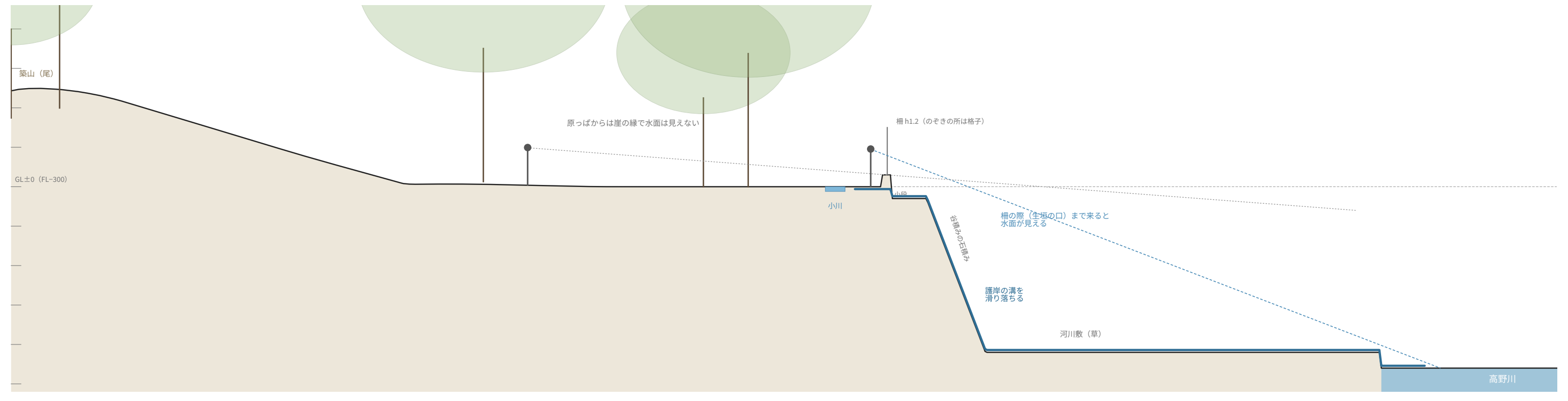

建築設計実習 II — I　2026.11.05　木田

［割付の注記］フォーカス：すべての人の一日（こども・保育士・調理）と、こどもたちが地に足をつけて育つ場所：透視図・遊戯室・園庭・北山杉の林　／　目に入る順：一日の帯と動線 → 透視図（A4）→ 遊戯室 → 園庭の5つ → 園庭・林・洞・断面

こどもたちの育ち舎　5/5　環境

断面図C　東西に切る（4歳・遊戯室の摺鉢ネット）

1/75（1/100の自動の図を1.5倍）　西の道路から園庭へ

矢印：昼の道（青）と夏の夜の道（紺）。床下の底板t200と断熱の帯。光の筋の光

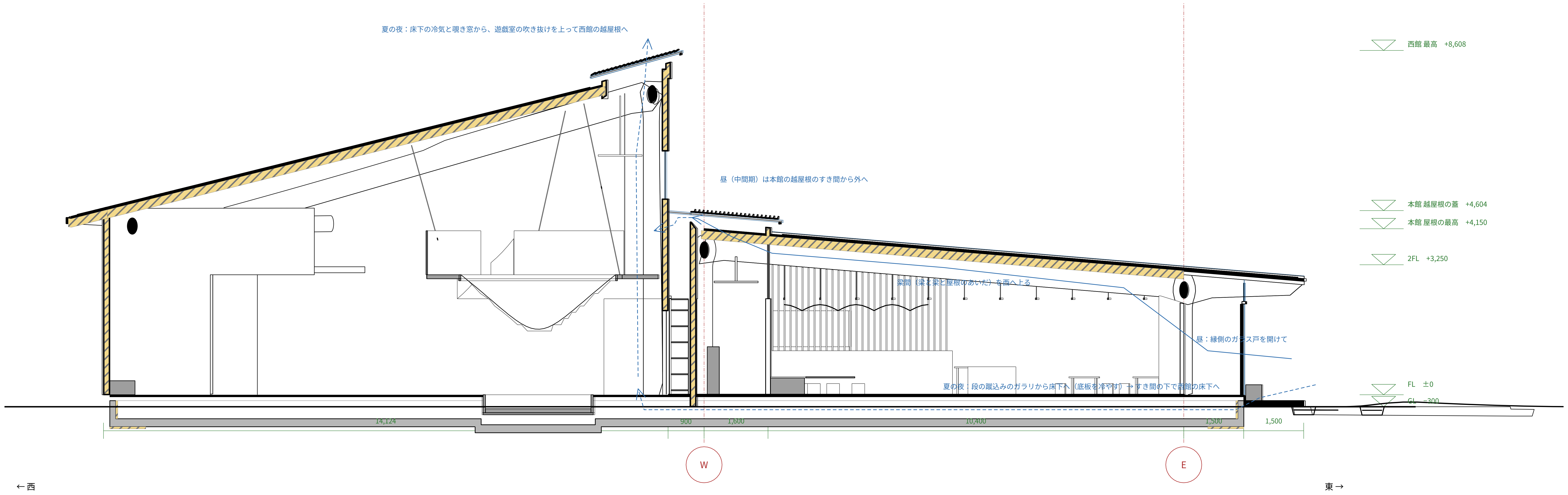
夏の夜：床下の冷気と覗き窓から、遊戯室の吹き抜けを上って西館の越屋根へ
昼（中間期）は本館の越屋根のすき間から外へ
梁間（梁と梁と屋根のあいだ）を西へ上る
昼：縁側のガラス戸を開けて
夏の夜：段の蹴込みのガラリから床下へ（底板を冷やす）→すき間の下で西館の床下へ
西館 最高　+8,608
本館 越屋根の蓋　+4,604
本館 屋根の最高　+4,150
2FL　+3,250
FL　±0
GL　−300
14,124
900
1,600
10,400
1,500
1,500
W
E
←西
東→

運転表

夏の昼
庇・天井扇
床下空調

夏の夜
床下→梁間
→越屋根・遊戯室

春・秋
越屋根を開ける
縁側を開け放す

冬
換気口を閉じる
熱交換・断熱

環境への配慮（LEED v5 Gold相当）

パッシブ
床下に冷えをためる
通風・光の筋

エネルギー
屋根材型の太陽光
蓄電池

資源
北山杉の間伐材
土・雨・生ごみを回す

時間
S&I
水まわりはどこでも

縦断面図A

1/100　保育室の中ほどの弧で切って展開、西を見る（左が南の高野川）

1
2
3
4
5
6
7
8
9
10
11
12
13
14
15
16
17
18
19
20
高野川の護岸（現況、寸法は仮）
←南（高野川）
北→
本館 屋根の
2FL　+3,25
FL　±0
GL　−300

断面図B　海峡

1/100　南の入口・キッチン・2階・すき間・本館・縁側

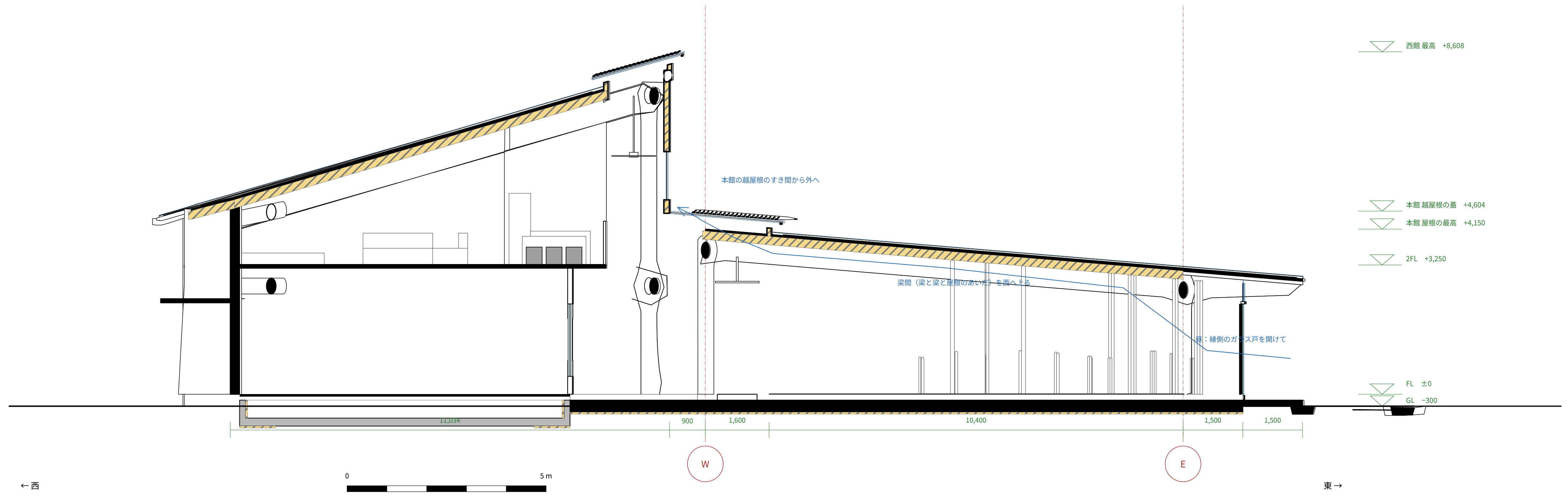
本館の越屋根のすき間から外へ
梁間（梁と梁と屋根のあいだ）を西へ上る
昼：縁側のガラス戸を開けて
西館 最高　+8,608
本館 越屋根の蓋　+4,604
本館 屋根の最高　+4,150
2FL　+3,250
FL　±0
GL　−300
11,034
900
1,600
10,400
1,500
1,500
W
E
0
5 m
←西
東→

スケルトン＆インフィル
3 mスパンの架構（固定）と
間仕切り・家具（可変）
今／定員が変わる／地域の場

光の筋と架構　1/20
2枚の梁のあいだ180の上に
乳白ガラス

inspired by

Asilo Nido Iride
Mario Cucinella Architects・Guastalla・2015
→梁の列が並ぶ長細い本館と、外に付く付属の建物

Tamedia
坂茂・Zürich・2013
→梁の端の楕円の頭と、それを貫く楕円の桁

レイモンド斑鳩こども園
キノアーキテクツ・斑鳩・2026
→室内に木を立てる（ホールの北山杉）

KAIT工房
石上純也・厚木・2008
→柱の配列：見る向きで景色が変わる並び

認定こども園らみどり
はりゅうウッドスタジオ・須賀川・2026
→内と外の二重の縁側、遊具を置かない地形の園庭

仙田満の園舎
環境デザイン研究所
→摺鉢のネット、キャットウォーク、ニッチ

Waldorf School of the Peninsula
California
→遊戯室の切り株

接合部（2枚の梁で柱を挟む）

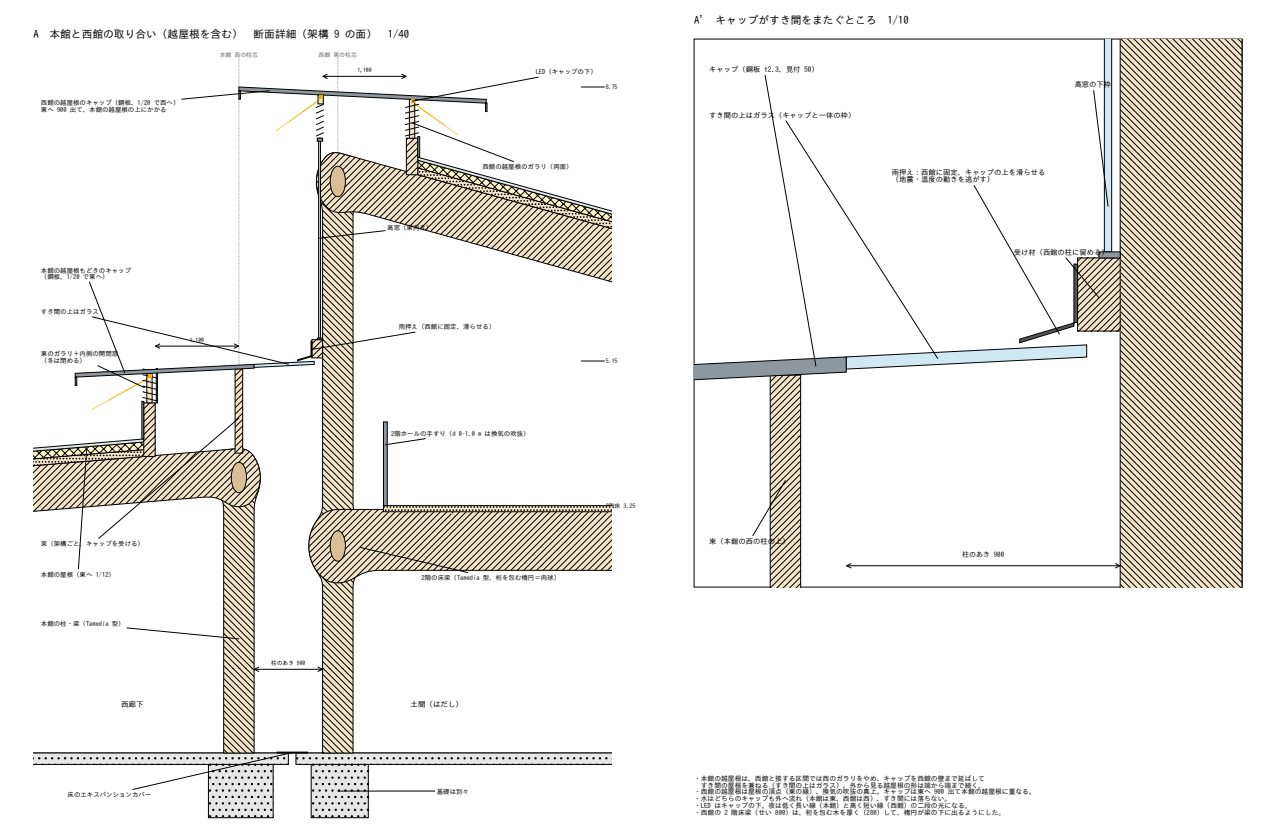
A　本館と西館の取り合い（越屋根を含む）　断面詳細（架構 9 の面）　1/40
A'　キャップがすき間をまたぐところ　1/10
LED（キャップの下）
西館の越屋根のガラリ（両面）
雨押え（西館に固定、滑らせる）
本館の柱・梁（Tamedia 型）
柱のあき 900
西廊下
土間（はだし）
床のエキスパンションカバー
基礎は別々
キャップ（鋼板 t2.3、見付 50）
すき間の上はガラス（キャップと一体の枠）
受け材（西館の柱に留める）
束（本館の西の柱の上）

建築設計実習 II — I　2026.11.05　木田

［割付の注記］フォーカス：木造・パッシブ（床下・越屋根・光の筋）で空調を補う。東西に切った断面Cで空気の流れ。屋根材型の太陽光と蓄電池、資源のめぐり、時間（S&I）　／　目に入る順：断面C（昼と夏の夜の風）→運転表と配慮→縦断A→断面B→木の組み方・S&I