# 地に足をつけて育つ

比叡から降りる冷気と高野川の流れが出会う松ヶ崎の扇状地に、こどもたちが地に足をつけて育つ場所をつくる。ゆるやかな弧を東の比叡にひらく木造平屋の本館に0歳から5歳のすべての部屋を並べ、縁側と深い庇で園庭とつなぐ。比叡に見立てた築山と、用水を借りて高野川に見立てた小川を置く。

オープンキッチンを玄関ホールに面する園の中心に据え、食べることを日々の求心力とする。野菜くずをこどもの手で土に還し、命の循環を知る。園庭には季節ごとに香る木と実のなる木を植え、こどもたちは手と鼻と舌で季節を知る。

３ｍスパンの木造架構によるスケルトン＆インフィルで用途の変化を受け止める。LEED v5 Gold相当を目指す。地域から様々なものを借り、無駄をせず巡らせて、こども園として地域に返す。

設計趣旨 約332字（課題は300字程度）。文字3.6 mmなら1 m離れて読める

## 自然環境と地域

### 借りぐらし　水と木を借りる




1/2000　松ヶ崎の用水から水を、北山から木を借りる
地下水の豊かな土地（物語）
（用水路と川は敷地図の線をなぞった、精度は数m）

### 山から川へ

小さな図＋
北のもりのみなもとから縁側の前・原っぱ
を流れ、護岸の溝を滑り落ちて高野川へ
築山＝比叡、小川＝高野川のうつし

### 河川敷とつなぐ

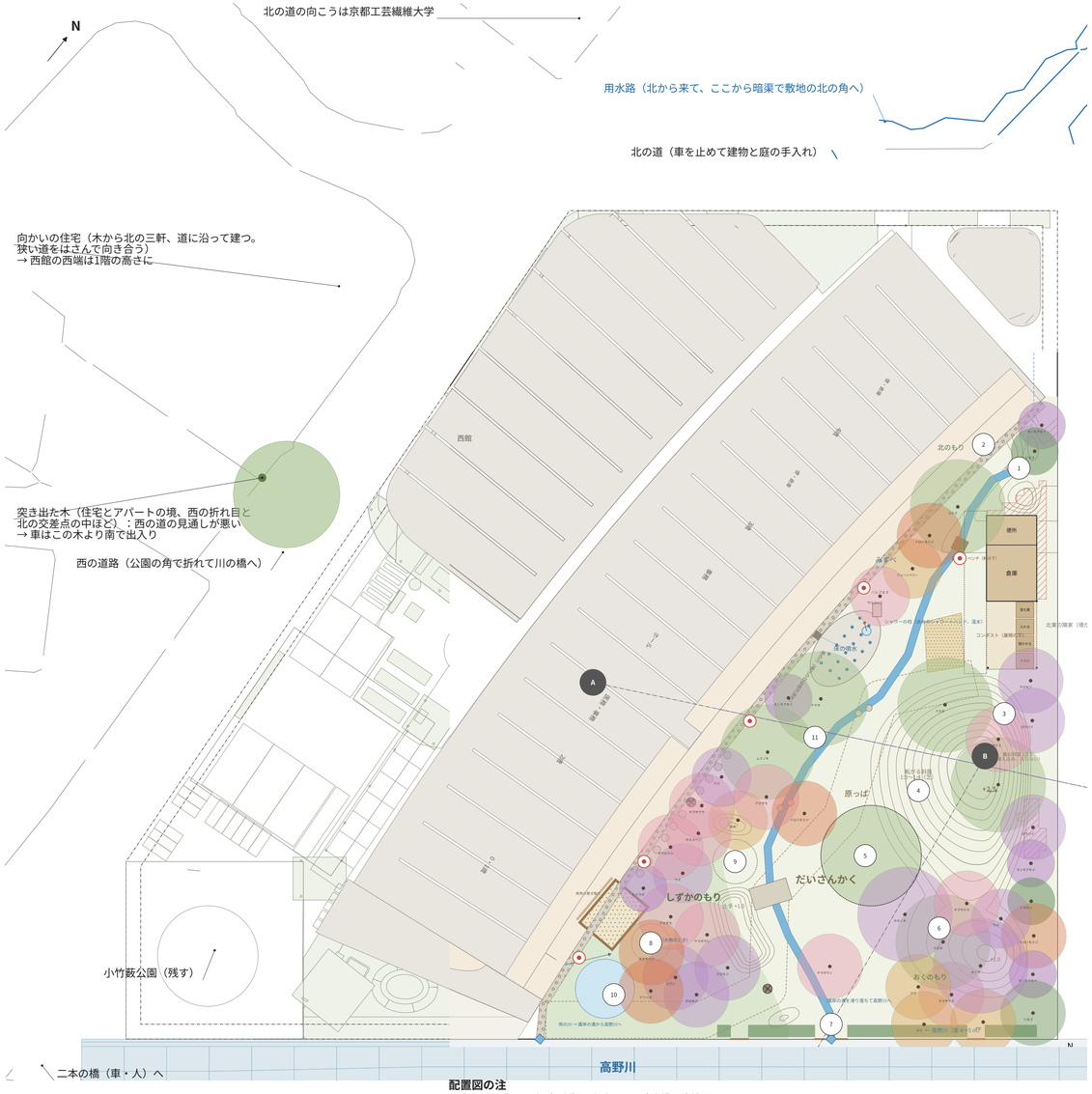
小さな図＋
のぞき（生垣の口から水面）
小川と雨の川が護岸の溝で河川敷へ
避難の帯・非常用の門から公園・河川敷へ

### 地域への配慮

小さな図＋
車は突き出た木より南（川側）で出入り
西館の西端は1階の高さ（向かいの住宅）
北東の隣家：１m・木の帯・小屋が声の衝立
小竹藪公園を残す

## 配置図　1/200　高野川を下に（川向こうから見る向き、北は右上）

点線の枠＝園庭のチャットの配置1/200（garden01）を実寸で重ねた。本番は一枚に描き直す




災害時は地下水をくみ上げて、近隣に水を届ける

0　20m

**配置図の注**
・駐車5台・搬入は南（川側）。行事の日は駐車場を駐輪に
・セキュリティの線の出入口は公園の木戸だけ
・園庭への搬入は公園の東の縁から川沿いの帯を通って
・敷地の境から：北東の隣家1 m（厳守）、ほかは1 m

## 園庭　本物に触れて遊ぶ

### 見立て

小さな図＋
築山＝比叡、小川＝高野川
ホールから頂の向こうに比叡
足もとを掘った土で盛る

### 水の行方を隠さない

小さな図＋
用水→みなもと→小川
→護岸の溝→高野川
雨は樋なしで雨の川へ

### 土と世代のめぐり

小さな図＋
野菜くず→コンポスト
→菜園→給食、余りは農家へ
柳の家を上の子が編む

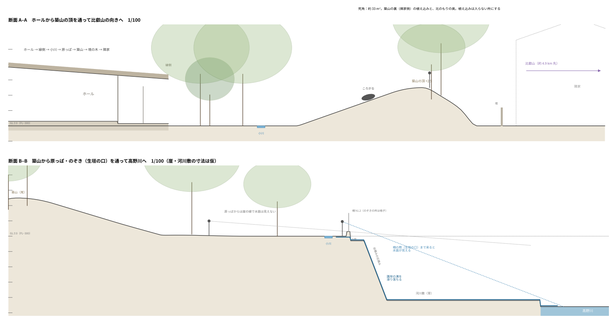
### 静かな場所と先生の目

小さな図＋
しずかのもり、ニッチ11か所
死角は植え込みだけ
取り除くのは命の危険だけ

### 模型写真　A4（入口の一枚）

園庭からこどもの目線（模型で約10 mm）
縁側・深い庇・築山の向こうに比叡の方向
選抜で最初に目に入る位置

## 園庭の断面　1/200　A 比叡へ／B 高野川・河川敷へ




［割付の注記］フォーカス：周囲の自然環境との関係（用水・比叡と高野川のうつし・河川敷）と地域への配慮、屋外遊戯場としての園庭　／　目に入る順：模型写真（入口の一枚）→ タイトルと趣旨 → 配置図と園庭 → 園庭の筋 → 自然環境と地域

# こどもたちの育ち舎　2/5　すべての人の一日　1階平面



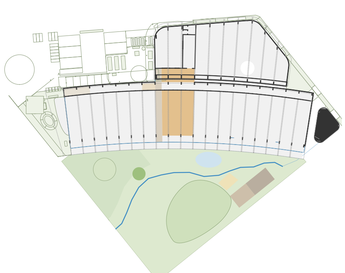



3dmから自動の平面図
（1/100、実寸）

描き足す注記：
- 各保育室の先生の席
  （机h700＋ついたて）
- 0・1歳の腰掛ける机
- 記録・連絡の机
- オープンキッチンの
  東面のガラス
- 生ごみの受け取り台
- はれのま
- 2階の休憩室は4枚目

一日の帯：上は1/700の小さな配置（建物＋園庭）、下にこども・保育士・調理の三つの一日

## 登園 8:00

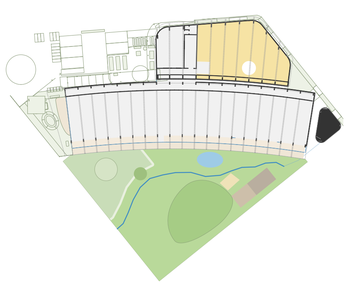


こども公園→木戸→小径→海峡。0・1歳は受け取り土間

保育士おはようの窓口で挨拶、受け取り土間で手渡し

調理　検収と下処理（南のガラス越しに見える）

## 外で遊ぶ 9:30

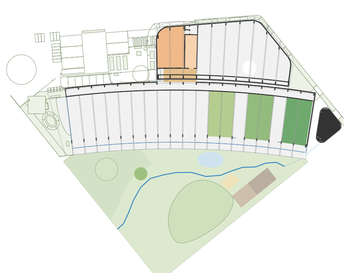


こども3〜5歳はだいさんかく、0〜2歳はしずかのもり

保育士縁側の縁に腰掛けて庭全体を見る

調理　仕込み。今日のごはんの窓にこどもが寄る

## 食べる 11:30

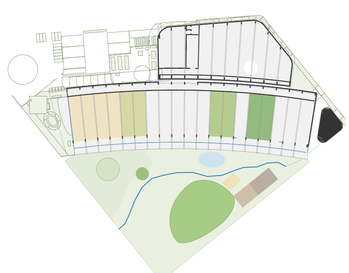


こども保育室の食卓、はれのまでクラスごと

保育士配膳口から飛び石を渡って配る。いっしょに座って食べる

調理　オープンキッチンでこどもと目が合う

## 寝る 12:45

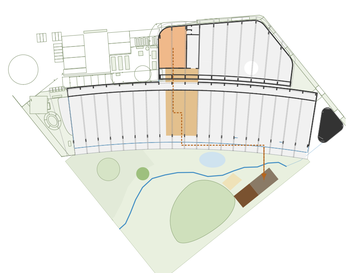


こどもねどこ・ロフトの下。起きている5歳は北の築山と遊戯室

保育士交代で2階の休憩室へ（こどもから離れる）、記録の机

調理　片付けと洗浄、おやつの仕込み

## 当番 15:00

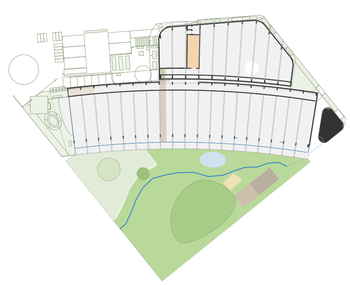


こども4・5歳のコンポスト当番：キッチン→小屋

保育士当番に付き添い、できた土を菜園へ

調理　受け取り台で野菜くずを渡す、はれのまでおやつ

## 降園 16:30



こどもはれのまで延長保育、迎えを待つ夕方の園庭

保育士縁台でお茶をしながら保護者と話す、2階で会議

調理　職員の通用口から帰る

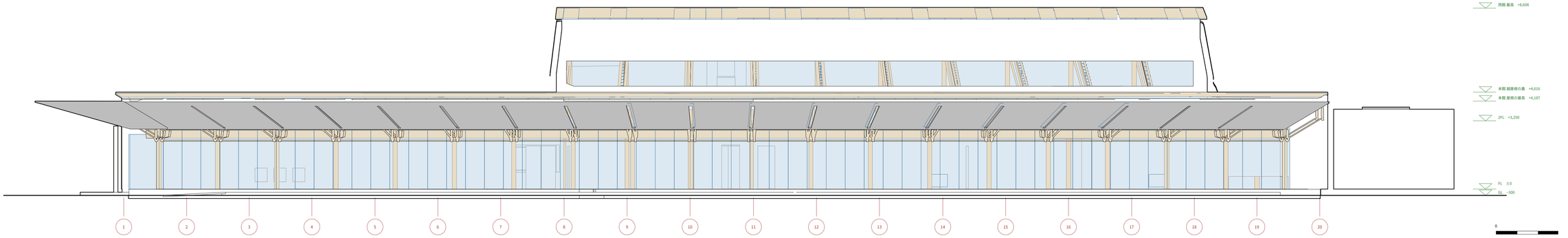
［割付の注記］フォーカス：こども・保育士・調理の職員が一日を過ごす場所としての平面（食べる・寝る・遊ぶ）　／　目に入る順：1階平面（家具・先生の席）→一日の帯（こども／保育士／調理）

# こどもたちの育ち舎　3/5　景観

建築設計実習Ⅱ－Ⅰ　2026.11.05　木田

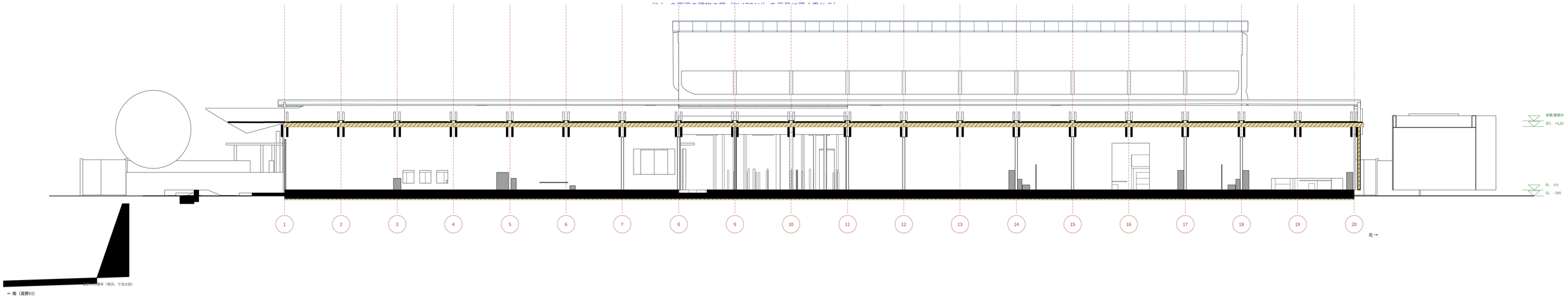
## 園庭の側の立面図　1/100　円弧の中心の方向から弧の真ん中に正対

伸びやかな梁と縁側（梁の端・庇が3 mごとに並ぶ）。屋根は屋根材型の太陽光



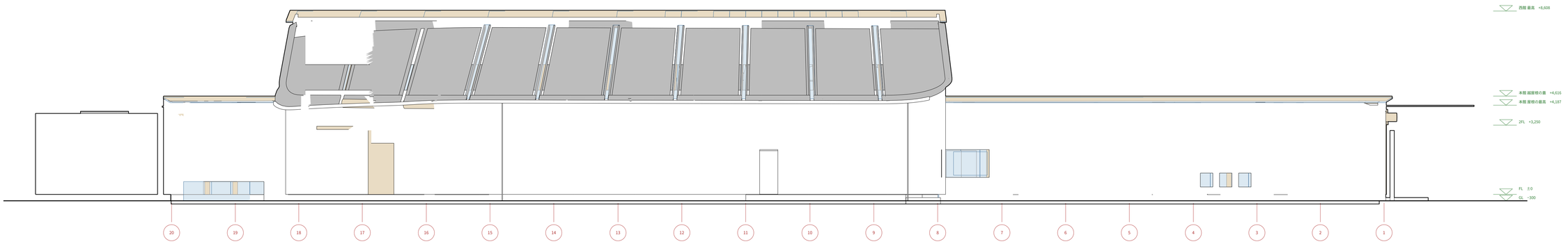

## 縦断面図A　1/100　保育室の中ほどの弧で切って展開、西を見る（左が南の高野川）

左（南）の高野川の崖から右（北）の大学へ、低い本館 → 高い西館 → おむすび。地域の建物の高低の流れに沿う

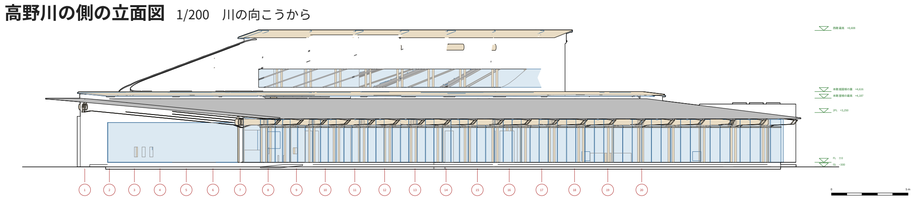



## 道路の側の立面図　1/100　西の道路から

西館の西端は1階の高さ（向かいの住宅を点線で描き足す）。西館の立ち上がりが北で主張する




## 高野川の側の立面図　1/200　川の向こうから



**夜の立面（園庭の側）**
黒地に越屋根の東の縁の光の線だけ
水平の光が一本、川向こうから見える
（模型の夜景写真でもよい）

**模型写真　鳥瞰**
敷地と高野川・崖・公園・西の道・園庭
配置図と同じ向き（高野川を手前）
川側が低く北へ高くなる流れが見える角度で

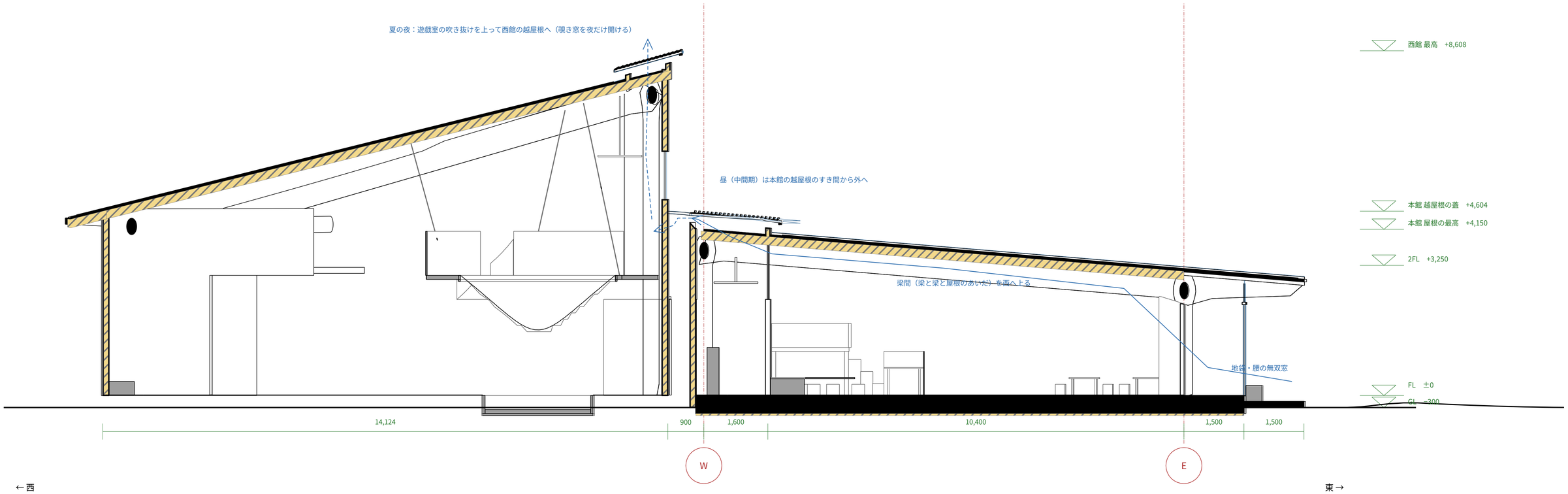
［割付の注記］フォーカス：高野川の側は低く、北の大学に向かって高く（地域の高低差の流れ）。同時に、伸びやかな梁・西館の立ち上がり・夜の水平の光で主張する　／　目に入る順：園庭の側の立面 → 縦断A（川から北へ）→ 道路の側の立面 → 高野川の側・夜

# こどもたちの育ち舎　4/5　環境



## 断面図C　4歳・遊戯室の摺鉢ネット 1/50（1/100の自動の図を2倍）　西の道路から園庭へ

矢印：昼の道（青）と夏の夜の道（紺）。床下の底板t200と断熱の帯。光の筋の光




### 運転表

**夏の昼**
庇で遮る・天井扇
床下空調（底板の冷え）

**夏の夜**
縁側の段のガラリ→床下→梁間
→越屋根・遊戯室の吹き抜け

**春・秋**
越屋根の換気口を開ける
縁側を開け放す

**冬**
換気口を閉じる・熱交換
基礎断熱・屋根の断熱

### 環境への配慮（LEED v5 Gold相当を目指す）

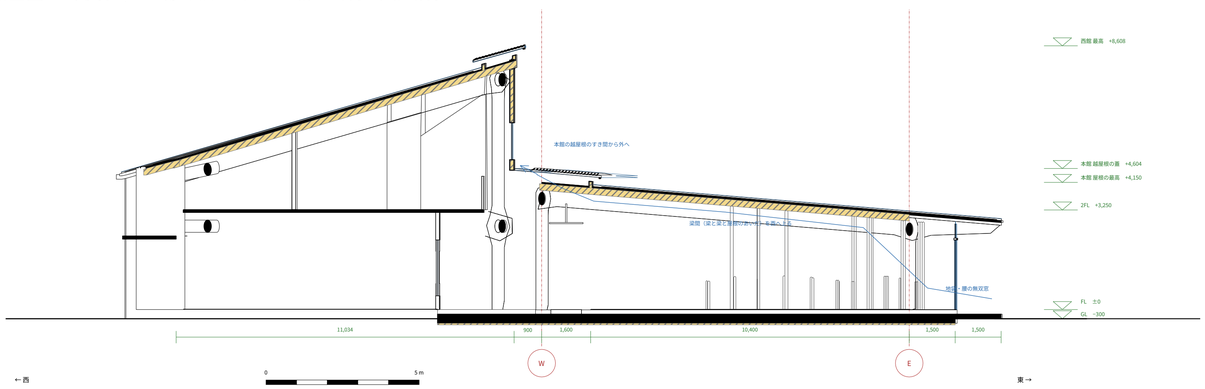
**パッシブ**
床下に冷えをためる
越屋根の通風、光の筋の昼光

**エネルギー**
屋根材型の太陽光
蓄電池（災害時の拠点）

**資源**
北山杉の間伐材（山の手入れを支える）
地域のスギ、土・雨・生ごみを敷地で回す

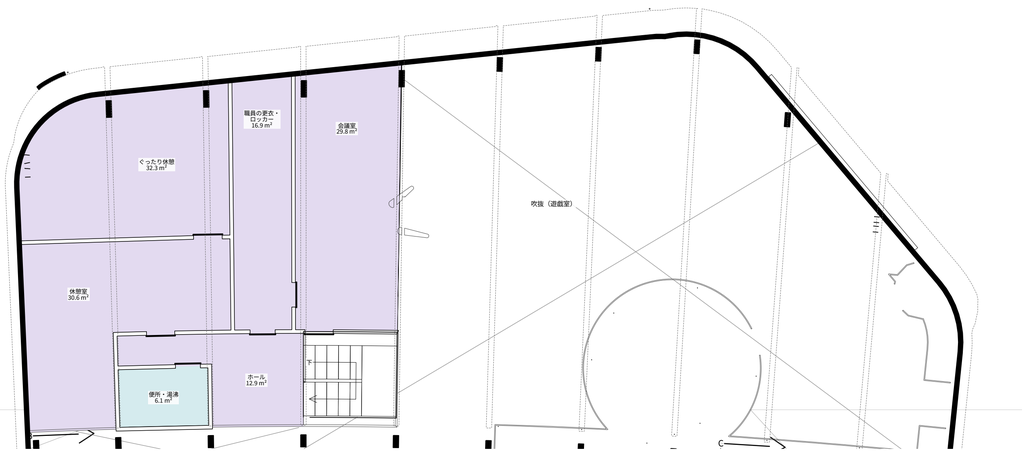
**時間**
スケルトン＆インフィル
水まわりはどのスパンにも

## 断面図B　海峡 1/100　南の入口・キッチン・2階・すき間・本館・縁側




西館2階＝職員の側（休憩室・ぐったり休憩・会議室・更衣）。こどもから離れて休む

## 西館2階平面図 1/100　職員の側




［割付の注記］フォーカス：木造・パッシブ（床下・越屋根・光の筋）で空調を補う。エネルギー・資源・時間（S&I）まで　／　目に入る順：断面C 1/50（昼と夏の夜の風、光の筋、床下）→ 運転表と4つの配慮 → 断面B → 2階（職員の側）

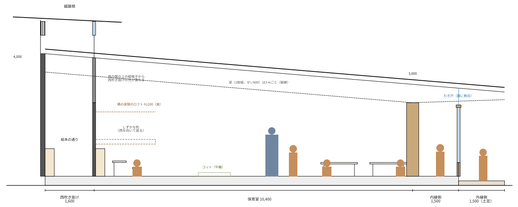
# こどもたちの育ち舎　5/5　こどもたちへの環境

建築設計実習Ⅱ－Ⅰ　2026.11.05　木田

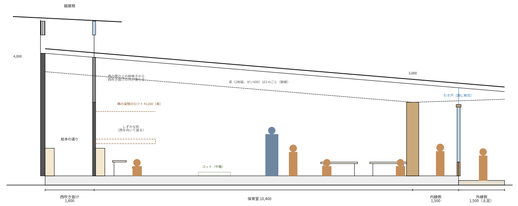
**内観　ホール（A4）**
北山杉の林・海峡と飛び石・オープンキッチン
梁の見える天井・光の筋・越屋根の光の線
（レンダリングか模型写真）

## 同じ部屋の一日　3〜5歳の保育室　断面

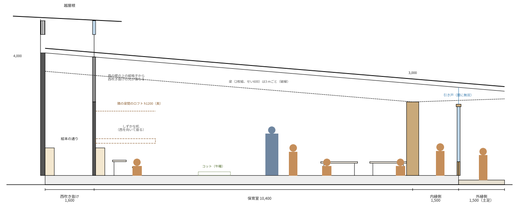
**10:00**
遊ぶ



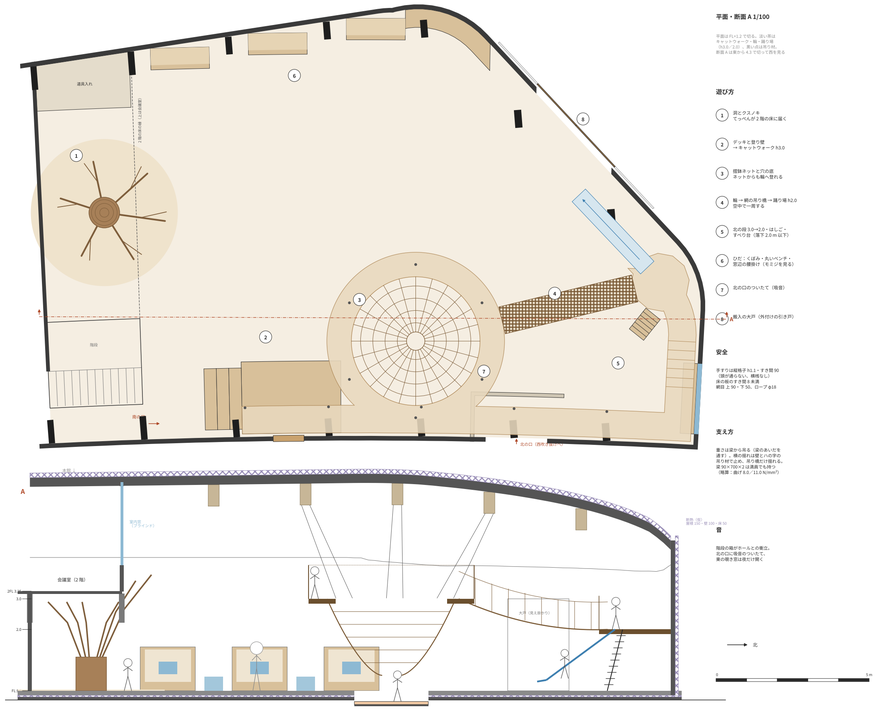
**11:30**
食べる




**13:30**
寝る

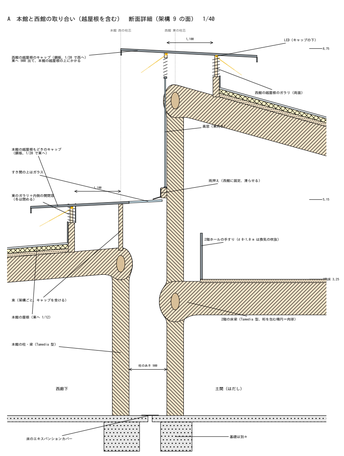


今は同じ図。部屋の分け方と天井の高低が決まったら描き分ける




## ホールの北山杉の林　こどもの目の高さ（0.9 m）から





A　木製と西面の取り合い（越屋根を含む）　断面詳細（架構 9 の面）　1/40
LED（キャップの下）
1,700
1,100
すき間のよはずり
1,200
1,100
開閉（西側に面面、薄もする）
1,100
開閉（西側に面面、薄もする）
1,100
開閉（西側に面面、薄もする）