こどもたちの育ち舎　1/5　敷地と自然環境・地域

地に足をつけて育つ

比叡から降りる冷気と高野川の流れが出会う松ヶ崎の扇状地に、こどもたちが地に足をつけて育つ場所をつくる。ゆるやかな弧を東の比叡にひらく木造平屋の本館に0歳から5歳のすべての部屋を並べ、縁側と深い庇で園庭とつなぐ。比叡に見立てた築山と、用水を借りて高野川に見立てた小川を置く。

オープンキッチンを玄関ホールに面する園の中心に据え、食べることを日々の求心力とする。野菜くずをこどもの手で土に還し、命の循環を知る。園庭には季節ごとに香る木と実のなる木を植え、こどもたちは手と鼻と舌で季節を知る。

3 mスパンの木造架構によるスケルトン＆インフィルで用途の変化を受け止める。LEED v5 Gold相当を目指す。地域から様々なものを借り、無駄をせず巡らせて、こども園として地域に返す。

設計趣旨 約332字（課題は300字程度）。文字3.6 mmなら1 m離れて読める

配置図の注

- 駐車5台・搬入は南（川側）。行事の日は駐車場を駐輪に
- セキュリティの線の出入口は公園の木戸だけ
- 園庭への搬入は公園の東の縁から川沿いの帯を通って
- 敷地の境から：北東の隣家1 m（厳守）、ほかは1 m

松ヶ崎の用水ネットワーク

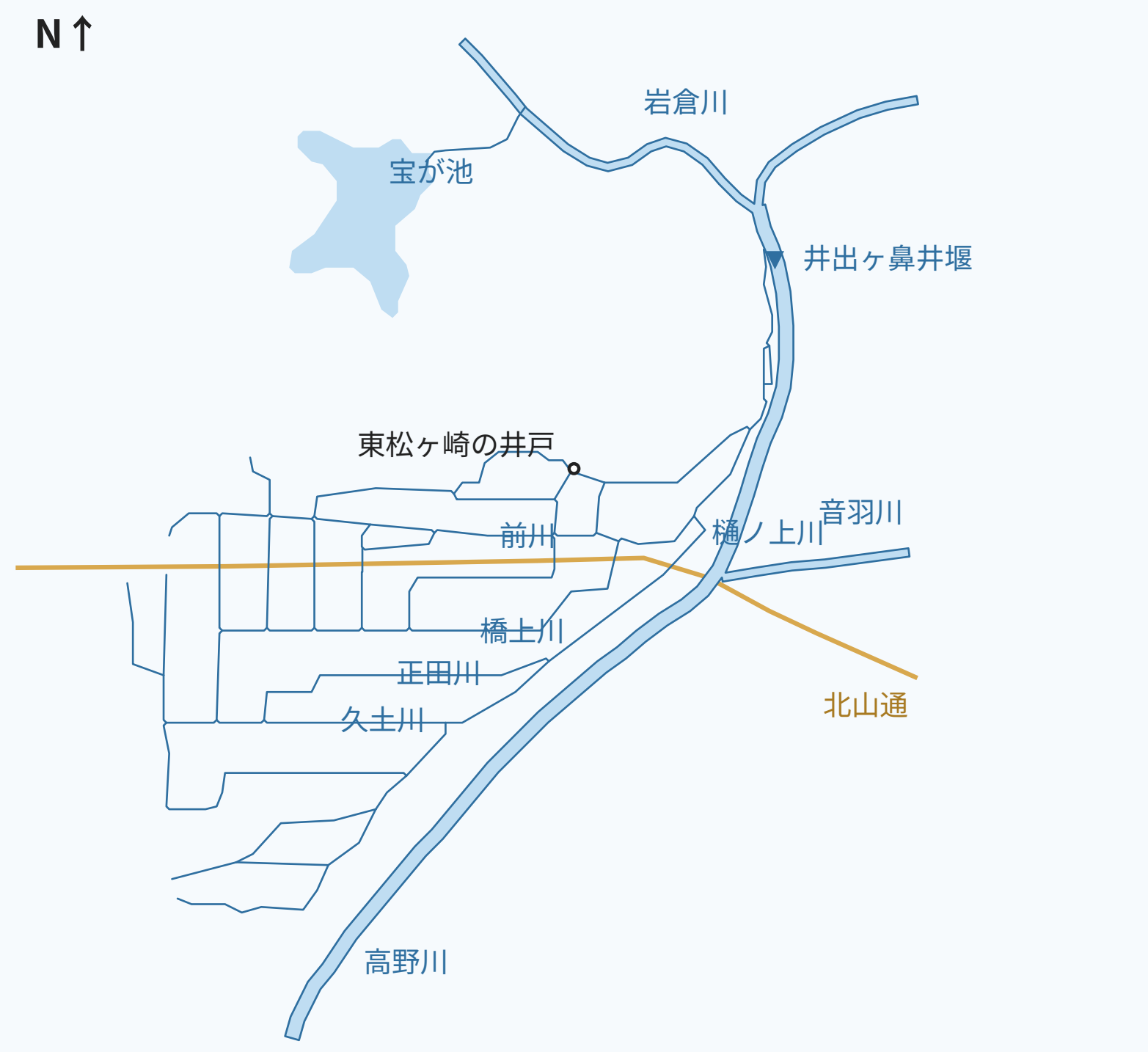
N↑
岩倉川
宝が池
井出ヶ鼻井堰
東松ヶ崎の井戸
音羽川
前川
樋ノ上川
橋上川
正田川
久土川
北山通
高野川

大正から昭和初期の図（https://kyoto-machisen.jp/chiiki_hp/matsugasaki_hp/history/history.htm）
図：http://ksdobokuisan.stars.ne.jp/80_takaragaike/takaragaike.html の図をなぞって描き直し

配置図 1/200　高野川を下に（川向こうから見る向き、北は右上）

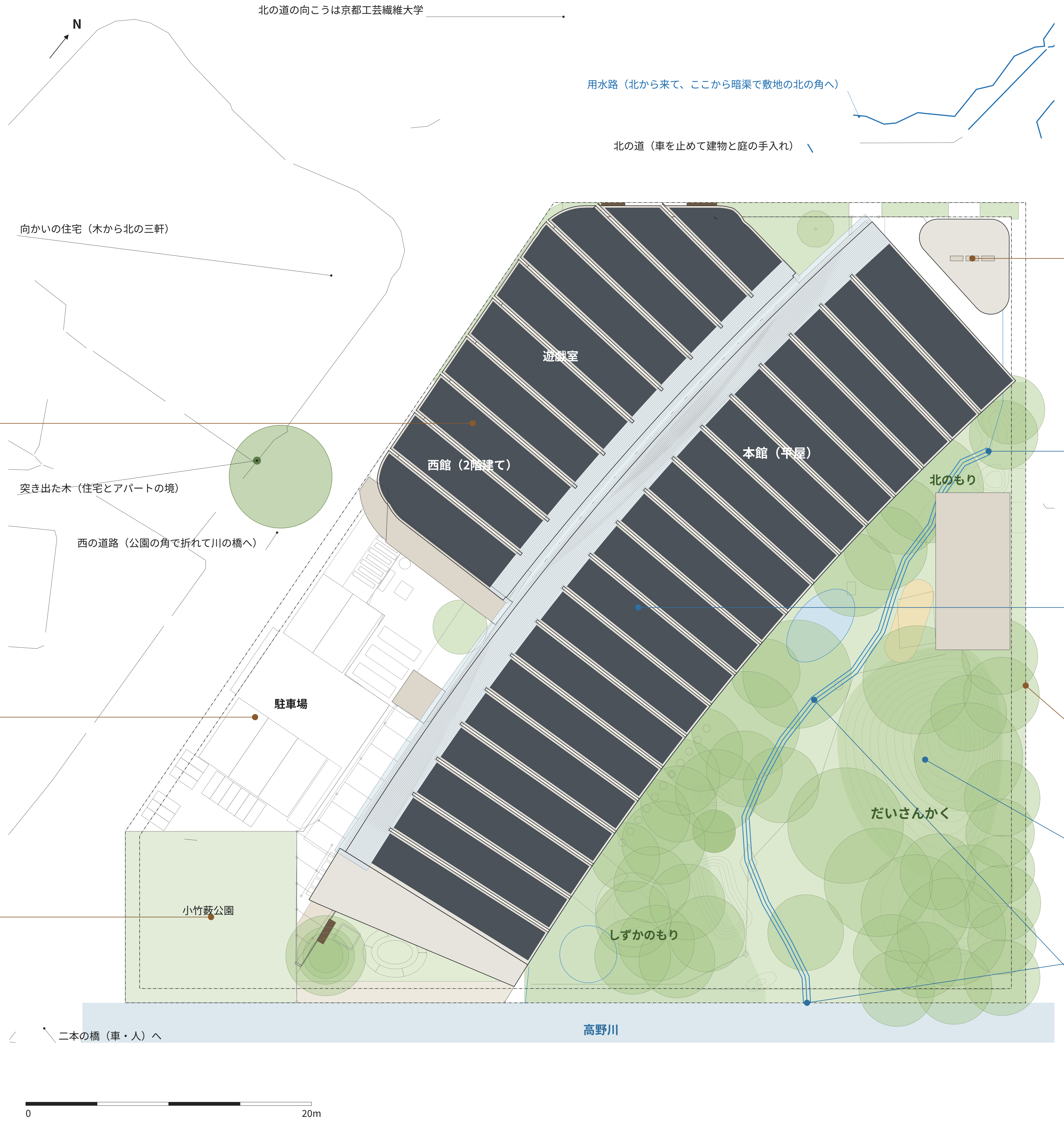
N
北の道の向こうは京都工芸繊維大学
用水路（北から来て、ここから暗渠で敷地の北の角へ）
北の道（車を止めて建物と庭の手入れ）
向かいの住宅（木から北の三軒）
遊戯室
西館（2階建て）
本館（平屋）
北のもり
突き出た木（住宅とアパートの境）
西の道路（公園の角で折れて川の橋へ）
駐車場
だいさんかく
小竹薮公園
しずかのもり
二本の橋（車・人）へ
高野川
0
20m

地域2　向かいの住宅へ

狭い道をはさんで向き合う住宅に対し、西館の西の端は1階の高さに抑えた。

地域1　車は西の道の真ん中より南で

西の道は突き出た木で見通しが悪い。外からの車の出入り（駐車・搬入）は、西の道の真ん中より南（川の側）にまとめた。

地域4　小竹薮公園を残す

地域の記憶の公園をそのまま残し、園の入口の前庭にする。

地域5　災害時に水を届ける

地下水をくみ上げて、災害時に近隣に水を届ける。屋根材型の太陽光と蓄電池で停電の時も動く。浸水（深さ1.5 m）のときは北の京都工芸繊維大学へ避難する（避難協定）。

自然1　用水を借りる

高野川の上の堰で取った水が、松ヶ崎の田を潤してきた用水の網を巡る。その水を借りる。

北の道の下の暗渠から敷地の北の角へ、北のもりのみなもとに湧き出し、小川になって高野川へ返る。

自然4　地下の水と北山の木も借りる

松ヶ崎は地面を走る用水と地下の水の両方が豊か。涌泉寺の井戸に見るように井戸水が豊富で、その地下水も借りる。

京都北山の北山杉の間伐材141本を、ホールの林に立てる。

地域3　東の隣家へ

視線と音に配慮：境から1 m、木の帯、園庭の小屋が声の衝立になる。

自然3　比叡と高野川のうつし

築山は比叡のうつし。ホールから頂の向こうに比叡が見える。

小川は高野川のうつし。足もとを掘った土で築山を盛る。

自然2　山から川へ

みなもとから縁側の前・原っぱを流れ、護岸の溝を滑り落ちて高野川に合流するまでを、こどもが追える。

雨は樋に隠さず、雨の川から同じ溝で川へ。

建築設計実習Ⅱ－Ⅰ　2026.11.05　木田

［割付の注記］フォーカス：周囲の自然環境との関係（用水を借りる・山から川へ・比叡と高野川のうつし・北山杉と地下水）と地域環境への配慮　／　目に入る順：タイトルと趣旨 → 真ん中の配置図 → 左右の箱（青＝自然環境、茶＝地域）→ 用水のネットワーク

こどもたちの育ち舎　2/5　景観

沿川の景観立面　昼　1/300　高野川の向こうから（川の辺に直角）、周りの建物とともに

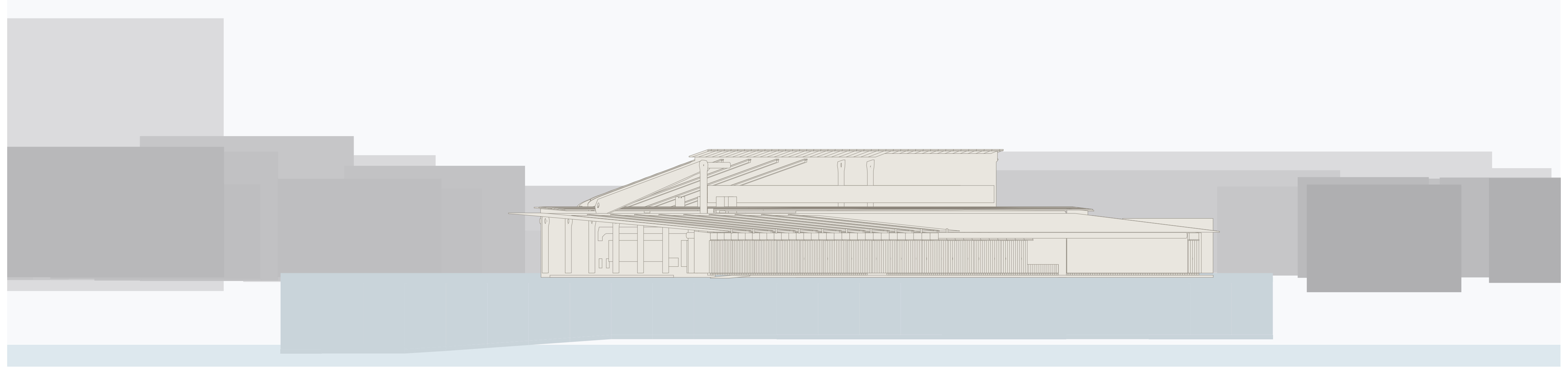

夜　越屋根の東の縁の光が水平に一本



川側は低く
北の大学へ高く
（周りの建物は
PLATEAUの箱）

園庭の側の立面図　1/100　円弧の中心の方向から弧の真ん中に正対

伸びやかな梁と縁側（梁の端・庇が3 mごとに並ぶ）。屋根は屋根材型の太陽光

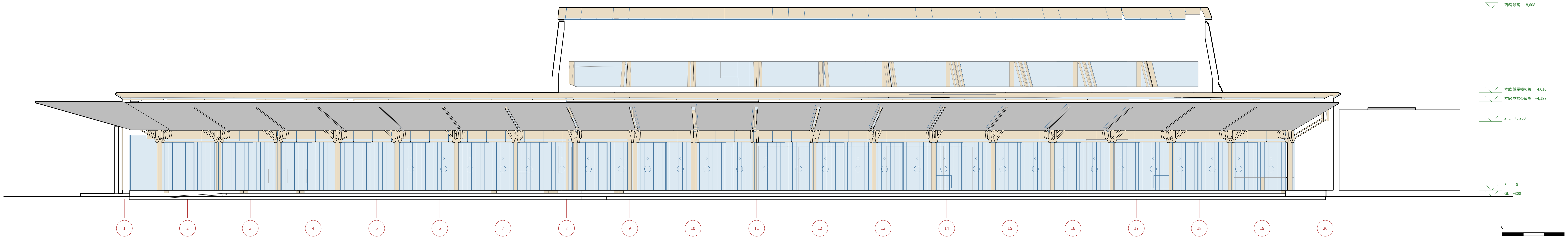
西館 最高　+8,608
本館 越屋根の蓋　+4,616
本館 屋根の最高　+4,187
2FL　+3,250
FL　±0
GL　−300
0
1
2
3
4
5
6
7
8
9
10
11
12
13
14
15
16
17
18
19
20

道路の側の立面図　1/100　西の道路から

西館の西端は1階の高さ（向かいの住宅）。西館の立ち上がりが北で主張する

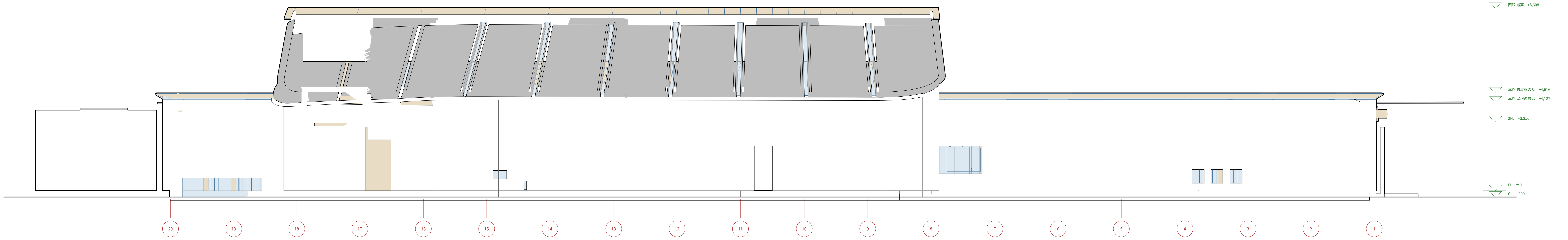
西館 最高　+8,608
本館 越屋根の蓋　+4,616
本館 屋根の最高　+4,187
2FL　+3,250
FL　±0
GL　−300
20
19
18
17
16
15
14
13
12
11
10
9
8
7
6
5
4
3
2
1

模型写真　鳥瞰
配置図と同じ向き（高野川を手前）
川側が低く北へ高くなる流れが見える角度で

景観の約束

第一種低層住居専用地域。西館の棟は約8.5 m（GLから）。

高野川特別修景地域（右岸）：河岸の樹木と清流が一体の水と緑の空間。川に面する側に植栽帯（園庭の林と生垣）、川に面する側に勾配のある下屋（南の深い軒）。深い軒と縁側、見せる北山杉の架構、スギ板、ゆるい勾配の屋根——これをいまの和風の外観とする。

遠景デザイン保全区域（高野川・修学院離宮・船岡山公園からの眺め）：外壁と屋根に禁止色を使わず、山並みと調和する色（黒い金属の屋根、木の色のまま）。

小竹薮公園と既存の木を残す。

素材と色

🟫	北山杉の柱・梁（木の色のまま）
🟫	スギ板の外壁
⬛	屋根：黒い金属（屋根材型の太陽光）
⬜	越屋根のガラスの蓋・縁側の白
🟩	生垣と園庭の緑

建築設計実習 II — I　2026.11.05　木田

［割付の注記］フォーカス：高野川の側は低く、北の大学に向かって高く（地域の高低差の流れ）。同時に、伸びやかな梁・西館の立ち上がり・夜の水平の光で主張する　／　目に入る順：沿川の景観立面（昼・夜）→ 園庭の側・道路の側の立面図 → 鳥瞰・景観の約束・素材と色

こどもたちの育ち舎　3/5　平面図　1階・2階

平面図　1階　FL+1200 で切断／2階（西館）2FL+1200 で切断　1/100

高野川を下に（配置図と同じ向き）。2階は西の道路の外に同じ向きで置いた（遊戯室は吹き抜けから見下ろす）。一点鎖線は敷地の境

吹抜（遊戯室）
遊戯室 243.5 m²
会議室 29.8 m²
職員の更衣・ロッカー 16.9 m²
ぐったり休憩 32.3 m²
休憩室 30.6 m²
ホール 12.9 m²
便所・湯沸 6.1 m²
吹抜
下
遊戯室 243.5 m²
調理の更衣・便所・前室 6.3 m²
食べる土間 22.0 m²
キッチン 59.4 m²
倉庫 3.9 m²
階段 3.3 m²
上
倉庫 4.6 m²
倉庫 6.9 m²
東の帯 24.3 m²
西吹き抜け 64.0 m²
ホール 75.3 m²
多目的便所 8.0 m²
事務 9.7 m²
園長室・応接 12.6 m²
便所 3.0 m²
倉庫 3.6 m²
通り抜け 15.2 m²
3歳 60.4 m²
便所 8.6 m²
4歳 60.3 m²
倉庫 6.5 m²
通り抜け 15.2 m²
5歳 60.7 m²
便所 8.6 m²
事務 4.9 m²
静養室 8.6 m²
医務 21.5 m²
西吹き抜け 11.4 m²
2歳 60.0 m²
0・1歳 120.5 m²
受け取り土間 11.2 m²
A
B
B
C
N
W
E
1
2
3
4
5
6
7
8
9
10
11
12
13
14
15
16
17
18
19
3,000
19 × 3,000 = 57,000（背骨 r=205 m で）

部屋の色

- 🟩 0・1歳〜5歳
- 🟨 こどものみんなの場所（遊戯室・はれのま）
- ▨ 通り・つなぐ場所（はだし）
- ▨ 土足の床
- 🟪 大人の場所
- 🟪 キッチン・調理の更衣
- ▨ 水まわり

0　5 m

こどもたちの育ち舎　3dm（sodachiya.3dm）から自動で作図　2026-10-25 09:01（atelier b33de10 の次の版の 3dm）

こどもたちの育ち舎　4/5　こどもたちと働く人たちの環境

一日の帯：上は1/600の小さな配置（建物＋園庭）と三者の動線（こども緑・保育士茶・調理青）、下にそれぞれの一日

登園 8:00

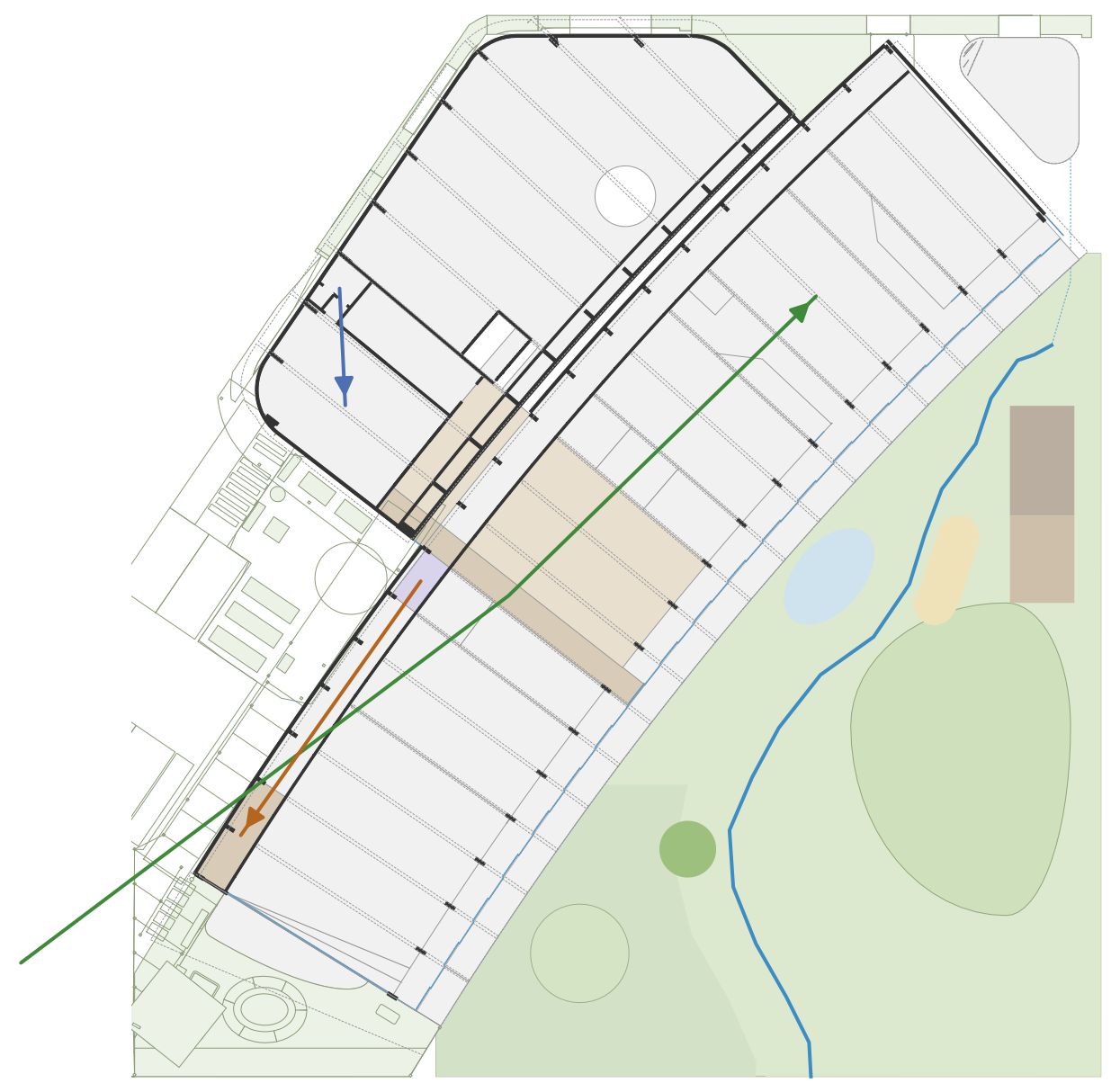

こども公園→木戸→小径→海峡。0・1歳は受け取り土間

保育士おはようの窓口で挨拶、受け取り土間で手渡し

調理　検収と下処理（南のガラス越しに見える）

外で遊ぶ 9:30

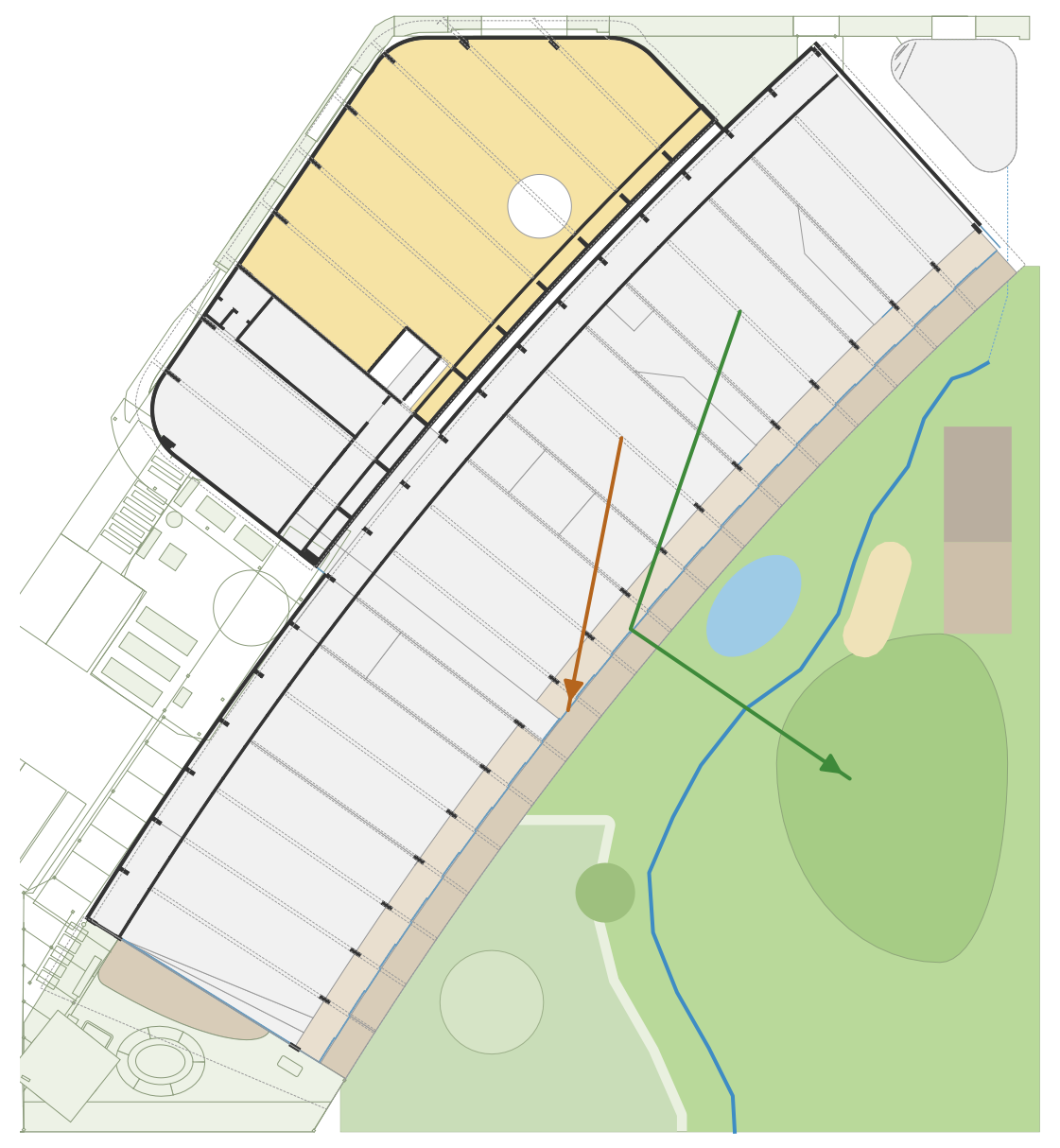

こども3〜5歳はだいさんかく、0〜2歳はしずかのもり

保育士縁側の縁に腰掛けて庭全体を見る

調理　仕込み。今日のごはんの窓にこどもが寄る

食べる 11:30

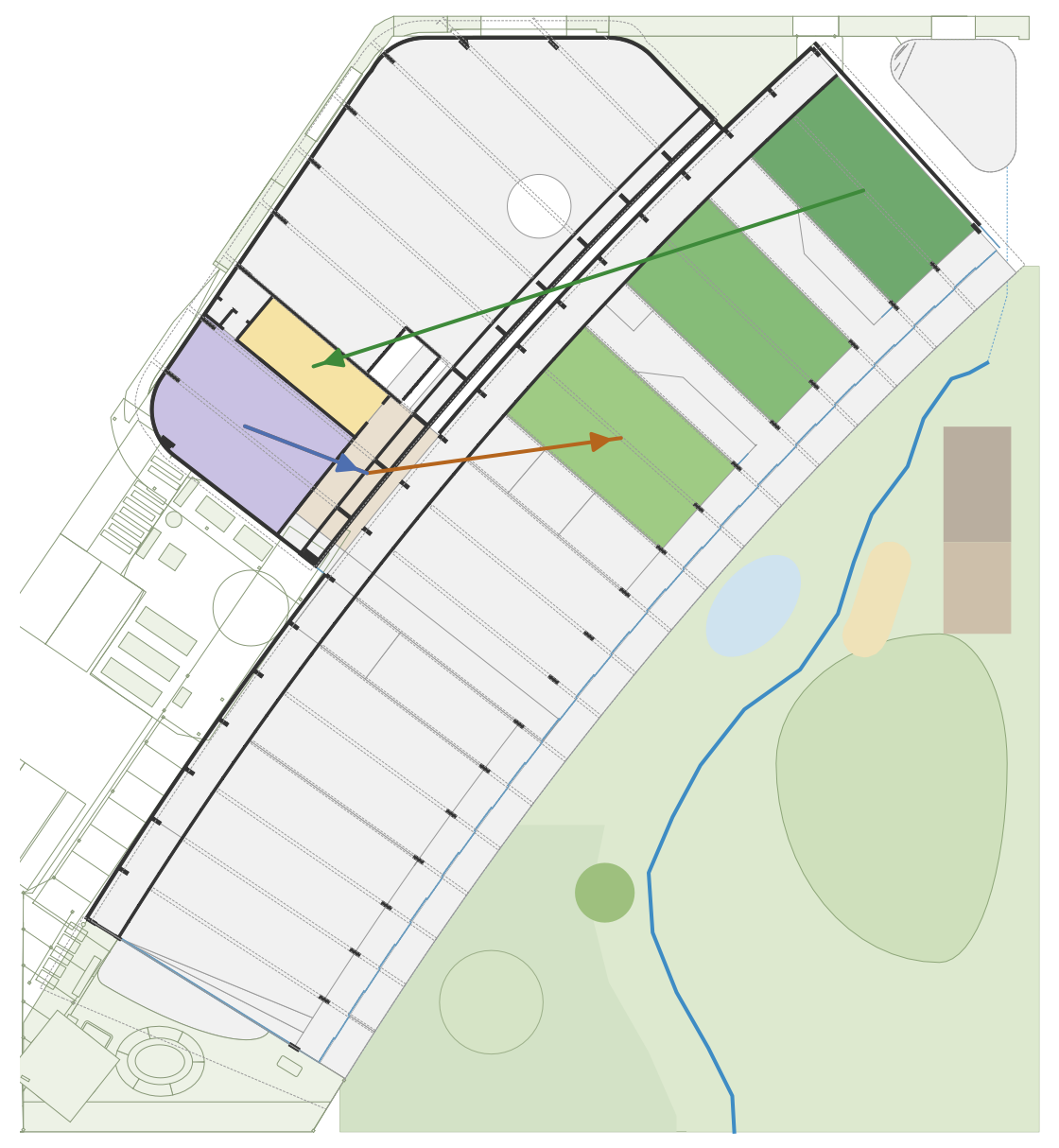

こども保育室の食卓、はれのまでクラスごと

保育士配膳口から飛び石を渡って配る。いっしょに座って食べる

調理　オープンキッチンでこどもと目が合う

寝る 12:45

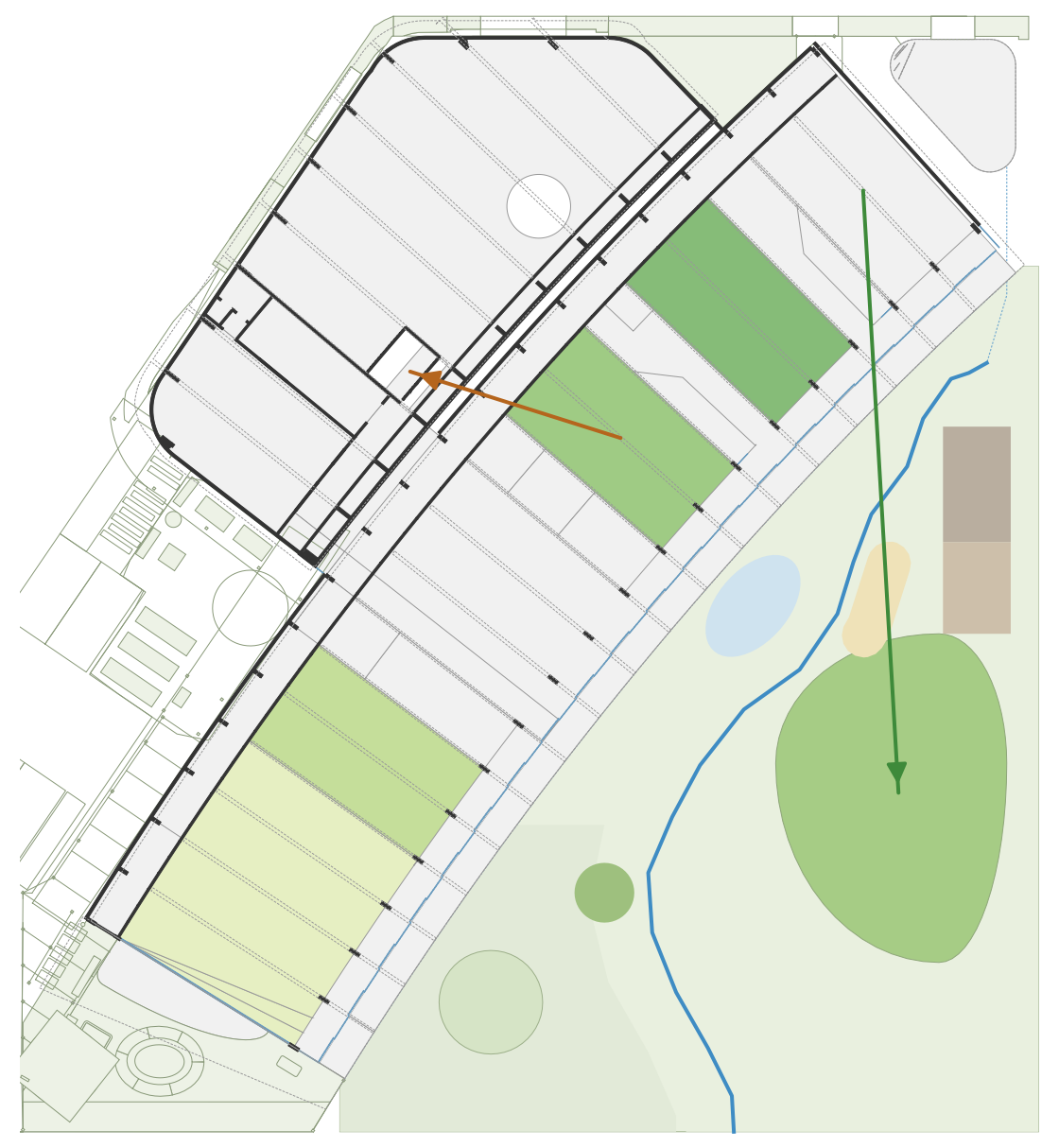

こどもねどこ・ロフトの下。起きている5歳は北の築山と遊戯室

保育士交代で2階の休憩室へ（こどもから離れる）、記録の机

調理　片付けと洗浄、おやつの仕込み

当番 15:00

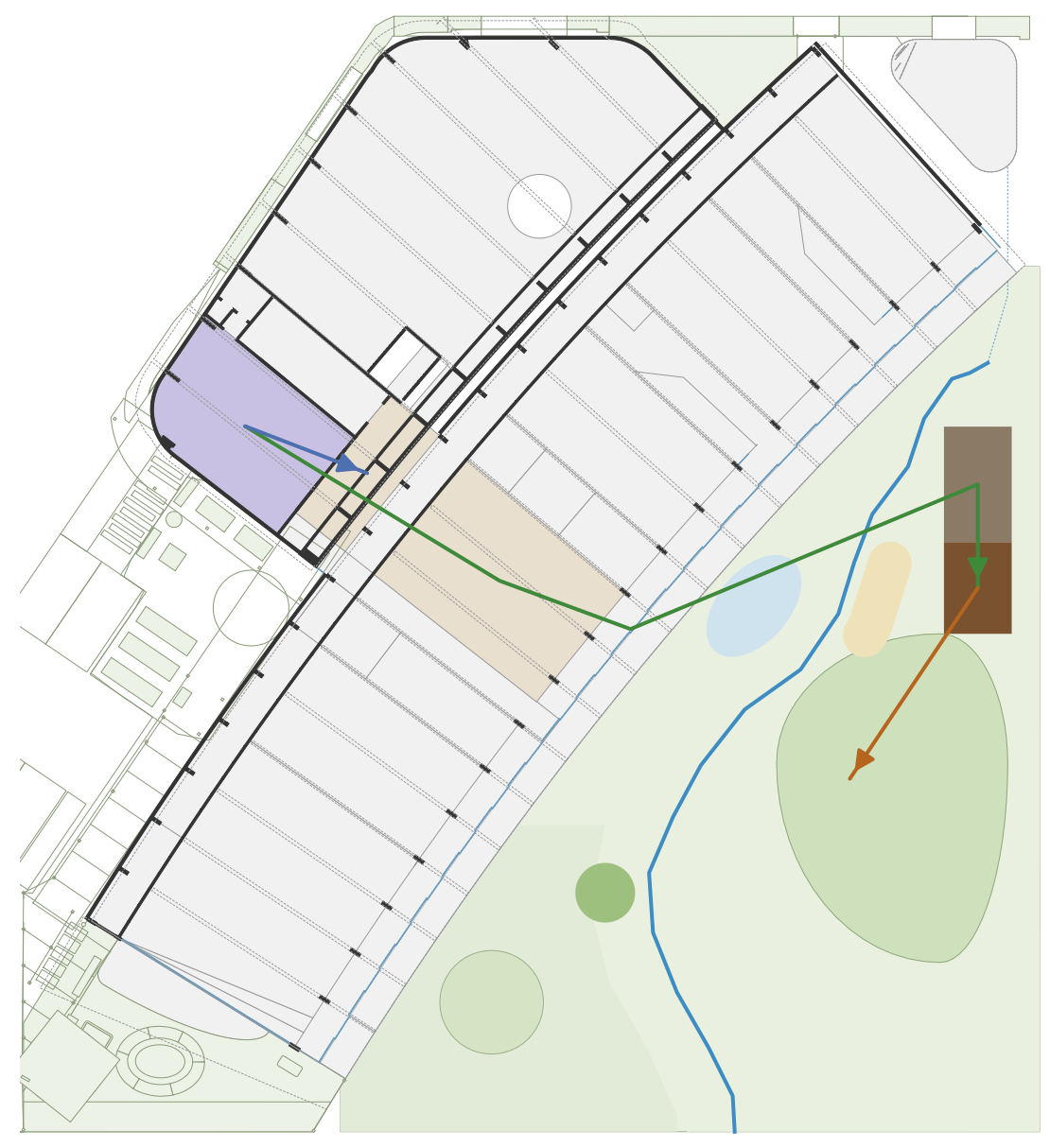

こども4・5歳のコンポスト当番：キッチン→小屋

保育士当番に付き添い、できた土を菜園へ

調理　受け取り台で野菜くずを渡す、はれのまでおやつ

降園 16:30

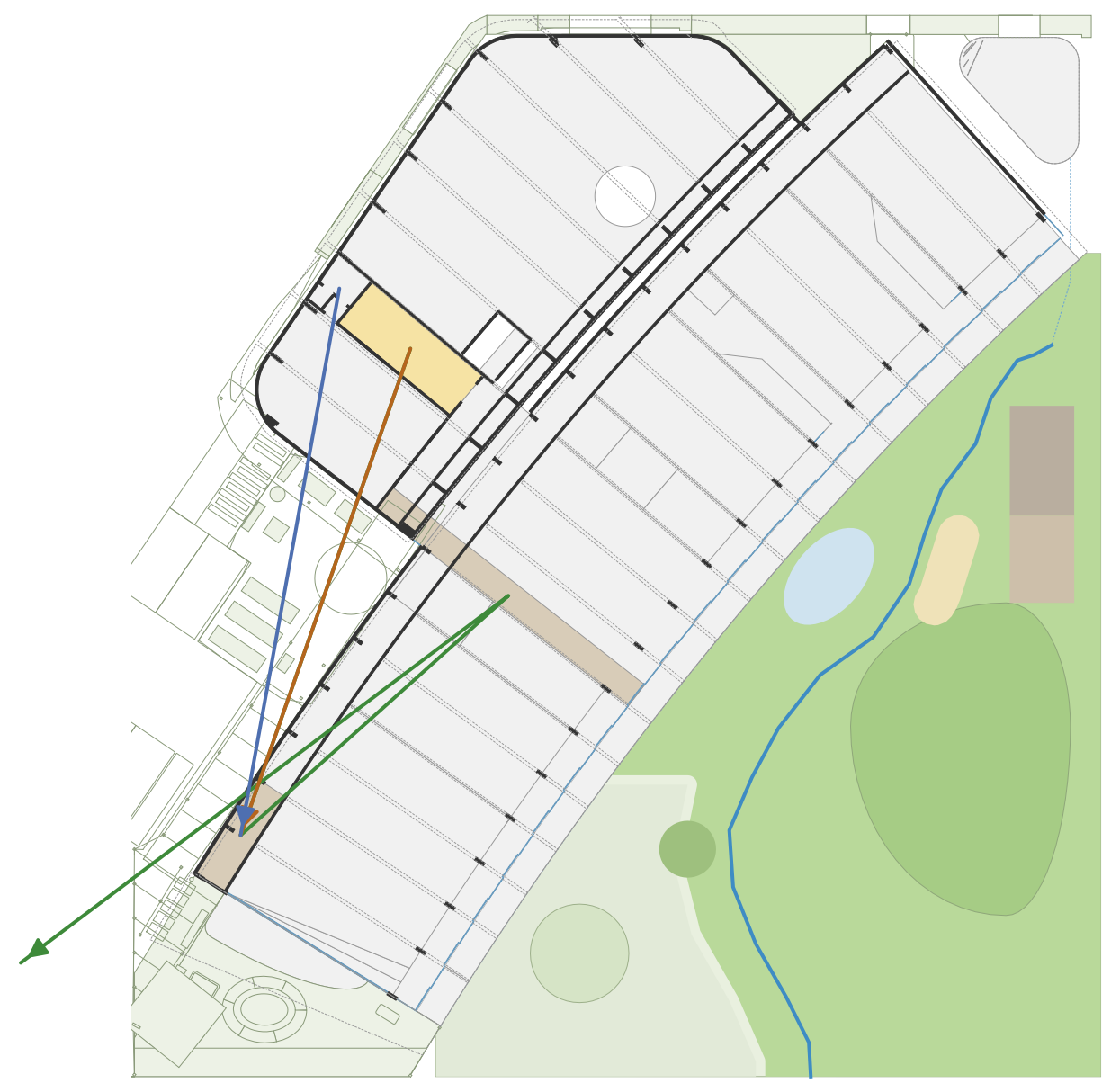

こどもはれのまで延長保育、迎えを待つ夕方の園庭

保育士縁台でお茶をしながら保護者と話す、2階で会議

調理　職員の通用口から帰る

透視図（A4）　模型写真か彩色の透視図

こどもの目の高さで、園庭から縁側とホールの北山杉の林を見る
梁の見える天井・光の筋・オープンキッチン

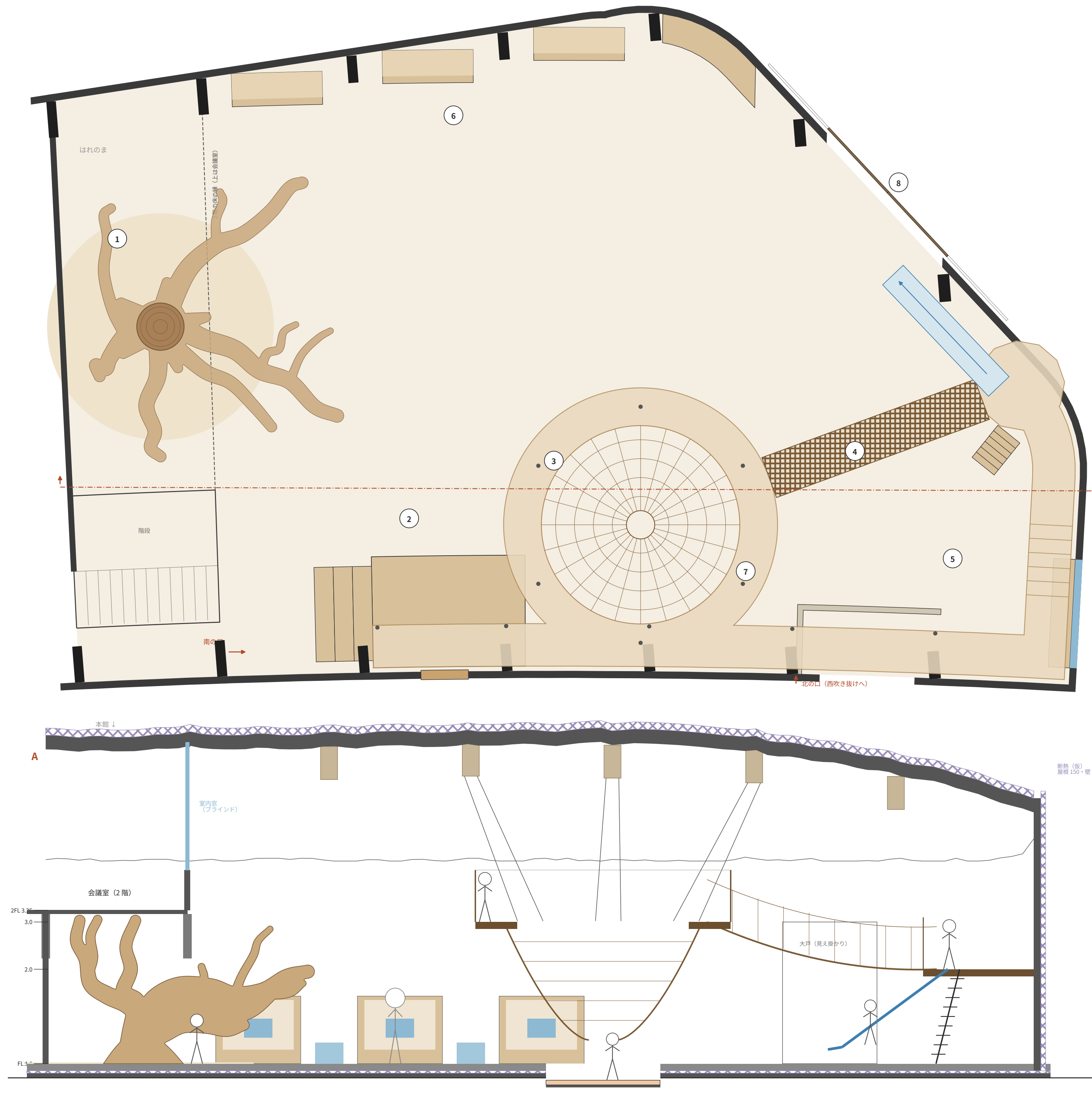

平面・断面 A 1/100

平面は FL+1.2 で切る。淡い茶はキャットウォーク・輪・踊り場（h3.0／2.0）、黒い点は吊り材。断面 A は東から 4.3 で切って西を見る

遊び方

① 洞とクスノキ　てっぺんが 2 階の床に届く
② デッキと登り壁　→ キャットウォーク h3.0
③ 擂鉢ネットと穴の底　ネットからも輪へ登れる
④ 輪 → 網の吊り橋 → 踊り場 h2.0　空中で一周する
⑤ 北の段 3.0→2.0・はしご・すべり台（落下 2.0 m 以下）
⑥ ひだ：くぼみ・丸いベンチ・窓辺の腰掛け（モミジを見る）
⑦ 北の口のついたて（吸音）
⑧ 搬入の大戸（外付けの引き戸）

安全

手すりは縦格子 h1.1・すき間 90（頭が通らない、横桟なし）
床の板のすき間 8 未満
網目 上 90・下 50、ロープ φ18

支え方

重さは梁から吊る（梁のあいだを通す）。横の揺れは壁とハの字の吊り材で止め、吊り橋だけ揺れる。梁 90×700×2 は満員でも持つ（略算：曲げ 8.0／11.0 N/mm²）

断熱（仮）屋根 150・壁 100・床 50

音

階段の箱がホールとの衝立。北の口に吸音のついたて、東の覗き窓は夜だけ開く

→ 北

0　5 m

見立て

築山は比叡、小川は高野川。足もとを掘った土で盛る。

水の行方を隠さない

用水→みなもと→小川→護岸の溝→高野川。雨は樋なしで。

土と命のめぐり

野菜くずはこどもの手でコンポストへ、土に還す。ミミズに驚く。

季節を手と鼻と舌で

季節ごとに香る木と実のなる木。とげの木は一本だけ、わざと。

静かな場所と先生の目

関守石で「ここからはしずかに」。取り除くのは命に関わる危険だけ。

園庭　約1/440（配置1/200を縮小）

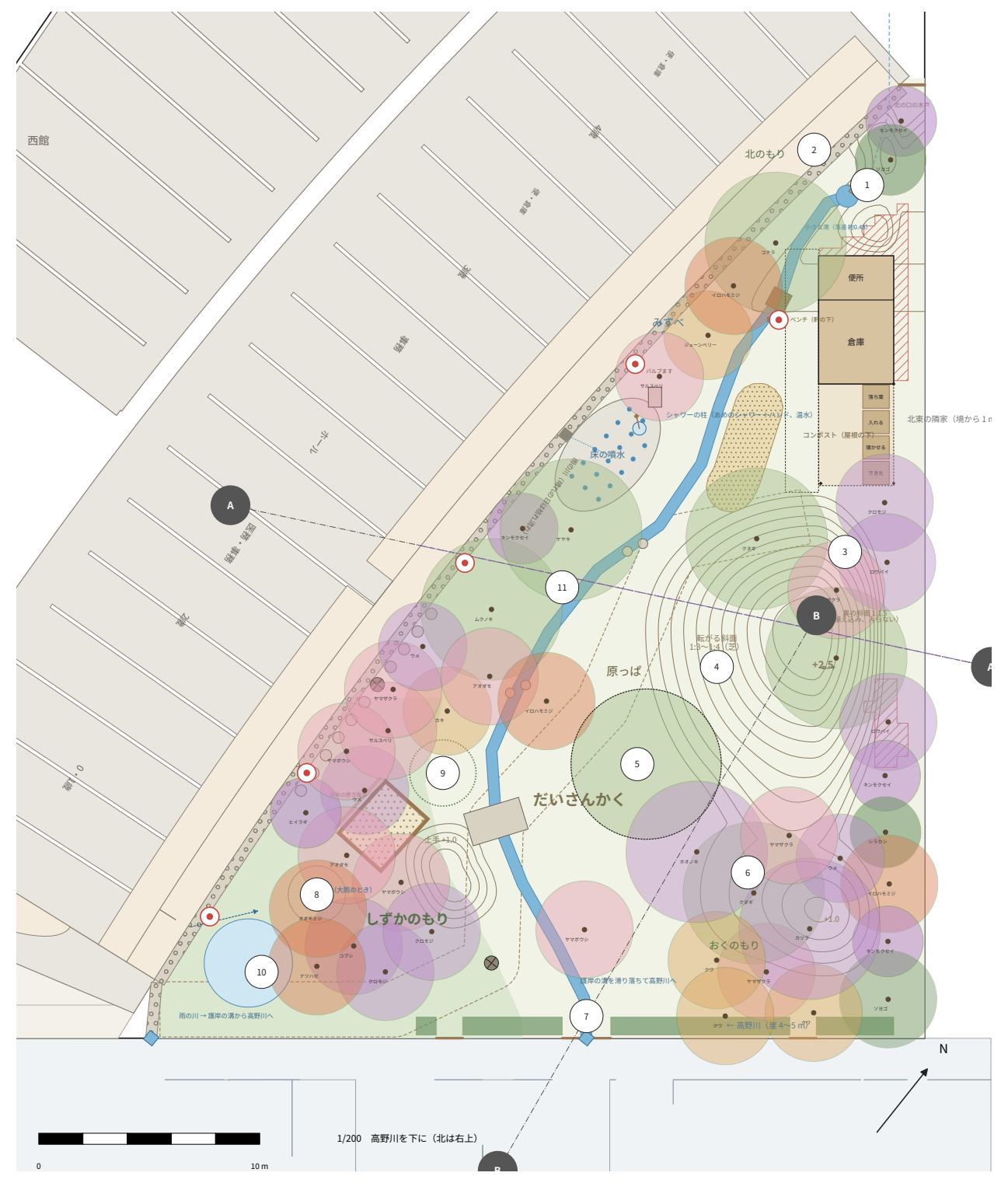

ホールの北山杉の林　こどもの目の高さから

ホールの北山杉の林　こどもの目の高さ（0.9 m）から見た景色　（たたき台・6 版：すべて自立）

円筒投影（横＝方位 110°、縦＝仰角）。幹は北山杉（φ50 は磨き丸太、群の φ70・100 は太鼓落とし＝両側を平らに挽いた丸太、平らな面を列の向きにそろえる）。奥の色：うす緑＝縁側のガラス越しの園庭、ベージュ＝壁、橙＝キッチンのガラス、灰＝海峡。低い木（0.85〜1.1）はこどもの目の高さを隠し、高い木は屋根の近くまで



A　海峡から北を見る（登園のこども）　目の高さで幹に隠れる割合 54%

B　外縁側から西を見る（園庭から入ってくる）　目の高さで幹に隠れる割合 37%

洞のクスノキ　遊戯室の切り株

断面パース　スパン 11 の北の端（u 32.9）で切って南を見る



洞のクスノキ

2 階の床の下の低い洞（梁の下 2.23）。クスノキの枝の先が天井に触れ、木が 2 階を支えているように見える。
北の枝は床の縁の下をくぐって遊戯室の高い側へ（この図では切断面で切れている）。

園庭の断面　A 比叡へ／B 高野川へ（縮小）

死角：約 33 m²。築山の裏（隣家側）の植え込みと、北のもりの奥。植え込みは入らない所にする

断面 A–A　ホールから築山の頂を通って比叡山の向きへ　1/100

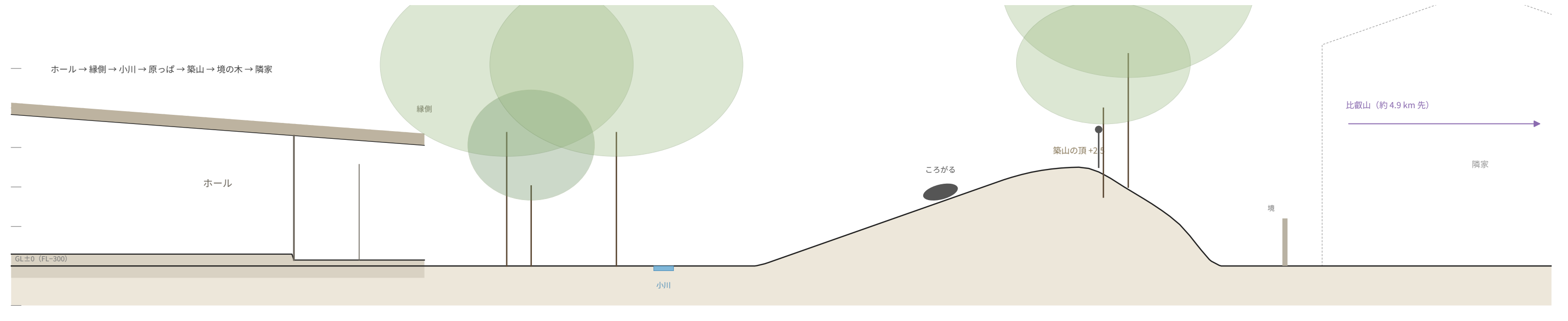

断面 B–B　築山から原っぱ・のぞき（生垣の口）を通って高野川へ　1/100（崖・河川敷の寸法は仮）

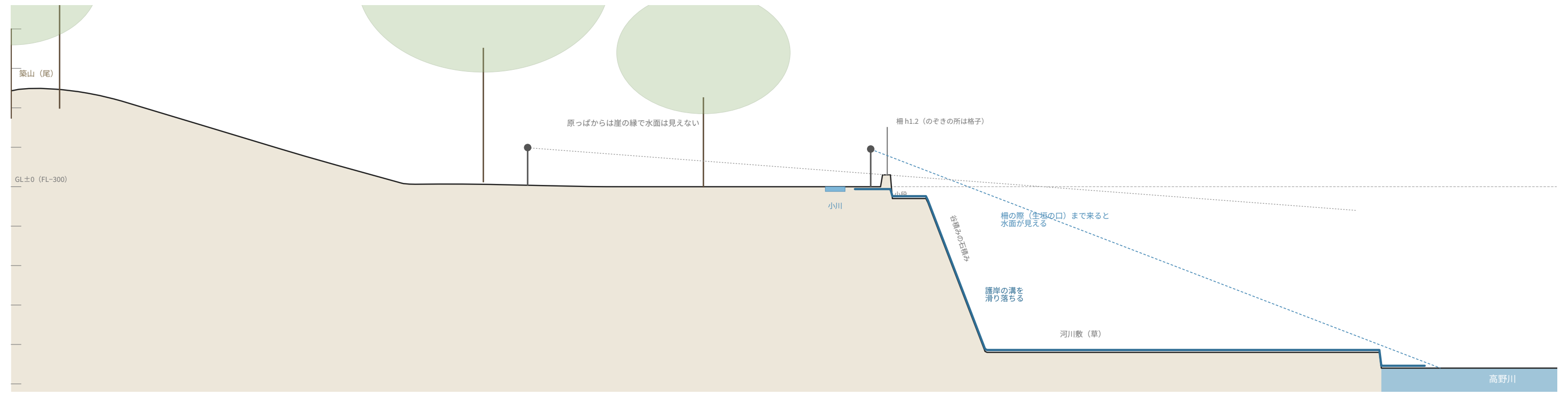

築山（尾）
原っぱからは崖の縁で水面は見えない
柵 h1.2（のぞきの所は格子）
GL±0（FL−300）
小川
柵の際（生垣の口）まで来ると水面が見える
谷積みの石積み
護岸の溝を滑り落ちる
河川敷（草）
高野川

建築設計実習 II — I　2026.11.05　木田

［割付の注記］フォーカス：すべての人の一日（こども・保育士・調理）と、こどもたちが地に足をつけて育つ場所：透視図・遊戯室・園庭・北山杉の林　／　目に入る順：一日の帯と動線 → 透視図（A4）→ 遊戯室 → 園庭の5つ → 園庭・林・洞・断面

こどもたちの育ち舎　5/5　環境

断面図C　東西に切る（4歳・遊戯室の擂鉢ネット）

1/75（1/100の自動の図を1.5倍）　西の道路から園庭へ

矢印：昼の道（青）と夏の夜の道（紺）。床下の底板t200と断熱の帯。光の筋の光

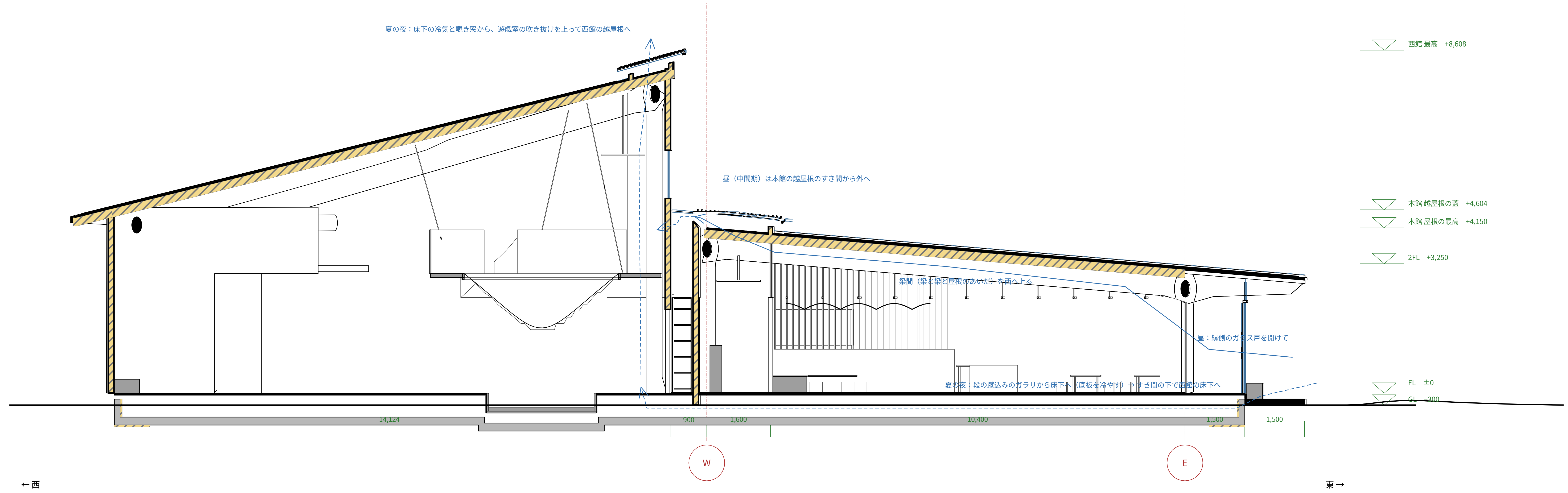
夏の夜：床下の冷気と覗き窓から、遊戯室の吹き抜けを上って西館の越屋根へ
昼（中間期）は本館の越屋根のすき間から外へ
梁間（梁と梁と屋根のあいだ）を西へ上る
昼：縁側のガラス戸を開けて
夏の夜：段の蹴込みのガラリから床下へ（底板を冷やす）→ すき間の下で西館の床下へ
西館 最高　+8,608
本館 越屋根の蓋　+4,604
本館 屋根の最高　+4,150
2FL　+3,250
FL　±0
GL　−300
14,124
900
1,600
10,400
1,500
1,500
W
E
←西
東→

運転表

夏の昼
庇・天井扇
床下空調

夏の夜
床下→梁間
→越屋根・遊戯室

春・秋
越屋根を開ける
縁側を開け放す

冬
換気口を閉じる
熱交換・断熱

環境への配慮（LEED v5 Gold相当）

パッシブ
床下に冷えをためる
通風・光の筋

エネルギー
屋根材型の太陽光
蓄電池

資源
北山杉の間伐材
土・雨・生ごみを回す

時間
S&I
水まわりはどこでも

縦断面図A

1/100　保育室の中ほどの弧で切って展開、西を見る（左が南の高野川）

1
2
3
4
5
6
7
8
9
10
11
12
13
14
15
16
17
18
19
20
本館 屋根の
2FL　+3,25
FL　±0
GL　−300
北→
高野川の護岸（現況、寸法は仮）
←南（高野川）

断面図B　海峡

1/100　南の入口・キッチン・2階・すき間・本館・縁側

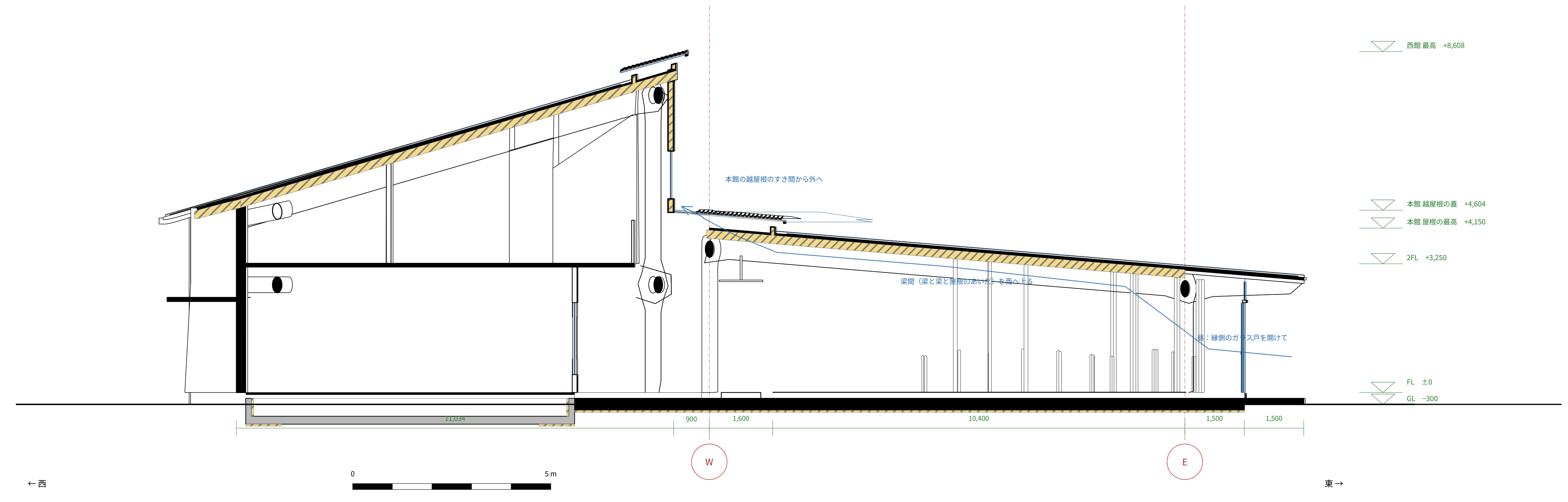
本館の越屋根のすき間から外へ
梁間（梁と梁と屋根のあいだ）を西へ上る
昼：縁側のガラス戸を開けて
西館 最高　+8,608
本館 越屋根の蓋　+4,604
本館 屋根の最高　+4,150
2FL　+3,250
FL　±0
GL　−300
11,034
900
1,600
10,400
1,500
1,500
W
E
0
5 m
←西
東→

スケルトン＆インフィル
3 mスパンの架構（固定）と
間仕切り・家具（可変）
今／定員が変わる／地域の場

光の筋と架構　1/20
2枚の梁のあいだ180の上に
乳白ガラス

inspired by

Asilo Nido Iride
Mario Cucinella Architects・Guastalla・2015
→ 梁の列が並ぶ長細い本館と、外に付く付属の建物

Tamedia
坂茂・Zürich・2013
→ 梁の端の楕円の頭と、それを貫く楕円の桁

レイモンド斑鳩こども園
キノアーキテクツ・斑鳩・2026
→ 室内に木を立てる（ホールの北山杉）

KAIT工房
石上純也・厚木・2008
→ 柱の配列：見る向きで景色が変わる並び

認定こども園らみどり
はりゅうウッドスタジオ・須賀川・2026
→ 内と外の二重の縁側、遊具を置かない地形の園庭

仙田満の園舎
環境デザイン研究所
→ 擂鉢のネット、キャットウォーク、ニッチ

Waldorf School of the Peninsula
California
→ 遊戯室の切り株

接合部（2枚の梁で柱を挟む）

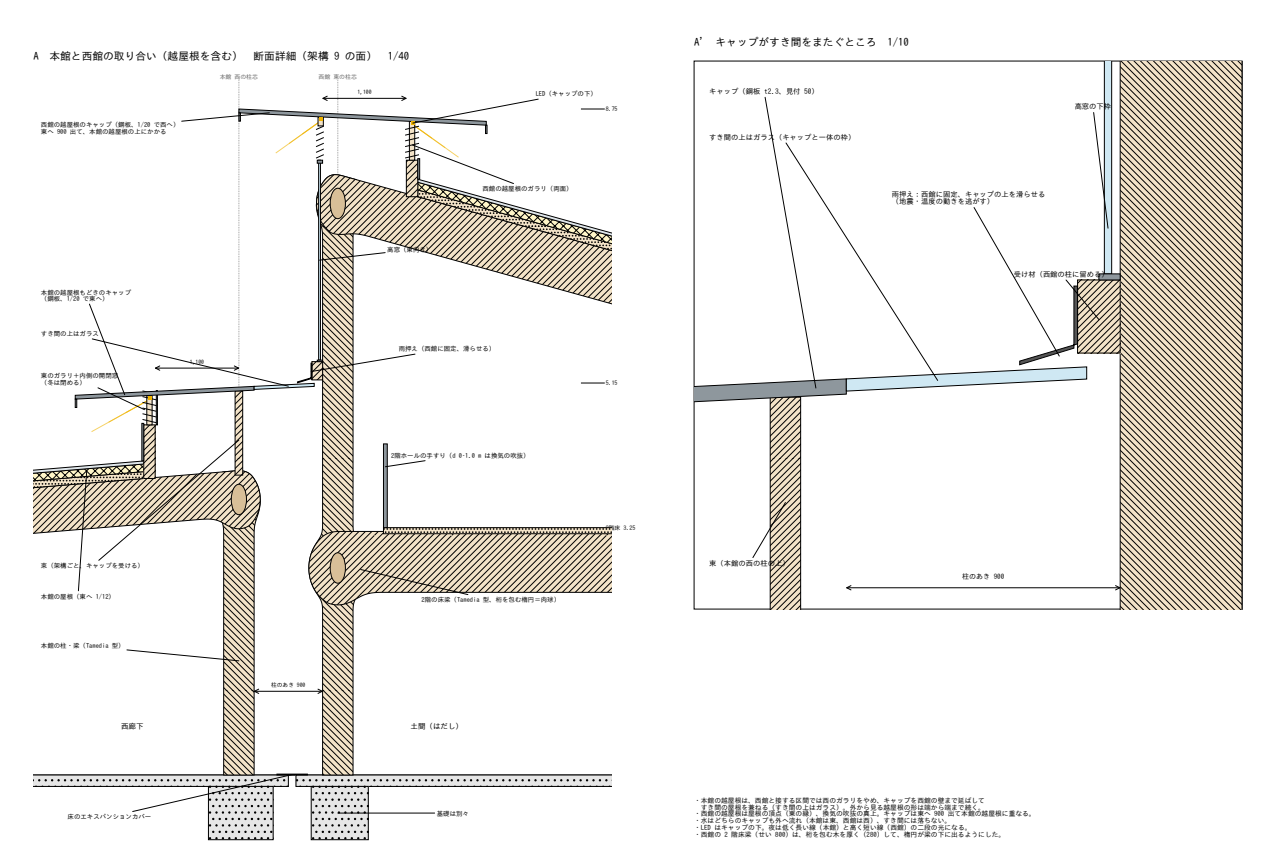

建築設計実習 II — I　2026.11.05　木田

［割付の注記］フォーカス：木造・パッシブ（床下・越屋根・光の筋）で空調を補う。東西に切った断面Cで空気の流れ。屋根材型の太陽光と蓄電池、資源のめぐり、時間（S&I）　／　目に入る順：断面C（昼と夏の夜の風）→ 運転表と配慮 → 縦断A → 断面B → 木の組み方・S&I